Samstag 14.02.2026

Veröffentlicht am 13.02.2026 um 17:00

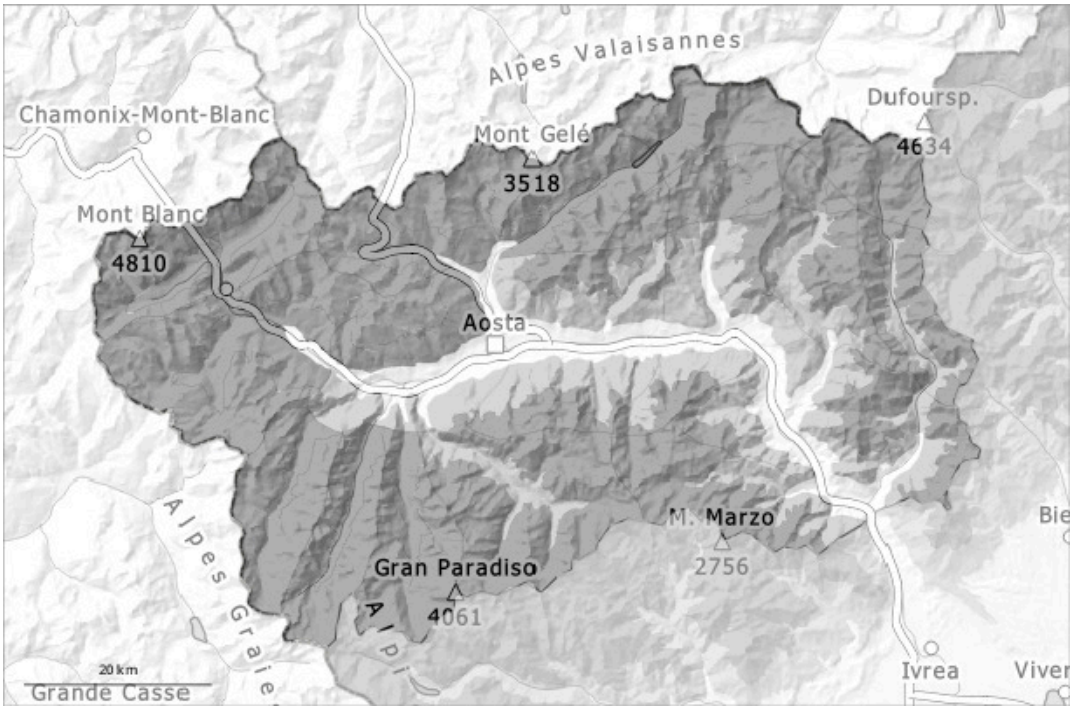

1	2	3	4	5
gering	mäßig	erheblich	groß	sehr groß

Gefahrenstufe 3 - Erheblich

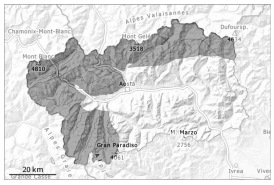

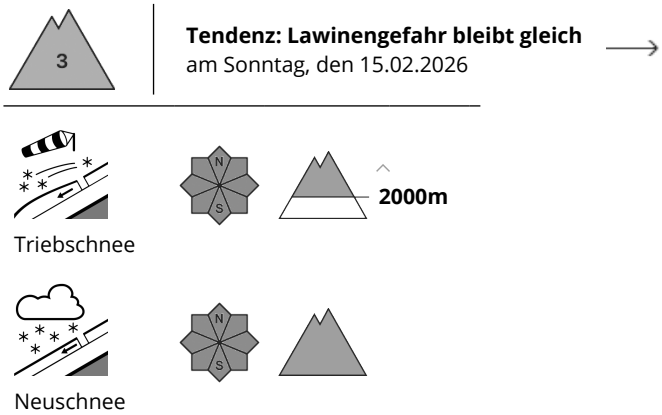

Die Lawinengefahr liegt im oberen Bereich der Gefahrenstufe 3, "erheblich". Für Touren und Variantenabfahrten abseits gesicherter Pisten sind die Verhältnisse heikel.

Viel Neuschnee und Triebschnee bleiben teilweise störanfällig.
In den Hauptniederschlagsgebieten sind die Gefahrenstellen häufiger und größer, vor allem entlang der Grenze zu Frankreich und entlang der Grenze zur Schweiz.
Lawinen können von einzelnen Wintersportlern ausgelöst werden. Vorsicht an steilen Hängen und in Rinnen, Mulden und hinter Geländekanten.
Besonders an sehr steilen Hängen und an Triebschneehängen sind weiterhin mittlere und vereinzelt große spontane Lawinen möglich. Die Lawinen können dort in tiefen Schichten ausgelöst werden und sehr groß werden.

Schneedecke

Gefahrenmuster gm.6: lockerer schnee und wind | gm.1: bodennahe schwachschicht

Seit Mittwoch fielen oberhalb von rund 1800 m 70 bis 110 cm Schnee, lokal auch mehr.
Bis Samstag fallen oberhalb von rund 1400 m 5 bis 10 cm Schnee. Die flächigen Triebschneeansammlungen werden teils überschneit und damit schwierig zu erkennen.
Die Wetterbedingungen führten zu einem ungünstigen Aufbau der Schneedecke. Der viele Neuschnee und die oft mächtigen Triebschneeansammlungen sind teils noch störanfällig. In Kamm- und Passlagen liegen je nach Windeinfluss sehr unterschiedliche Schneehöhen.
Seit Mittwoch sind viele große und vereinzelt sehr große spontane trockene Lawinen abgegangen.

Tendenz

Wind und Neuschnee. Die meteorologischen Bedingungen erlauben eine langsame Verfestigung der Schneedecke. Die Lawinengefahr bleibt bestehen.

Gefahrenstufe 3 - Erheblich

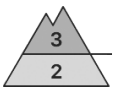

Tendenz: Lawinengefahr bleibt gleich
am Sonntag, den 15.02.2026

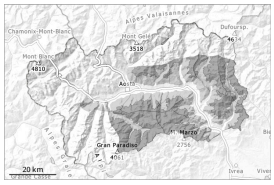

Triebschnee

Altschnee

Gefährlich sind Triebschneehänge, wo Schwachstellen im Altschnee vorhanden sind.

Mit Neuschnee und starkem Wind entstanden am Donnerstag störanfällige Triebschneeansammlungen. V.a. an extrem steilen Hängen und in Kammlagen sind aus noch nicht entladenen Einzugsgebieten weiterhin mittlere spontane Lawinen zu erwarten. Diese sind meist oberflächlich.
Die Lawinen können stellenweise im Altschnee ausgelöst werden und recht groß werden.
Schon einzelne Wintersportler können Lawinen auslösen. Fernauslösungen sind möglich.
Schwachschichten im Altschnee erfordern Vorsicht. Wummgeräusche und Risse beim Betreten der Schneedecke sind Alarmzeichen.

Schneedecke

Gefahrenmuster gm.6: lockerer schnee und wind | gm.1: bodennahe schwachschicht

Seit Dienstag fielen oberhalb von rund 1800 m 10 bis 30 cm Schnee, lokal auch mehr.
Bis Samstag fallen oberhalb von rund 1400 m 5 bis 10 cm Schnee, lokal bis zu 20 cm. Die Triebschneeansammlungen werden teils überschneit und damit schwierig zu erkennen.
Die Wetterbedingungen führten zu einem ungünstigen Aufbau der Schneedecke. Der starke Wind hat den Neuschnee intensiv verfrachtet.
In der Altschneedecke sind v.a. an West-, Nord- und Osthängen kantig aufgebaute Schwachschichten vorhanden.

Tendenz

Wind und Neuschnee. Die meteorologischen Bedingungen erlauben eine langsame Verfestigung der Schneedecke. Die Lawinengefahr bleibt bestehen.