Samstag 14.02.2026

Veröffentlicht am 13.02.2026 um 17:00

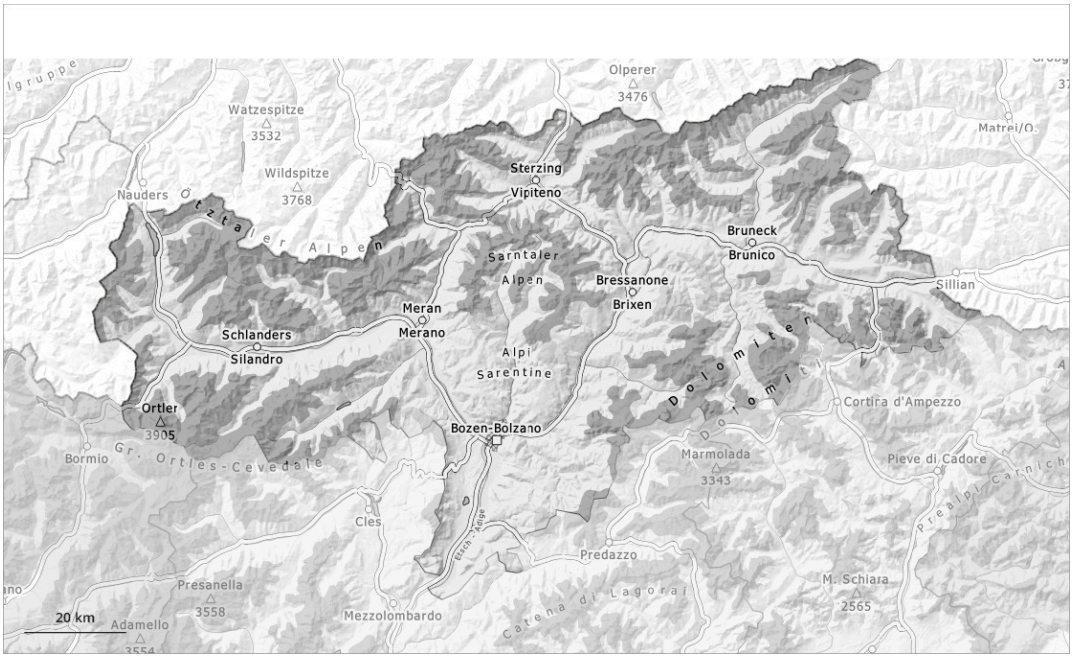

1	2	3	4	5
gering	mäßig	erheblich	groß	sehr groß

Gefahrenstufe 3 - Erheblich

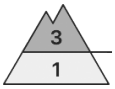

Waldgrenze

Tendenz: Lawinengefahr bleibt gleich
am Sonntag, den 15.02.2026

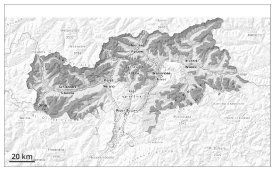

Altschnee

Waldgrenze

Triebschnee

2200m

Im selten befahrenen Gelände teils heimtückische Lawinensituation. Vorsicht vor Triebschnee und schwachem Altschnee.

Ausgeprägte Schwachschichten im Altschnee können besonders im selten befahrenen Gelände von einzelnen Wintersportlern leicht ausgelöst werden. Sie sind meist mittelgroß. Vorsicht vor allem an steilen West-, Nord- und Osthängen oberhalb der Waldgrenze. Die Gefahrenstellen sind schwer zu erkennen. Wummgeräusche und Risse beim Betreten der Schneedecke sind Alarmzeichen und weisen auf die Gefahr hin. Fernauslösungen sind vereinzelt möglich.

Mit starkem Wind entstanden in den letzten Tagen frische Triebschneeansammlungen, v.a. in Rinnen, Mulden und hinter Geländekanten oberhalb von rund 2200 m. Die weichen Triebschneeansammlungen sind nur klein aber teilweise störanfällig. Sie sind für Geübte gut erkennbar.

Schneedecke

Gefahrenmuster gm.1: bodennahe schwachschicht | gm.8: eingeschneiter oberflächenreif

Mit starkem Wind aus westlichen Richtungen entstanden in den letzten Tagen besonders in Rinnen und Mulden meist kleine Triebschneeansammlungen. Die Triebschneeansammlungen liegen teilweise auf Oberflächenreif.

Oberhalb der Waldgrenze: Die Schneedecke ist störanfällig. In der Altschneedecke sind ausgeprägte Schwachschichten vorhanden. Dies vor allem an West-, Nord- und Osthängen.

Unterhalb der Waldgrenze sowie steile Sonnenhänge: Die Schneedecke ist feucht, mit einer kaum tragfähigen Kruste an der Oberfläche.

Tendenz

Schwachschichten im Altschnee sind die Hauptgefahr.

> Bis Sonntag fällt vor allem im Norden etwas Schnee. Die meist kleinen Triebschneeansammlungen der letzten Tage werden teils überschneit und damit schwierig zu erkennen. Mit starkem Nordföhn entstehen im Süden weitere Triebschneeansammlungen.

Gefahrenstufe 2 - Mäßig

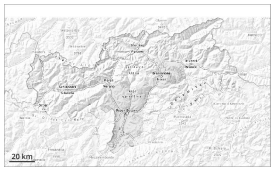

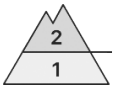

Waldgrenze

Tendenz: Lawinengefahr bleibt gleich
am Sonntag, den 15.02.2026

Altschnee

Waldgrenze

Triebschnee und schwachen Altschnee beachten.

Lawinen können von einzelnen Wintersportlern ausgelöst werden. Dies besonders an steilen Schattenhängen in Kammlagen, Rinnen und Mulden oberhalb der Waldgrenze. Mit teils starkem Wind entstehen frische Triebschneeansammlungen. Diese sind teils störanfällig. Lawinen sind teilweise mittelgroß.

Nebst der Verschüttungsgefahr sollte vor allem die Mitreiß- und Absturzgefahr beachtet werden. Es liegt für die Jahreszeit wenig Schnee.

Schneedecke

Gefahrenmuster gm.6: lockerer schnee und wind

Die frischen und älteren Triebschneeansammlungen liegen in der Höhe auf einer ungünstigen Altschneeoberfläche. In der Altschneedecke sind kantig aufgebaute Schwachschichten vorhanden.

Tiefe und mittlere Lagen: Die Schneedecke ist feucht, mit einer kaum tragfähigen Schmelzharschkruste an der Oberfläche.

Tendenz

Mäßige Lawinengefahr.