ICGC Institut Cartogràfic i Geològic de Catalunya

Servei Meteorològic de Catalunya meteo.cat

Boletín de peligro de aludes para el Pirineo de Catalunya
Del 13/02/2026 al 14/02/2026

(Válido fuera pistas de esquí y zonas no controladas)

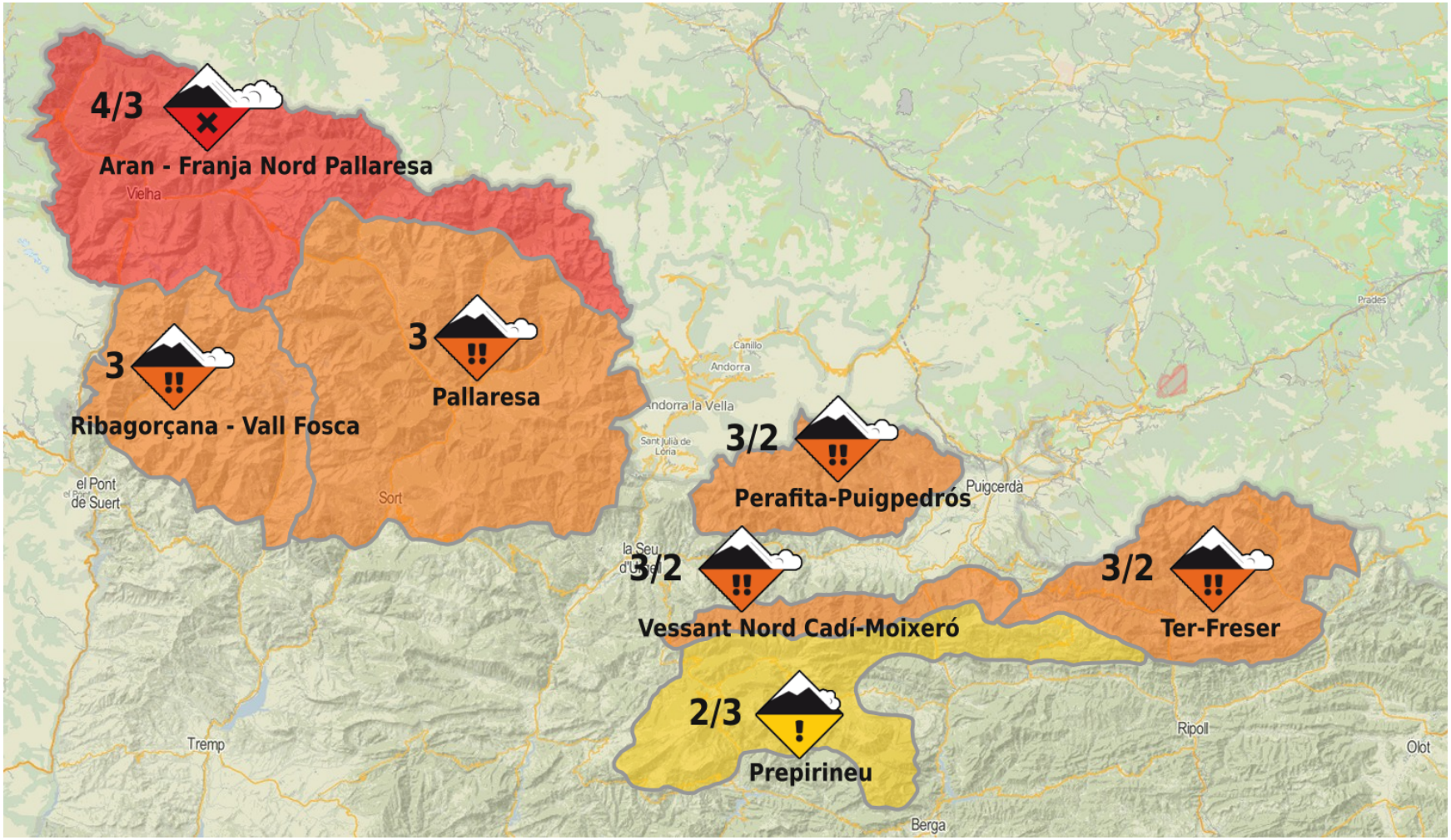

5 MUY FUERTE	4 FUERTE	3 NOTABLE	2 LIMITADO	1 DÉBIL

ICGC Institut Cartogràfic i Geològic de Catalunya

Servei Meteorològic de Catalunya

Boletín de peligro de aludes Aran - Franja Nord Pallaresa Del 13/02/2026 al 14/02/2026

(Válido fuera pistas de esquí y zonas no controladas)

FUERTE (4), sábado.
NOTABLE (3), viernes.

Situación primaria

Nieve venteada

Distribución

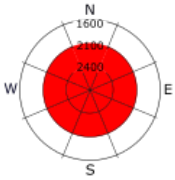

Tamaño

Origen

Tendencia

Situación secundaria

Nieve reciente

Distribución

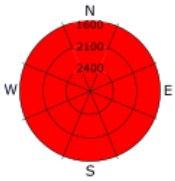

Tamaño

Origen

Tendencia

Estado del manto nivoso

El peligro irá en progresivo aumento, con la abundante nevada y el fuerte viento previstos. Los problemas predominantes serán las placas de viento y los aludes de nieve reciente. El viernes se han formado placas, generadas por el viento de Sur, sobre un nivel de cristales facetados, encima de las costras superficiales. Encima de estas placas se formarán nuevas, con la nevada y el viento previsto del N. El sábado, las placas serán muy frágiles y podrán caer de forma natural o al paso de un esquiador y generar aludes (con capacidad de enterrar a un grupo). Los lugares donde se formarán serán en cualquier orientación, sobre todo, en S, E y N, por encima del límite del bosque, bajo collados y crestas y en convexidades. Se esperan también aludes de nieve reciente, en terreno con fuerte inclinación, que podrán llegar hasta tamaño medio (con capacidad para enterrar a un montañero). Las condiciones serán peligrosas, con ventisca en altura. Se recomienda no circular por terreno avalanchoso

Distribución del manto nivoso

Hay nieve en el suelo a 1.400 m en Norte. El manto es esquiable por encima de unos 1.500 m en umbrías y a partir de los 1.800 m en solanas. Los espesores a unos 2.200 m rondan los 110-140 cm en el norte de Arán y 140-190 cm en la Franja Norte Pallaresa y en el sur de Aran, y son superiores a los normales por estas fechas.

Tendencia para las próximas 48-72h

Se mantendrá el viento en cota alta y caerán nuevos chubascos de nieve. Las placas se mantendrán reactivas. Peligro ESTACIONARIO o EN LEVE DESCENSO.

El próximo boletín será emitido el día 2026-02-14

5 MUY FUERTE	4 FUERTE	3 NOTABLE	2 LIMITADO	1 DÉBIL

EAWS EUROPEAN AVALANCHE WARNING SERVICES

ICGC Institut Cartogràfic i Geològic de Catalunya

Servei Meteorològic de Catalunya

Boletín de peligro de aludes Ribagorçana - Vall Fosca Del 13/02/2026 al 14/02/2026

(Válido fuera pistas de esquí y zonas no controladas)

NOTABLE (3).

Situación primaria

Nieve venteada

Distribución

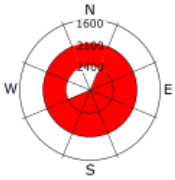

Tamaño

Origen

Tendencia

Situación secundaria

Nieve reciente

Distribución

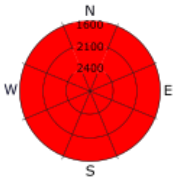

Tamaño

Origen

Tendencia

Estado del manto nivoso

El peligro irá al alza, con la nevada y el fuerte viento previsto. El problema predominante será, sobre todo, el de las placas de viento. El sábado nevará todo el día, con fuerte viento del Noroeste. Se formarán placas a sotavento, muy frágiles y podrán caer de forma natural o al paso de un esquiador y generar aludes de tamaño medio (con capacidad de enterrar a una persona). Los lugares donde se formarán serán en cualquier orientación, sobre todo, en Sur, Este y en Norte, por encima del límite del bosque, bajo collados y cordales y en terreno con convexidades. Además, se esperan también aludes de nieve reciente, en terreno con fuerte inclinación, que podrán llegar, en general, hasta tamaño pequeño y, localmente, medio (con capacidad para enterrar a un montañero). Las condiciones serán peligrosas, con ventisca en altura. Se recomienda mucha prudencia y experiencia si debe circularse por zonas no controladas.

Distribución del manto nivoso

Hay nieve en el suelo a 1.500 m. El manto es esquiable por encima de unos 1500-1600 m. Los grosores alcanzan los 130-160 cm. Estos valores son muy superiores a los normales en la época.

Tendencia para las próximas 48-72h

Se mantendrá el viento en cota alta y caerán nuevos chubascos de nieve. Las placas se mantendrán reactivas. Peligro ESTACIONARIO o EN LEVE DESCENSO.

El próximo boletín será emitido el día 2026-02-14

5 MUY FUERTE	4 FUERTE	3 NOTABLE	2 LIMITADO	1 DÉBIL

EAWS EUROPEAN AVALANCHE WARNING SERVICES

ICGC Institut Cartogràfic i Geològic de Catalunya

Servei Meteorològic de Catalunya

Boletín de peligro de aludes Pallaresa
Del 13/02/2026 al 14/02/2026

(Válido fuera pistas de esquí y zonas no controladas)

NOTABLE (3).

Situación primaria

Nieve venteada

Distribución

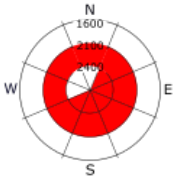

Tamaño

Origen

Tendencia

Situación secundaria

Nieve reciente

Distribución

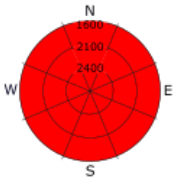

Tamaño

Origen

Tendencia

Estado del manto nivoso

El peligro irá al alza, con la nevada y el fuerte viento previsto. El problema predominante será, sobre todo, el de las placas de viento. El sábado nevará todo el día, con fuerte viento del Noroeste. Se formarán placas a sotavento, muy frágiles y podrán caer de forma natural o al paso de un esquiador y generar aludes de tamaño medio (con capacidad de enterrar a una persona). Los lugares donde se formarán serán en cualquier orientación, sobre todo, en Sur, Este y en Norte, por encima del límite del bosque, bajo collados y cordales y en terreno con convexidades. Además, se esperan también aludes de nieve reciente, en terreno con fuerte inclinación, que podrán llegar, en general, hasta tamaño pequeño y, localmente, medio (con capacidad para enterrar a un montañero). Las condiciones serán peligrosas, con ventisca en altura. Se recomienda mucha prudencia y experiencia si debe circularse por zonas no controladas.

Distribución del manto nivoso

Hay nieve en el suelo a 1.500 m. El manto es esquiable por encima de unos 1500-1600 m. Los grosores alcanzan los 130-160 cm. Estos valores son muy superiores a los normales en la época.

Tendencia para las próximas 48-72h

Se mantendrá el viento en cota alta y caerán nuevos chubascos de nieve. Las placas se mantendrán reactivas. Peligro ESTACIONARIO o EN LEVE DESCENSO.

El próximo boletín será emitido el día 2026-02-14

5 MUY FUERTE	4 FUERTE	3 NOTABLE	2 LIMITADO	1 DÉBIL

EAWS EUROPEAN AVALANCHE WARNING SERVICES

ICGC Institut Cartogràfic i Geològic de Catalunya

Servei Meteorològic de Catalunya

Boletín de peligro de aludes Perafita-Puigpedrós Del 13/02/2026 al 14/02/2026

(Válido fuera pistas de esquí y zonas no controladas)

NOTABLE (3), por encima de los 2.100 m. LIMITADO (2), en el resto.

Situación primaria

Nieve venteada

Distribución

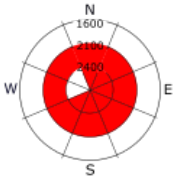

Tamaño

Origen

Tendencia

Estado del manto nivoso

El peligro irá al alza, con la nevada y el fuerte viento previsto. El problema predominante será, sobre todo, el de las placas de viento. El sábado nevará todo el día, con fuerte viento del Noroeste. Se formarán placas a sotavento, muy frágiles y podrán caer de forma natural o al paso de un esquiador y generar aludes de tamaño medio (con capacidad de enterrar a una persona). Los lugares donde se formarán serán en cualquier orientación, sobre todo, en Sur, Este y en Norte, por encima del límite del bosque, bajo collados y cordales y en terreno con convexidades. Además, se esperan también aludes de nieve reciente, en terreno con fuerte inclinación, que podrán llegar, en general, hasta tamaño pequeño y, localmente, medio (con capacidad para enterrar a un montañero). Las condiciones serán peligrosas, con ventisca en altura. Se recomienda mucha prudencia y experiencia si debe circularse por zonas no controladas.

Distribución del manto nivoso

Hay nieve en el suelo por encima de 1.400-1500 m. Sin embargo, el manto es esquiable por encima de 1.500-1.600 m. Los grosores alcanzan los 130-150 cm a 2.200 m. Son grosores muy por encima de los habituales por la época.

Tendencia para las próximas 48-72h

Se mantendrá el viento en cota alta y caerán nuevos chubascos de nieve. Las placas se mantendrán reactivas. Peligro ESTACIONARIO o EN LEVE DESCENSO.

El próximo boletín será emitido el día 2026-02-14

5 MUY FUERTE	4 FUERTE	3 NOTABLE	2 LIMITADO	1 DÉBIL

EAWS EUROPEAN AVALANCHE WARNING SERVICES

ICGC Institut Cartogràfic i Geològic de Catalunya

Servei Meteorològic de Catalunya meteo.cat

Boletín de peligro de aludes
Vessant Nord Cadí-Moixeró
Del 13/02/2026 al 14/02/2026

(Válido fuera pistas de esquí y zonas no controladas)

NOTABLE (3), por encima del límite del bosque. LIMITADO (2), en el resto.

Situación primaria

Nieve venteada

Distribución

Tamaño

Origen

Tendencia

Estado del manto nivoso

En las últimas horas ha nevado (5-10 cm) con viento del Sur. En cota alta se habrán formado placas y con el fuerte viento previsto se formarán nuevas, a sotavento del viento del oeste y del noroeste. El problema principal serán las placas de viento, que las encontraremos en laderas Este, Norte y Sur. Si se rompen las placas, al paso de un montañero, podrán generar aludes de pequeño tamaño, sin capacidad para enterrar a una persona y allí donde haya más acumulación, podrá caer algún alud de tamaño medio (que podría enterrar a un montañero), sobre todo en terreno trampa. Habrá que ir con copto en lo alto de las Canales del Cadí, donde podremos encontrar alguna nueva placa de reciente formación. Las condiciones serán delicadas, con ventisca en altura. Se recomienda mucha prudencia y experiencia si debe circularse por zonas no controladas.

Distribución del manto nivoso

Hay nieve desde 1.300 m. Norte y desde 1.400 a 1500 m. Sur, esquiable por encima de unos 1.500 m. Los grosores están alrededor de 150-170 cm a 2.200 m. Estos valores son muy excedentarios para la época del año.

Tendencia para las próximas 48-72h

Se mantendrá el viento en cota alta y caerán nuevos aguaceros de nieve. Las placas se mantendrán reactivas. Peligro ESTACIONARIO o EN LEVE DESCENSO.

El próximo boletín será emitido el día 2026-02-14

5 MUY FUERTE	4 FUERTE	3 NOTABLE	2 LIMITADO	1 DÉBIL

EAWS EUROPEAN AVALANCHE WARNING SERVICES

ICGC Institut Cartogràfic i Geològic de Catalunya

Servei Meteorològic de Catalunya

Boletín de peligro de aludes Prepirineu
Del 13/02/2026 al 14/02/2026

(Válido fuera pistas de esquí y zonas no controladas)

LIMITADO (2), por encima del límite del bosque. NOTABLE (3), en el resto.

Situación primaria

Nieve venteada

Distribución

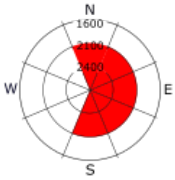

Tamaño

Origen

Tendencia

Estado del manto nivoso

En las últimas horas ha nevado (5-10 cm) con viento del Sur. En cota alta se habrán formado placas y con el fuerte viento previsto se formarán nuevas, a sotavento del viento del oeste y del noroeste. El problema principal serán las placas de viento, que las encontraremos en laderas Este, Norte y Sur. Si se rompen las placas, al paso de un montañero, podrán generar aludes de pequeño tamaño, sin capacidad para enterrar a una persona y allí donde haya más acumulación, podrá caer algún alud de tamaño medio (que podría enterrar a un montañero), sobre todo en terreno trampa. Las condiciones serán delicadas, con ventisca en altura. Se recomienda mucha prudencia y experiencia si debe circularse por zonas no controladas.

Distribución del manto nivoso

Hay nieve desde 1400-1500 m. El manto es esquiable a partir de 1600 m. Los grosores están alrededor de 110-130 cm a unos 2.200 m y son superiores a los habituales.

Tendencia para las próximas 48-72h

Se mantendrá el viento en cota alta y caerán nuevos aguaceros de nieve. Las placas se mantendrán reactivas. Peligro ESTACIONARIO o EN LEVE DESCENSO.

El próximo boletín será emitido el día 2026-02-14

5 MUY FUERTE	4 FUERTE	3 NOTABLE	2 LIMITADO	1 DÉBIL

EAWS EUROPEAN AVALANCHE WARNING SERVICES

ICGC Institut Cartogràfic i Geològic de Catalunya

Servei Meteorològic de Catalunya

Boletín de peligro de aludes Ter-Freser
Del 13/02/2026 al 14/02/2026

(Válido fuera pistas de esquí y zonas no controladas)

NOTABLE (3), por encima de los 2.100 m. LIMITADO (2), en el resto.

Situación primaria

Nieve venteada

Distribución

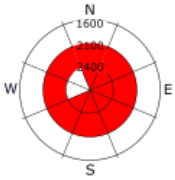

Tamaño

Origen

Tendencia

Estado del manto nivoso

El fuerte viento del noroeste transportará la nieve seca existente actualmente a cota alta y moverá también la que debe caer en las próximas horas, generando nuevas placas. Por sábado, por tanto, el problema predominante será el de las placas de viento. Se formarán placas a sotavento, muy frágiles y podrán caer de forma natural o al paso de un esquiador y generar aludes de hasta tamaño medio (con capacidad de enterrar a una persona). Los lugares donde se formarán serán en cualquier orientación, pero sobre todo, en Sur y Este, por encima del límite del bosque, bajo collados y cordales y en terreno con convexidades. Las condiciones serán peligrosas, con ventisca violenta en altura. Se recomienda mucha prudencia y experiencia si debe circularse por zonas no controladas.

Distribución del manto nivoso

El manto nivoso presenta grosores muy excedentarios para la época del año. En lugares no afectados por el viento, los espesores oscilan entre 100-140 cm a unos 2.000 m, siendo esquiable a partir de unos 1.500 m.

Tendencia para las próximas 48-72h

Se mantendrá el viento en cota alta y caerán nuevos chubascos de nieve. Las placas se mantendrán reactivas. Peligro ESTACIONARIO o EN LEVE DESCENSO.

El próximo boletín será emitido el día 2026-02-14

5 MUY FUERTE	4 FUERTE	3 NOTABLE	2 LIMITADO	1 DÉBIL

EAWS EUROPEAN AVALANCHE WARNING SERVICES