BUTLLETÍ DEL PERILL D'ALLAUS DEL PRINCIPAT D'ANDORRA

Elaborat el 13/02/2026 13:12
Propera actualització 13/02/2026 a les 16h

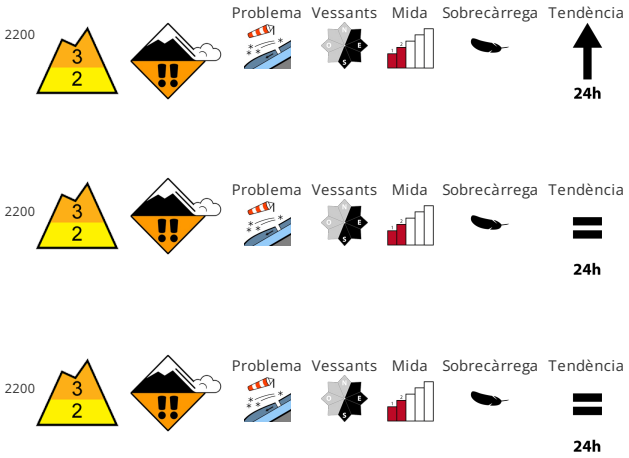

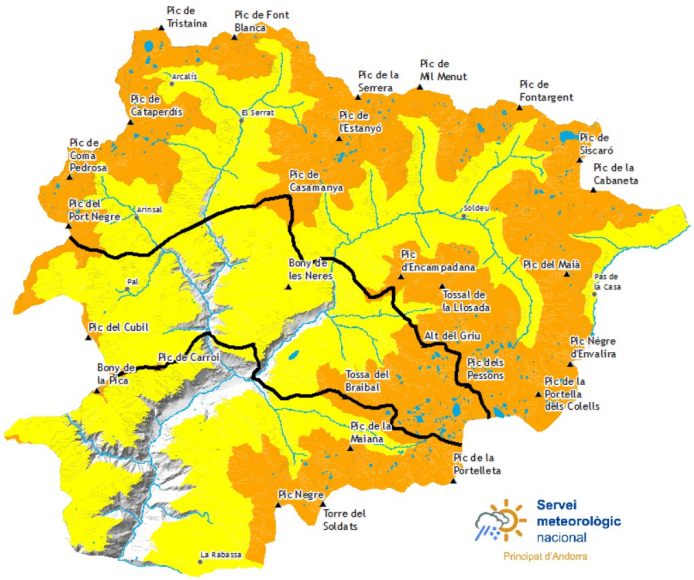

ESTABILITAT DEL MANTELL NIVAL

El vent amb ratxes fortes transportarà intensament la neu recent. Especialment prop dels cims les plaques de vent, fins ara petites, augmentaran de mida. Als vessants prop de les carenes orientats a nord-est, est i sud-est són possibles allaus naturals de mida petita a mitjana. A cotes baixes i mitges :. A causa de la superfície dura del mantell de neu hi ha el perill de relliscar i caure fins i tot en vessants moderadament inclinats. Les excursions de muntanya i les activitats forapista requereixen experiència en l'avaluació del perill d'allaus i una curosa sel·lecció de l'itinerari. Es recomana mantenir la distància entre els components. Els indrets perillosos són difícils de reconèixer amb mala visibilitat.

QUALITAT DE LA NEU

El dijous el vent ha estat en molts sectors de fort a molt fort. Durant la nit caurà neu per sobre dels 1300 m aproximadament. A cotes altes i als vessants orientats a nord-est, est i sud-est :. Amb la neu recent i el vent les plaques de vent augmentaran de mida. A cotes baixes :. La superfície del mantell de neu es regelarà per formar una crosta portant.

GRUIXOS DEL MANTELL NIVAL FORA DE PISTA

Zona nord		Gruix neu		
Mantell Nival		1500m	2000m	2500m
N	1300 m	50 cm	150 cm	200 cm
S	1400 m	30 cm	100 cm	150 cm

Zona centre		Gruix neu		
Mantell Nival		1500m	2000m	2500m
N	1300 m	30 cm	150 cm	200 cm
S	1400 m	10 cm	100 cm	150 cm

Zona sud		Gruix neu		
Mantell Nival		1500m	2000m	2500m
N	1300 m	30 cm	120 cm	150 cm
S	1400 m	10 cm	60 cm	100 cm

Govern d'Andorra

Aquest butlletí ha estat elaborat seguint les normes i recomanacions de l'**European Avalanche Warning Services**, del qual el **Servei meteorològic Nacional** n'és membre

BUTLLETÍ DEL PERILL D'ALLAUS DEL PRINCIPAT D'ANDORRA

Servei meteorològic nacional
Principat d'Andorra

Informació detallada per espais naturals protegits

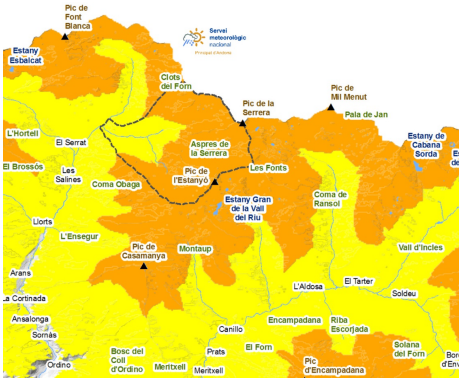

SORTENY

Amb el descens de la cota de neu i el vent encara moderat les plaques de vent augmentaran de mida. Haurem de desconfiar dels indrets amb component est, ja que poden ser amagar plaques de vent. A causa d´aquest vent, la superfície de la neu té textures molt diferents.

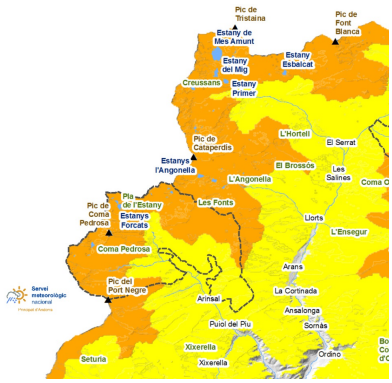

COMAPEDROSA

A sobre de la neu dura s´han format plaques de vent que poden ser sensibles a sobrecàrregues als vessants est. A cotes baixes, prop d´Arinsal, la neu està més regelada.

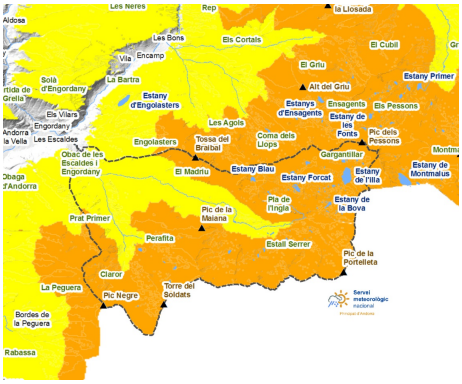

MADRIU-PERAFITA-CLAROR

La neu humida del fons de la vall es regelarà i accentuarà el perill de relliscada, fins i tot en terreny moderadament inclinat. Com a tot el país, prop dels cims el vent crearà noves acumulacions als vessants amb orientació a est.

Govern d'Andorra

EAWS
EUROPEAN AVALANCHE WARNING SERVICES

Aquest butlletí ha estat elaborat seguint les normes i recomanacions de l'**European Avalanche Warning Services**, del qual el **Servei meteorològic Nacional** n'és membre

BUTLLETÍ DEL PERILL D'ALLAUS DEL PRINCIPAT D'ANDORRA

Servei meteorològic nacional
Principat d'Andorra

Gruixos de neu nova dels darrers dies (de les últimes 24h mesurat a les 06:00h UTC)

	09/02/2026	10/02/2026	11/02/2026	12/02/2026
FEDA (Central)	0 cm	0 cm	0 cm	0 cm
Engolasters - FEDA	0 cm	0 cm	0 cm	0 cm
Bony de les Neres	11 cm	0 cm	0 cm	0 cm
Sorteny	22 cm	0 cm	17 cm	0 cm
Les Fonts d'Arinsal	15 cm	12 cm	9 cm	0 cm
Perafita	8 cm	0 cm	0 cm	0 cm
Tossa Espiolets	5 cm	0 cm	0 cm	0 cm
Grau Roig - FEDA	13 cm	0 cm	9 cm	0 cm
Fontverd	7 cm	0 cm	0 cm	0 cm
Ransol - FEDA	4 cm	0 cm	0 cm	0 cm
Setúria	12 cm	0 cm	0 cm	0 cm
Caborreu	6 cm	0 cm	9 cm	0 cm
Envalira Antenes	18 cm	0 cm	0 cm	0 cm
Vall del Riu FEDA	7 cm	7 cm	0 cm	1 cm