BUTLLETÍ DEL PERILL D'ALLAUS DEL PRINCIPAT D'ANDORRA

Préparé le 13/02/2026 13:13
Prochaine mise à jour le 13/02/2026 à 16h

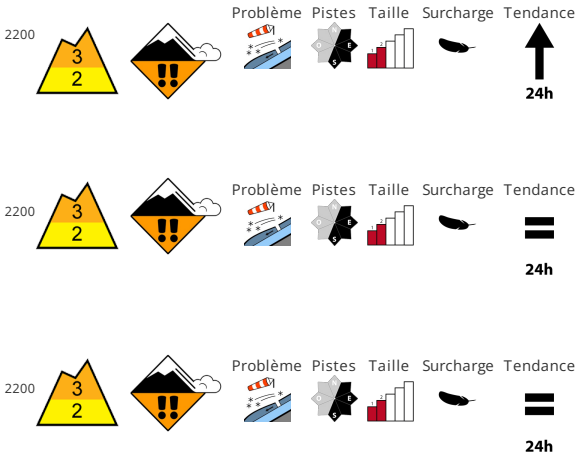

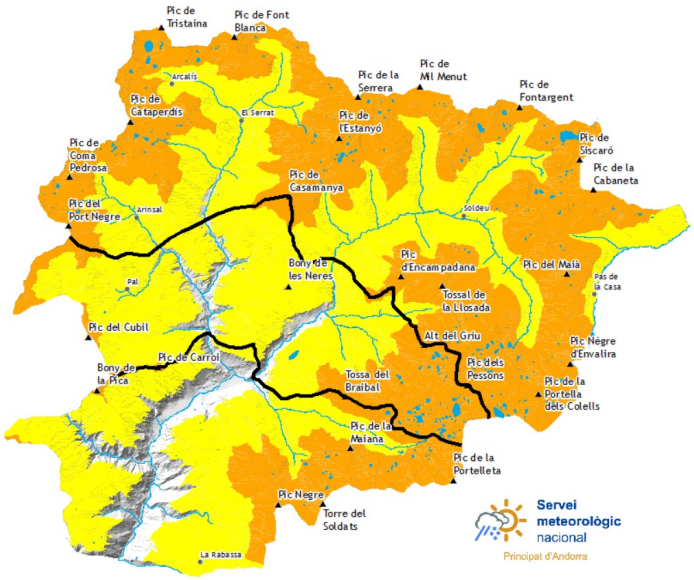

STABILITÉ DU MANTEAU NEIGEUX

Le vent parfois fort transporte intensivement la neige fraîche.. Les accumulations de neige soufflée auparavant petites se développent spécialement à proximité des sommets. Des avalanches spontanées de petite à moyenne taille sont possibles sur les pentes proches des crêtes exposées au nord-est , à l'est et au sud-est. À basses et moyennes altitudes (-):. Sur la surface de neige dure il existe également dans des terrains moyennement raides un risque de chute.. Les randonnées et descentes hors-piste demandent de l' expérience dans l'évaluation du danger d'avalanche et un choix prudent des itinéraires. Des distances de délestage sont recommandées.. Les endroits dangereux sont à peine identifiables par mauvaise visibilité..

QUALITÈ DE LA NEIGE

Jeudi le vent à soufflé en général fortement à tempétueusement. Pendant la nuit il tombera de la neige au-dessus d'environ 1300 m. À haute altitude et sur les pentes exposées au nord-est , à l'est et au sud-est (-):. Les accumulations de neige soufflée se développent avec la neige fraîche et le vent. À basse altitude (-):. La surface de la neige regèle et devient porteuse.

EPAISSEUR DE NEIGE HORS PISTE

Zone nord		Epaisseur de neige		
Nival manteau		1500m	2000m	2500m
N	1300 m	50 cm	150 cm	200 cm
S	1400 m	30 cm	100 cm	150 cm

Zone centre		Epaisseur de neige		
Nival manteau		1500m	2000m	2500m
N	1300 m	30 cm	150 cm	200 cm
S	1400 m	10 cm	100 cm	150 cm

Zone sud		Epaisseur de neige		
Nival manteau		1500m	2000m	2500m
N	1300 m	30 cm	120 cm	150 cm
S	1400 m	10 cm	60 cm	100 cm

BUTLLETÍ DEL PERILL D'ALLAUS DEL PRINCIPAT D'ANDORRA

Servei meteorològic nacional
Principat d'Andorra

Des informations détaillées par espace naturel protégé

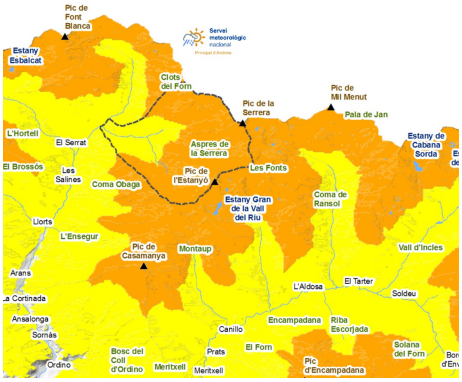

SORTENY

Avec la baisse du niveau de neige et le vent toujours modéré, les plaques de vent augmenteront en taille. Il faudra se méfier des endroits avec une composante est, car ils peuvent cacher des plaques de vent. A cause de ce vent, la surface de la neige présente des textures très différentes. , , , , ,

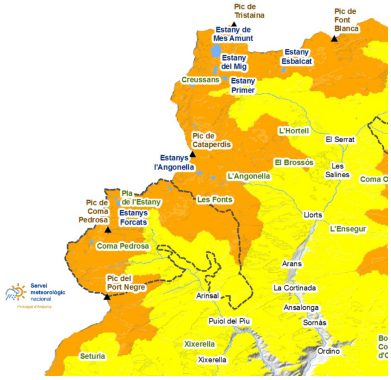

COMAPEDROSA

Au-dessus de la neige dure se sont formées des plaques de vent qui peuvent être sensibles aux surcharges sur les versants est. À basse altitude, près d'Arinsal, la neige est plus gelée. , , ,

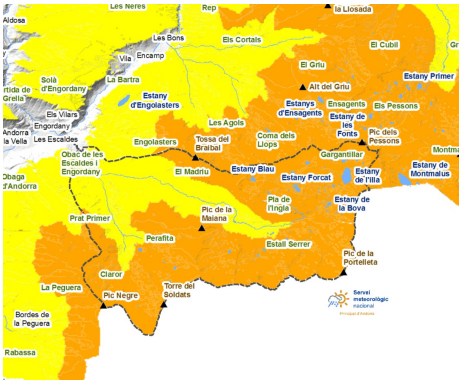

MADRIU-PERAFITA-CLAROR

La neige mouillée au fond de la vallée gèlera et augmentera le risque de glissade, même sur un terrain modérément en pente. Comme dans tout le pays, près des sommets, le vent créera de nouvelles accumulations sur les versants orientés à l'est. , , ,

Govern d'Andorra

EAWS
EUROPEAN AVALANCHE WARNING SERVICES

Aquest butlletí ha estat elaborat seguint les normes i recomanacions de l'**European Avalanche Warning Services**, del qual el **Servei meteorològic Nacional** n'és membre

BUTLLETÍ DEL PERILL D'ALLAUS DEL PRINCIPAT D'ANDORRA

Servei meteorològic nacional
Principat d'Andorra

Couche de neige fraiche des derniers jours (De 24 h mesurée à 06:00 h UTC)

	09/02/2026	10/02/2026	11/02/2026	12/02/2026
FEDA (Central)	0 cm	0 cm	0 cm	0 cm
Engolasters - FEDA	0 cm	0 cm	0 cm	0 cm
Bony de les Neres	11 cm	0 cm	0 cm	0 cm
Sorteny	22 cm	0 cm	17 cm	0 cm
Les Fonts d'Arinsal	15 cm	12 cm	9 cm	0 cm
Perafita	8 cm	0 cm	0 cm	0 cm
Tossa Espiolets	5 cm	0 cm	0 cm	0 cm
Grau Roig - FEDA	13 cm	0 cm	9 cm	0 cm
Fontverd	7 cm	0 cm	0 cm	0 cm
Ransol - FEDA	4 cm	0 cm	0 cm	0 cm
Setúria	12 cm	0 cm	0 cm	0 cm
Caborreu	6 cm	0 cm	9 cm	0 cm
Envalira Antenes	18 cm	0 cm	0 cm	0 cm
Vall del Riu FEDA	7 cm	7 cm	0 cm	1 cm