MINISTERO DELLA DIFESA

meteomont Servizio Nazionale di previsione neve e valanghe

EAWS EUROPEAN AVALANCHE WARNING SERVICES

CARABINIERI

ALPI OROBICHE

Bollettino Valanghe N. 344/2026 del 13/02/2026 ore 14.00
Validità 48 ore prossima emissione 14/02/2026

A cura del Servizio METEOMONT dell'ARMA dei CARABINIERI
In collaborazione con Servizio Meteorologico dell'Aeronautica militare

SITUAZIONE alle 14:00 del 13/02/2026

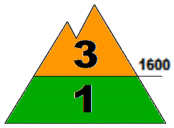

SITUAZIONE TIPO: strato debole persistente basale.



SITUAZIONE TIPO: situazione primaverile.

Quota neve (mslm)	Nord	Sud
	1300 - 1400	1300 - 1500

Altezza Neve (cm)	Neve al suolo	Neve Fresca	Quota (mslm)
	115	0	2080
	015	0	1300

VALANGHE OSSERVATE: Nessuna valanga.

PREVISIONI 14/02/2026

GRADO DI PERICOLO: MARCATO 3

SITUAZIONE TIPO: strato debole persistente basale.

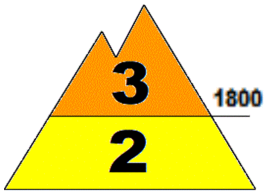

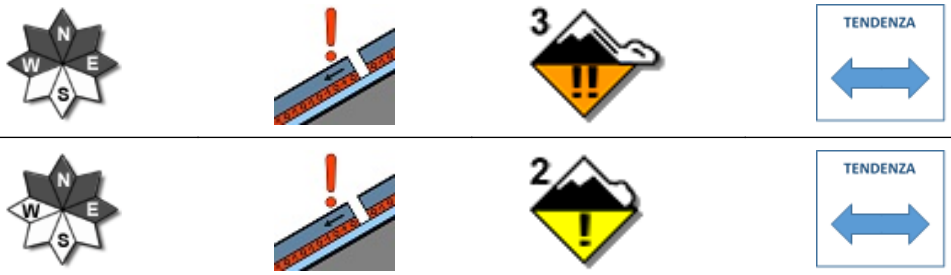

SITUAZIONE TIPO: passaggio da poca a molta neve.

MANTO NEVOSO: La stabilità del manto nevoso è scarsa su molti punti (aree) per versanti da ovest a est al di sopra di 1800 mslm, possibili valanghe di dimensioni medie.
La stabilità del manto nevoso è scarsa su alcuni punti (aree) per versanti in ombra al di sotto di 1800 mslm, possibili valanghe di dimensioni medie.

AVVERTENZE

In considerazione delle avverse condizioni meteorologiche previste, e della scarsa visibilità, risulterà difficoltosa l'individuazione dell'itinerario e della valutazione del singolo pendio.

SCALA EUROPEA DEL GRADO DI PERICOLO VALANGHE

LEGENDA PROBLEMA

Bollettino realizzato su scala sinottica-regionale (standard EAWS). La sua valutazione non può escludere in alcun modo la necessità di una seria e capace valutazione locale del pericolo (singolo pendio) che può essere anche sensibilmente diverso. Le previsioni meteorologiche sono relative all'orario UTC (per l'Italia +1 in inverno e +2 in estate).

MINISTERO DELLA DIFESA

meteomont
Servizio Nazionale di previsione neve e valanghe

EAWS EUROPEAN AVALANCHE WARNING SERVICES

CARABINIERI

ALPI OROBICHE

PREVISIONE METEO

Quota		14/02/2026 h6:00	14/02/2026 h12:00	14/02/2026 h18:00
1000	Venti	02 Nodi da N-Est	01 Nodi da Nord	02 Nodi da Nord
	Temperature	-02 °C	+01 °C	+01 °C
	Temp.percepita	-2 °C	1 °C	1 °C
2000	Venti	05 Nodi da Est	03 Nodi da N-Est	06 Nodi da Nord
	Temperature	-03 °C	+00 °C	+00 °C
	Temp.percepita	-7 °C	-2 °C	-4 °C
3000	Venti	14 Nodi da S-Est	08 Nodi da Est	11 Nodi da Nord
	Temperature	-09 °C	-08 °C	-08 °C
	Temp.percepita	-18 °C	-14 °C	-15 °C
Zero termico		1400-1600 m.	1700-1900 m.	1700-1900 m.
Fenomeno			—	
Stato del cielo				

LEGENDA FENOMENI

— Assenza Fenomeni · Nebbia · Foschia · Pioggia debole · Pioggia moderata · Pioggia forte · Temporali

Nevicata debole · Nevicata moderata · Nevicata forte

STATO DEL CIELO

Sereno · Poco nuvoloso · Nuvoloso · Molto nuvoloso · Coperto

Parametri meteonivometrici registrati presso i campi di rilevamento il 13/02/2026.

Località	Comune	Quota (m.s.l.m.)	Altezza neve (cm)	Neve caduta nelle 24 ore (cm)	Temp. Min (°C)	Temp. Max (°C)	Condizioni del tempo
CIMA VALZELLI	Castione della Presolana (BG)	1622	56	N.P.	N.P.	N.P.	Assenza di precipitazioni
VODALA	Gromo (BG)	1635	66	0	-1	+3	Assenza di precipitazioni
QUARTA BAITA	Foppolo (BG)	1760	63	0	-4	+7	Assenza di precipitazioni
CIMA BIANCA	Colere (BG)	2080	115	3	-4	-1	Assenza di precipitazioni

(*) Rilievi fuori campo

L'INFORMAZIONE E' PREVENZIONE - LEGGI L'ATTUALE GRADO DI PERICOLO VALANGHE!

IL CAPO DEL CENTRO NAZIONALE METEOMONT
(Ten. Col. RFI Emanuela Gini)
FIRMA AUTOGRAFA OMESSA AI SENSI
DELL'ART.3 DEL D.LGS N.39/1993

Bollettino realizzato su scala sinottica-regionale (standard EAWS). La sua valutazione non può escludere in alcun modo la necessità di una seria e capace valutazione locale del pericolo (singolo pendio) che può essere anche sensibilmente diverso. Le previsioni meteorologiche sono relative all'orario UTC (per l'Italia +1 in inverno e +2 in estate).