MINISTERO DELLA DIFESA

meteomont
Servizio Nazionale di previsione neve e valanghe

EAWS EUROPEAN AVALANCHE WARNING SERVICES

CARABINIERI

AERONAUTICA MILITARE SERVIZIO METEOROLOGICO

# GRAN SASSO EST - LAGA EST

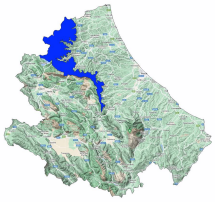

Bollettino Valanghe N. 333/2026 del 13/02/2026 ore 14.00
Validità 48 ore prossima emissione 14/02/2026

**A cura del Servizio METEOMONT dell'ARMA dei CARABINIERI**
**In collaborazione con Servizio Meteorologico dell'Aeronautica militare**

## SITUAZIONE alle 14:00 del 13/02/2026

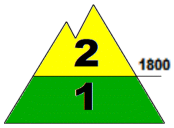


**SITUAZIONE TIPO: neve a debole coesione e vento.**




**SITUAZIONE TIPO: situazione primaverile.**

| Quota neve (mslm) | Nord | Sud |
|---|---|---|
| | 1400 - 1500 | 1600 - 1800 |

| Altezza Neve (cm) | Neve al suolo | Neve Fresca | Quota (mslm) |
|---|---|---|---|
| | 006 | 000 | 1400 |
| | 000 | 000 | 1016 |

**VALANGHE OSSERVATE: Nessuna valanga.**

## PREVISIONI 14/02/2026

## GRADO DI PERICOLO: MODERATO 2

## SITUAZIONE TIPO: neve a debole coesione e vento.

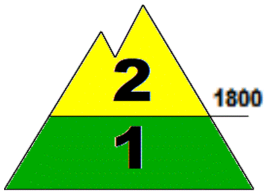


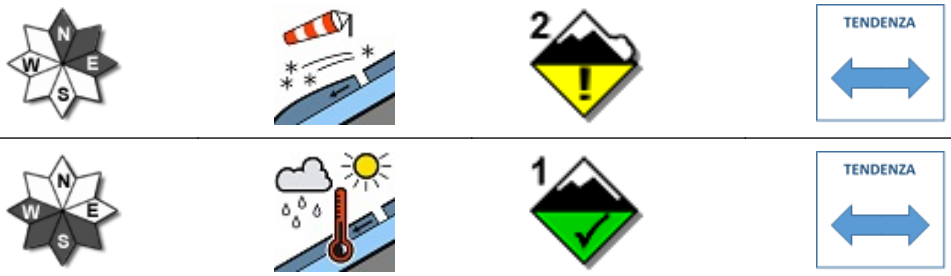


## SITUAZIONE TIPO: situazione primaverile.

**MANTO NEVOSO: La stabilità del manto nevoso è discreta su alcuni punti (aree) per versanti nord orientali al di sopra di 1800 mslm, possibili valanghe di dimensioni medie.**
**La stabilità del manto nevoso è discreta su alcuni punti (aree) per versanti al sole al di sotto di 1800 mslm, possibili valanghe di dimensioni piccole.**

## AVVERTENZE

Il rialzo termico diurno richiede un'attenta valutazione temporale dell'escursione che eviti l'attraversamento di pendii ripidi nelle ore più calde della giornata.

## SCALA EUROPEA DEL GRADO DI PERICOLO VALANGHE

## LEGENDA PROBLEMA

**Bollettino realizzato su scala sinottica-regionale (standard EAWS). La sua valutazione non può escludere in alcun modo la necessità di una seria e capace valutazione locale del pericolo (singolo pendio) che può essere anche sensibilmente diverso. Le previsioni meteorologiche sono relative all'orario UTC (per l'Italia +1 in inverno e +2 in estate).**

**Bollettino sottoposto a processi di: Acquisizione e controllo del C-Sifa e della rete di Osservatori e Esperti - Validazione del Previsore di turno - Certificazione della Sezione Meteomont.**

MINISTERO DELLA DIFESA

meteomont
Servizio Nazionale di previsione neve e valanghe

EAWS EUROPEAN AVALANCHE WARNING SERVICES

CARABINIERI

# GRAN SASSO EST - LAGA EST

## PREVISIONE METEO

| Quota | | 14/02/2026 h6:00 | 14/02/2026 h12:00 | 14/02/2026 h18:00 |
|---|---|---|---|---|
| 1000 | Venti | 05 Nodi da Sud | 05 Nodi da Sud | 01 Nodi da Sud |
| | Temperature | +03 °C | +04 °C | +04 °C |
| | Temp.percepita | 0 °C | 2 °C | 4 °C |
| 2000 | Venti | 20 Nodi da Sud | 16 Nodi da Sud | 04 Nodi da Sud |
| | Temperature | -01 °C | -01 °C | +00 °C |
| | Temp.percepita | -8 °C | -8 °C | -3 °C |
| 3000 | Venti | 20 Nodi da S-Ovest | 14 Nodi da S-Ovest | 05 Nodi da S-Ovest |
| | Temperature | -07 °C | -07 °C | -07 °C |
| | Temp.percepita | -16 °C | -15 °C | -11 °C |
| Zero termico | | 1700-1900 m. | 1800-2000 m. | 1900-2100 m. |
| Fenomeno | | | | — |
| Stato del cielo | | | | |

## LEGENDA FENOMENI

— Assenza Fenomeni · Nebbia · Foschia · Pioggia debole · Pioggia moderata · Pioggia forte · Temporali

Nevicata debole · Nevicata moderata · Nevicata forte

## STATO DEL CIELO

Sereno · Poco nuvoloso · Nuvoloso · Molto nuvoloso · Coperto

## Parametri meteonivometrici registrati presso i campi di rilevamento il 13/02/2026.

| Località | Comune | Quota (m.s.l.m.) | Altezza neve (cm) | Neve caduta nelle 24 ore (cm) | Temp. Min (°C) | Temp. Max (°C) | Condizioni del tempo |
|---|---|---|---|---|---|---|---|
| FAVACCHIOLE | Crognaleto (TE) | 1016 | 0 | 0 | +3 | +7 | Assenza di precipitazioni |
| PRATO SELVA | Fano Adriano (TE) | 1355 | 0 | 0 | +2 | +5 | Assenza di precipitazioni |
| RIGOPIANO | Farindola (PE) | 1135 | 0 | 0 | +1 | +9 | Assenza di precipitazioni |
| PIANO SAN PIETRO | Isola del Gran Sasso d'Italia (TE) | 950 | 0 | 0 | N.P. | N.P. | Assenza di precipitazioni |
| PRATI DI TIVO | Pietracamela (TE) | 1380 | 0 | 0 | +2 | +5 | Assenza di precipitazioni |
| CEPPO | Rocca Santa Maria (TE) | 1349 | 0 | 0 | +2 | +5 | Assenza di precipitazioni |
| SAN PAOLO | Acquasanta Terme (AP) | 960 | 0 | 0 | +3 | +8 | Assenza di precipitazioni |
| COLLE SAN GIACOMO | Civitella del Tronto (TE) | 1075 | 0 | 0 | +2 | +10 | Assenza di precipitazioni |

**(*) Rilievi fuori campo**

**L'INFORMAZIONE E' PREVENZIONE - LEGGI L'ATTUALE GRADO DI PERICOLO VALANGHE!**

**IL CAPO DEL CENTRO NAZIONALE METEOMONT**
**(Ten. Col. RFI Emanuela Gini)**
**FIRMA AUTOGRAFA OMESSA AI SENSI**
**DELL'ART.3 DEL D.LGS N.39/1993**

**Bollettino realizzato su scala sinottica-regionale (standard EAWS). La sua valutazione non può escludere in alcun modo la necessità di una seria e capace valutazione locale del pericolo (singolo pendio) che può essere anche sensibilmente diverso. Le previsioni meteorologiche sono relative all'orario UTC (per l'Italia +1 in inverno e +2 in estate).**