MINISTERO DELLA DIFESA

meteomont
Servizio Nazionale di previsione neve e valanghe

EAWS EUROPEAN AVALANCHE WARNING SERVICES

CARABINIERI

AERONAUTICA MILITARE SERVIZIO METEOROLOGICO

GRAN SASSO OVEST

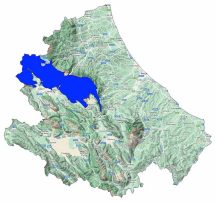

Bollettino Valanghe N. 334/2026 del 13/02/2026 ore 14.00
Validità 48 ore prossima emissione 14/02/2026

A cura del Servizio METEOMONT dell'ARMA dei CARABINIERI
In collaborazione con Servizio Meteorologico dell'Aeronautica militare

SITUAZIONE alle 14:00 del 13/02/2026

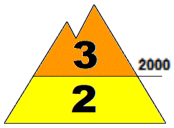

SITUAZIONE TIPO: neve a debole coesione e vento.

SITUAZIONE TIPO: neve a debole coesione e vento.

	Nord	Sud
Quota neve (mslm)	*1500 - 1600*	*1700 - 1800*

	Neve al suolo	Neve Fresca	Quota (mslm)
Altezza Neve (cm)	*280*	*010*	*2181*
	000	*000*	*1400*

VALANGHE OSSERVATE: Numerose valanghe di medie dimensioni, Valanghe a lastroni di superficie.

PREVISIONI 14/02/2026

GRADO DI PERICOLO: MARCATO 3

SITUAZIONE TIPO: neve a debole coesione e vento.

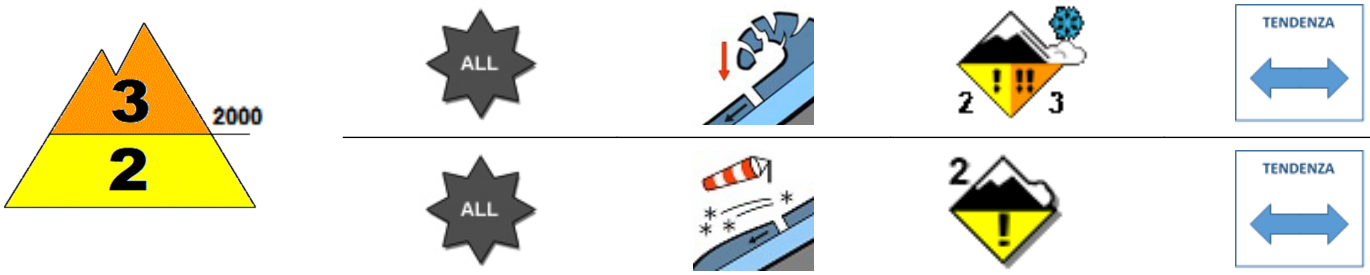

SITUAZIONE TIPO: neve a debole coesione e vento.

MANTO NEVOSO: La stabilità del manto nevoso è scarsa su alcuni punti (aree) per tutte le esposizioni al di sopra di 2000 mslm, possibili valanghe di dimensioni grandi.
La stabilità del manto nevoso è scarsa su pochi punti (aree) per tutte le esposizioni al di sotto di 2000 mslm, possibili valanghe di dimensioni medie.

AVVERTENZE

A seguito dell'attività eolica registrata sono da evitare le zone di accumulo, conche, canaloni, cambi di pendenza e pendii sotto vento in genere.

SCALA EUROPEA DEL GRADO DI PERICOLO VALANGHE

LEGENDA PROBLEMA

Bollettino realizzato su scala sinottica-regionale (standard EAWS). La sua valutazione non può escludere in alcun modo la necessità di una seria e capace valutazione locale del pericolo (singolo pendio) che può essere anche sensibilmente diverso. Le previsioni meteorologiche sono relative all'orario UTC (per l'Italia +1 in inverno e +2 in estate).

MINISTERO DELLA DIFESA

meteomont
Servizio Nazionale di previsione neve e valanghe

EAWS EUROPEAN AVALANCHE WARNING SERVICES

CARABINIERI

GRAN SASSO OVEST

PREVISIONE METEO

Quota		14/02/2026 h6:00	14/02/2026 h12:00	14/02/2026 h18:00
1000	Venti	02 Nodi da Sud	02 Nodi da Sud	01 Nodi da Est
	Temperature	+01 °C	+03 °C	+03 °C
	Temp.percepita	1 °C	3 °C	3 °C
2000	Venti	11 Nodi da S-Ovest	08 Nodi da S-Ovest	02 Nodi da Sud
	Temperature	-01 °C	-01 °C	+00 °C
	Temp.percepita	-7 °C	-6 °C	0 °C
3000	Venti	18 Nodi da S-Ovest	14 Nodi da S-Ovest	05 Nodi da S-Ovest
	Temperature	-08 °C	-07 °C	-07 °C
	Temp.percepita	-17 °C	-15 °C	-11 °C
Zero termico		1700-1900 m.	1800-2000 m.	1900-2100 m.
Fenomeno				—
Stato del cielo				

LEGENDA FENOMENI

— Assenza Fenomeni · Nebbia · Foschia · Pioggia debole · Pioggia moderata · Pioggia forte · Temporali

Nevicata debole · Nevicata moderata · Nevicata forte

STATO DEL CIELO

Sereno · Poco nuvoloso · Nuvoloso · Molto nuvoloso · Coperto

Parametri meteonivometrici registrati presso i campi di rilevamento il 13/02/2026.

Località	Comune	Quota (m.s.l.m.)	Altezza neve (cm)	Neve caduta nelle 24 ore (cm)	Temp. Min (°C)	Temp. Max (°C)	Condizioni del tempo
COLLE RUTO	Campotosto (AQ)	1384	0	0	0	+8	Assenza di precipitazioni
S. DONATO	Castel del Monte (AQ)	1400	0	0	0	+5	Assenza di precipitazioni
CANALE DEL RIFUGIO DUCA DEGLI ABRUZZI *	L'Aquila (AQ)	2181	280	10	N.P.	N.P.	Assenza di precipitazioni
MONTE AQUILA *	L'Aquila (AQ)	2367	250	14	N.P.	N.P.	Assenza di precipitazioni

(*) Rilievi fuori campo

L'INFORMAZIONE E' PREVENZIONE - LEGGI L'ATTUALE GRADO DI PERICOLO VALANGHE!

IL CAPO DEL CENTRO NAZIONALE METEOMONT
(Ten. Col. RFI Emanuela Gini)
FIRMA AUTOGRAFA OMESSA AI SENSI
DELL'ART.3 DEL D.LGS N.39/1993

Bollettino realizzato su scala sinottica-regionale (standard EAWS). La sua valutazione non può escludere in alcun modo la necessità di una seria e capace valutazione locale del pericolo (singolo pendio) che può essere anche sensibilmente diverso. Le previsioni meteorologiche sono relative all'orario UTC (per l'Italia +1 in inverno e +2 in estate).