MAJELLA

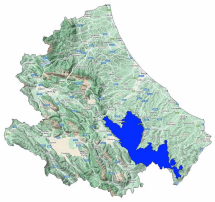

Bollettino Valanghe N. 332/2026 del 13/02/2026 ore 14.00
Validità 48 ore prossima emissione 14/02/2026
A cura del Servizio METEOMONT dell'ARMA dei CARABINIERI
In collaborazione con Servizio Meteorologico dell'Aeronautica militare

SITUAZIONE alle 14:00 del 13/02/2026

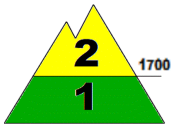

SITUAZIONE TIPO: neve a debole coesione e vento.



SITUAZIONE TIPO: situazione primaverile.

Quota neve (mslm)	Nord	Sud
	1500 - 1600	1800 - 1900

Altezza Neve (cm)	Neve al suolo	Neve Fresca	Quota (mslm)
	016	005	1650
	000	000	1270

VALANGHE OSSERVATE: Nessuna valanga.

PREVISIONI 14/02/2026

GRADO DI PERICOLO: MODERATO 2

SITUAZIONE TIPO: neve a debole coesione e vento.

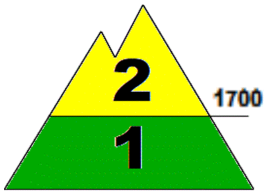

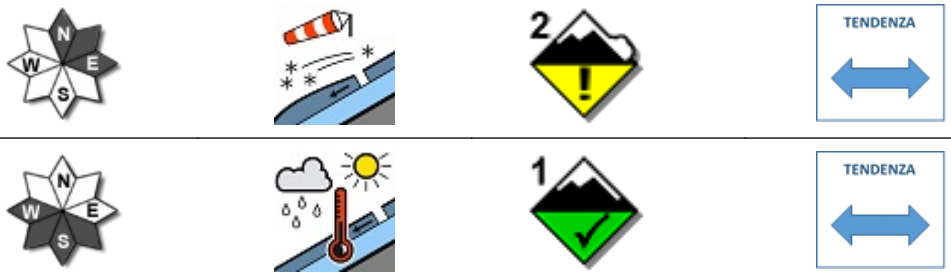

SITUAZIONE TIPO: situazione primaverile.

MANTO NEVOSO: La stabilità del manto nevoso è discreta su alcuni punti (aree) per versanti nord orientali al di sopra di 1700 mslm, possibili valanghe di dimensioni medie.
La stabilità del manto nevoso è discreta su molti punti (aree) per versanti al sole al di sotto di 1700 mslm, possibili valanghe di dimensioni piccole.

AVVERTENZE

Meteomont rammenta ARTVA, pala e sonda sempre al seguito.

SCALA EUROPEA DEL GRADO DI PERICOLO VALANGHE

5 - MOLTO FORTE | 4 - FORTE | 3 - MARCATO | 2 - MODERATO | 1 - DEBOLE | NO NEVE | NO INFO

LEGENDA PROBLEMA

NEVE FRESCA | LASTRONI DA VENTO | STRATI DEBOLI PERSISTENTI | NEVE BAGNATA | SLITTAMENTO | CORNICI | NESSUN PROBLEMA VALANGHIVO EVIDENTE | NO_INFO

Bollettino realizzato su scala sinottica-regionale (standard EAWS). La sua valutazione non può escludere in alcun modo la necessità di una seria e capace valutazione locale del pericolo (singolo pendio) che può essere anche sensibilmente diverso. Le previsioni meteorologiche sono relative all'orario UTC (per l'Italia +1 in inverno e +2 in estate).

MINISTERO DELLA DIFESA

meteomont
Servizio Nazionale di previsione neve e valanghe

EAWS EUROPEAN AVALANCHE WARNING SERVICES

CARABINIERI

MAJELLA

PREVISIONE METEO

Quota		14/02/2026 h6:00	14/02/2026 h12:00	14/02/2026 h18:00
1000	Venti	03 Nodi da S-Ovest	04 Nodi da Sud	02 Nodi da Sud
	Temperature	+02 °C	+02 °C	+02 °C
	Temp.percepita	0 °C	-0 °C	2 °C
2000	Venti	09 Nodi da S-Ovest	11 Nodi da S-Ovest	04 Nodi da S-Ovest
	Temperature	+00 °C	+00 °C	+00 °C
	Temp.percepita	-5 °C	-5 °C	-3 °C
3000	Venti	21 Nodi da S-Ovest	17 Nodi da S-Ovest	07 Nodi da S-Ovest
	Temperature	-07 °C	-07 °C	-06 °C
	Temp.percepita	-17 °C	-16 °C	-11 °C
Zero termico		1900-2100 m.	1900-2100 m.	1900-2100 m.
Fenomeno		—	—	—
Stato del cielo				

LEGENDA FENOMENI

— Assenza Fenomeni · Nebbia · Foschia · Pioggia debole · Pioggia moderata · Pioggia forte · Temporali

Nevicata debole · Nevicata moderata · Nevicata forte

STATO DEL CIELO

Sereno · Poco nuvoloso · Nuvoloso · Molto nuvoloso · Coperto

Parametri meteonivometrici registrati presso i campi di rilevamento il 13/02/2026.

Località	Comune	Quota (m.s.l.m.)	Altezza neve (cm)	Neve caduta nelle 24 ore (cm)	Temp. Min (°C)	Temp. Max (°C)	Condizioni del tempo
QUARTARANA	Campo di Giove (AQ)	1200	0	0	0	+4	Assenza di precipitazioni
PASSOLANCIANO	Lettomanoppello (PE)	1300	0	0	+1	+4	Assenza di precipitazioni
VALICO DELLA FORCHETTA	Palena (CH)	1270	0	0	0	+7	Assenza di precipitazioni
VALLE DEL SOLE	Pizzoferrato (CH)	1440	0	0	+1	+5	Assenza di precipitazioni
MAIELETTA MAMMA ROSA	Pretoro (CH)	1650	16	5	-2	+1	Assenza di precipitazioni
PASSO SAN LEONARDO	Sant'Eufemia a Maiella (PE)	1145	0	0	+1	+5	Assenza di precipitazioni

(*) Rilievi fuori campo

L'INFORMAZIONE E' PREVENZIONE - LEGGI L'ATTUALE GRADO DI PERICOLO VALANGHE!

IL CAPO DEL CENTRO NAZIONALE METEOMONT
(Ten. Col. RFI Emanuela Gini)
FIRMA AUTOGRAFA OMESSA AI SENSI
DELL'ART.3 DEL D.LGS N.39/1993

Bollettino realizzato su scala sinottica-regionale (standard EAWS). La sua valutazione non può escludere in alcun modo la necessità di una seria e capace valutazione locale del pericolo (singolo pendio) che può essere anche sensibilmente diverso. Le previsioni meteorologiche sono relative all'orario UTC (per l'Italia +1 in inverno e +2 in estate).