Bulletin d'estimation du risque d'avalanche
(valable en dehors des pistes balisées et ouvertes)

MASSIF : Aravis

Rédigé le vendredi 13 février 2026 à 09h

Estimation des risques pour le : VENDREDI 13 FÉVRIER

4

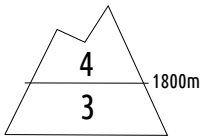

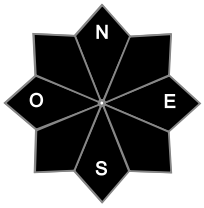

NEIGEUX

Au-dessus de 1800m indice de risque fort, plus bas indice marqué.

Départs spontanés : encore de très grandes avalanches possibles

Déclenchements provoqués : nombreuses plaques épaisses

Indices de risque : 5 très fort - 4 fort - 3 marqué - 2 limité - 1 faible -- En noir : les pentes les plus dangereuses

Stabilité du manteau neigeux

Situation avalancheuse typique : neige fraîche couche fragile persistante

Déclenchements provoqués :
* **nombreuses plaques friables dans l'épaisse couche de neige récente. Plaques probables toutes orientations et toutes altitudes, surtout au-dessus de 1800 m.** La réactivité des plaques est inégale selon les endroits. Les secteurs les plus délicats sont les pentes N à E, là où le vent de SW/W a pu former des accumulations. Cassure épaisse. Taille 2 à 3 (moyenne à grande).
* en versants NW/N/NE/E, au-dessus de 2000 m, une plaque de taille 4 (très grande) est possible, en cas de **départ en cascade** : une première avalanche de surface peut solliciter la couche fragile persistante enfouie (cassure de 1 à 2m).

Départs spontanés :
* activité spontanée en baisse avec la fin des chutes de neige. Quelques départs encore possibles dans les pentes raides, surtout si les zones de départ sont réchauffées par le soleil, notamment en falaises/barres rocheuses surplombant de grandes pentes. Taille 1 à 3 (petite à grande).

Qualité de la neige

Enneigement : dans la normale. On peut chausser les skis vers 1300/1400 m. Nombreuses congères et grosses corniches.

Qualité de la neige ce vendredi :
- au-dessus de 1800/2000 m : 50/80 cm de neige récente, ventée et grosses accumulations.
- en dessous de 1800 m : 30/40 cm de neige récente lourde.

La neige fraiche se tasse rapidement et s'alourdit sous 2000 m.

Aperçu météo pour le vendredi 13 février

	nuit	matin	après-midi	soir

Bons moments de soleil, un peu voilé l'après-midi.

Pluie-Neige	1 000 m			
Iso 0 °C	1 400 m	1 700 m	2 000 m	1 800 m
Vent 2000 m	→ 30 km/h	↗ 25 km/h	↗ 25 km/h	↑ 15 km/h
Vent 2500 m	→ 40 km/h	↗ 30 km/h	↗ 40 km/h	↖ 40 km/h

Épaisseur de neige hors-piste

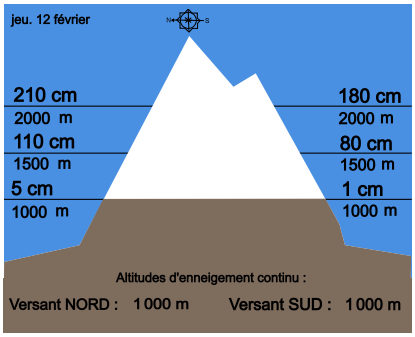

Précipitations à 1800 m

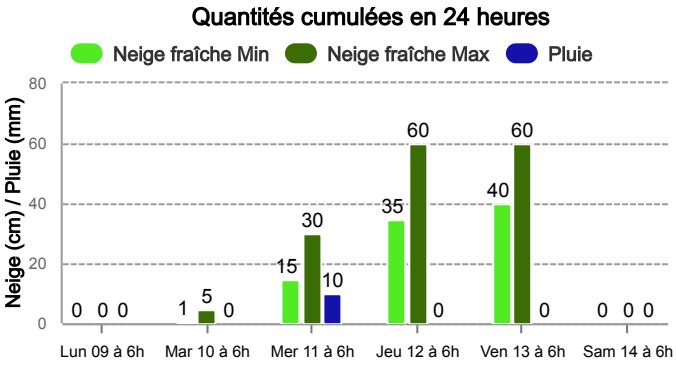

Tendance du samedi 14 février

3

Indice de risque marqué

Poursuite de la stabilisation

Pour consulter la vigilance en cours, veuillez vous rendre sur le site https://vigilance.meteofrance.fr/fr

Météo-France - 73 avenue de Paris, 94165 Saint-Mandé cedex - Contact : contact@meteo.fr

Rédigé par Météo-France avec la contribution des observateurs du réseau nivo-météorologiques. Partenariat : ANMSM (Maires de Stations de Montagne), DSF (Domaines Skiables de France), ADSP (Directeurs de Pistes et de la Sécurité des Stations de Sports d'Hiver) et autres acteurs de la montagne.

Bulletin neige & avalanches par téléphone au 0 892 68 10 20 Service 0,35 € / min + prix appel

RÉPUBLIQUE FRANÇAISE
Liberté Égalité Fraternité

METEO FRANCE
À VOS CÔTÉS, DANS UN CLIMAT QUI CHANGE

Bulletin d'estimation du risque d'avalanche

(valable en dehors des pistes balisées et ouvertes)

MASSIF : Aravis

Rédigé le vendredi 13 février 2026 à 09h

Conditions nivo-météo des 7 derniers jours

	ven. 06/02				sam. 07/02				dim. 08/02				lun. 09/02				mar. 10/02				mer. 11/02				jeu. 12/02			
	03h	09h	15h	21h	03h	09h	15h	21h	03h	09h	15h	21h	03h	09h	15h	21h	03h	09h	15h	21h	03h	09h	15h	21h	03h	09h	15h	21h
Météo																												
Vent (km/h)	50	50	40	30	20	10	10	10	20	15	10	5	5	20	30	55	50	50	60	75	90	70	70	90	80	70	50	60
à 2500m																												
Vent (km/h)	25	30	30	20	10	5	5	5	10	5	5	5	5	15	20	45	40	40	45	60	60	55	55	70	55	50	45	40
à 2000m																												

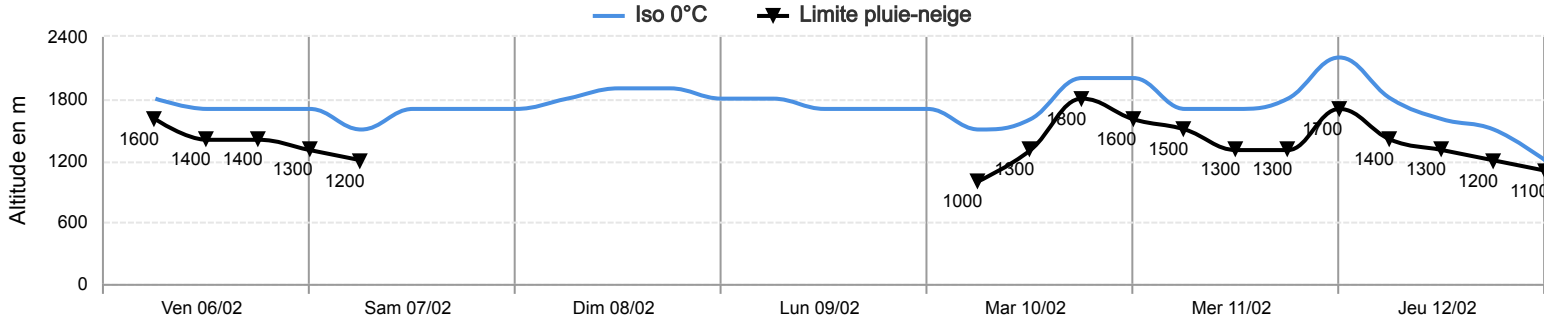

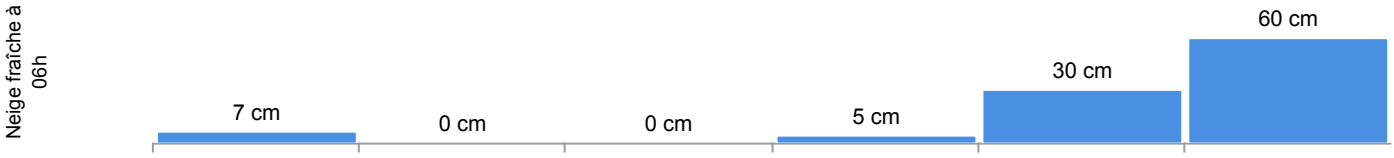

Risque d'avalanche	ven. 06/02	sam. 07/02	dim. 08/02	lun. 09/02	mar. 10/02	mer. 11/02	jeu. 12/02
		3	2	2	3	4	5

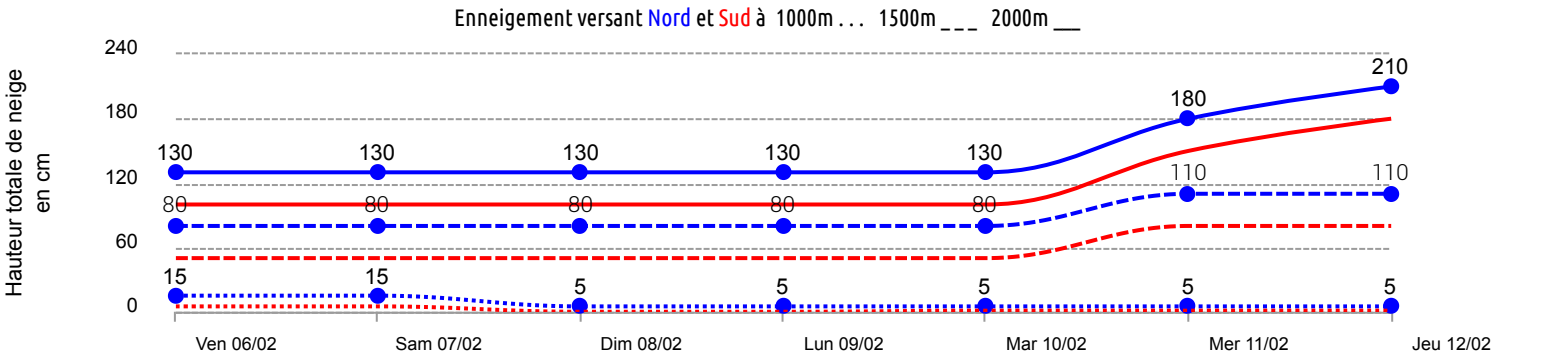

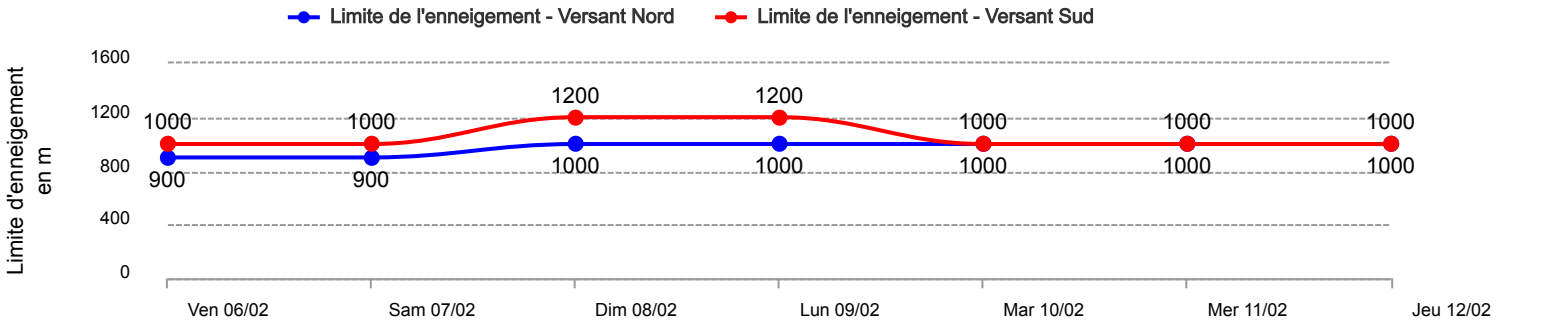

Pour consulter la vigilance en cours, veuillez vous rendre sur le site https://vigilance.meteofrance.fr/fr

Météo-France - 73 avenue de Paris, 94165 Saint-Mandé cedex - Contact : contact@meteo.fr

Rédigé par Météo-France avec la contribution des observateurs du réseau nivo-météorologiques. Partenariat : ANMSM (Maires de Stations de Montagne), DSF (Domaines Skiables de France), ADSP (Directeurs de Pistes et de la Sécurité des Stations de Sports d'Hiver) et autres acteurs de la montagne.

Bulletin neige & avalanches par téléphone au
0 892 68 10 20 Service 0,35 € / min + prix appel