Bulletin d'estimation du risque d'avalanche

(valable en dehors des pistes balisées et ouvertes)

MASSIF : Bauges

Rédigé le vendredi 13 février 2026 à 09h

Estimation des risques pour le : VENDREDI 13 FÉVRIER

3

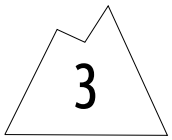

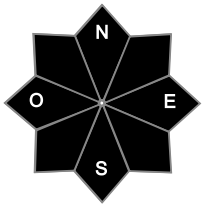

Indice de risque marqué.

Départs spontanés : encore un risque grande avalanche

Déclenchements provoqués : nombreuses plaques dans la neige récente

Indices de risque : 5 très fort - 4 fort - 3 marqué - 2 limité - 1 faible -- En noir : les pentes les plus dangereuses

Stabilité du manteau neigeux

Situation avalancheuse typique : neige fraîche

Déclenchements provoqués :

* **nombreuses plaques friables** encore présentes dans la neige fraîche. **Toutes orientations, surtout N à E.** Cassure épaisse, surtout aux endroits où le vent de SW/W a pu former des accumulations. Taille 2 à 3 (moyenne à grande).

Départs spontanés :

* activité en baisse avec l'arrêt des chutes de neige. Toutefois, quelques départs encore possibles dans les pentes raides, à fortiori dans les falaises/barres rocheuse ensoleillées. Taille 1 à 2 (petite à moyenne). Éventuellement une taille 3 (grande), avec un départ au-dessus de 1800/2000 m.

Qualité de la neige

Enneigement : dans la normale. On peut chausser les skis vers 1300/1400 m. Nombreuses congères et grosses corniches.

Qualité de la neige ce vendredi matin :
Au-dessus de 1500 m : neige fraiche, par endroit très ventée. En dessous, la neige est très humide. En journée, elle s'alourdit en surface sous 2000 m.

Aperçu météo pour le vendredi 13 février

Bons moments de soleil, un peu voilé l'après-midi.

	nuit	matin	après-midi	soir
Pluie-Neige	1 100 m			1 300 m
Iso 0 °C	1 300 m	1 700 m	1 900 m	1 700 m
Vent 1500 m	→ 20 km/h	↗ 20 km/h	↗ 20 km/h	↑ 10 km/h
Vent 2000 m	→ 40 km/h	↗ 25 km/h	↗ 30 km/h	↑ 25 km/h

Épaisseur de neige hors-piste

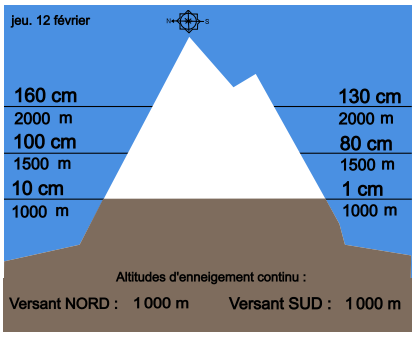

Précipitations à 1800 m

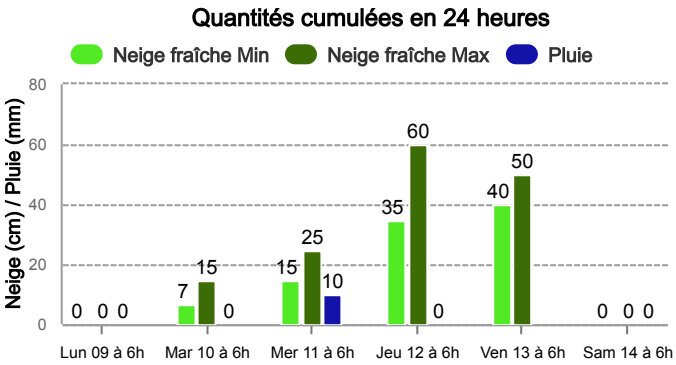

Tendance du samedi 14 février

3

Indice de risque marqué

Stabilisation du manteau neigeux en cours.

Pour consulter la vigilance en cours, veuillez vous rendre sur le site https://vigilance.meteofrance.fr/fr

Météo-France - 73 avenue de Paris, 94165 Saint-Mandé cedex - Contact : contact@meteo.fr

Rédigé par Météo-France avec la contribution des observateurs du réseau nivo-météorologiques. Partenariat : ANMSM (Maires de Stations de Montagne), DSF (Domaines Skiables de France), ADSP (Directeurs de Pistes et de la Sécurité des Stations de Sports d'Hiver) et autres acteurs de la montagne.

Bulletin neige & avalanches par téléphone au

0 892 68 10 20 Service 0,35 € / min + prix appel

Bulletin d'estimation du risque d'avalanche

(valable en dehors des pistes balisées et ouvertes)

MASSIF : Bauges

Rédigé le vendredi 13 février 2026 à 09h

Conditions nivo-météo des 7 derniers jours

	ven. 06/02				sam. 07/02				dim. 08/02				lun. 09/02				mar. 10/02				mer. 11/02				jeu. 12/02			
	03h	09h	15h	21h	03h	09h	15h	21h	03h	09h	15h	21h	03h	09h	15h	21h	03h	09h	15h	21h	03h	09h	15h	21h	03h	09h	15h	21h
Météo																												
Vent (km/h)	30	30	25	20	20	10	10	10	10	10	15	10	10	15	25	45	45	55	40	50	65	50	45	65	50	60	50	80
à 2000m																												
Vent (km/h)	25	25	20	10	10	5	5	5	5	5	10	5	5	10	15	35	35	40	30	40	50	40	35	55	45	40	40	50
à 1500m																												

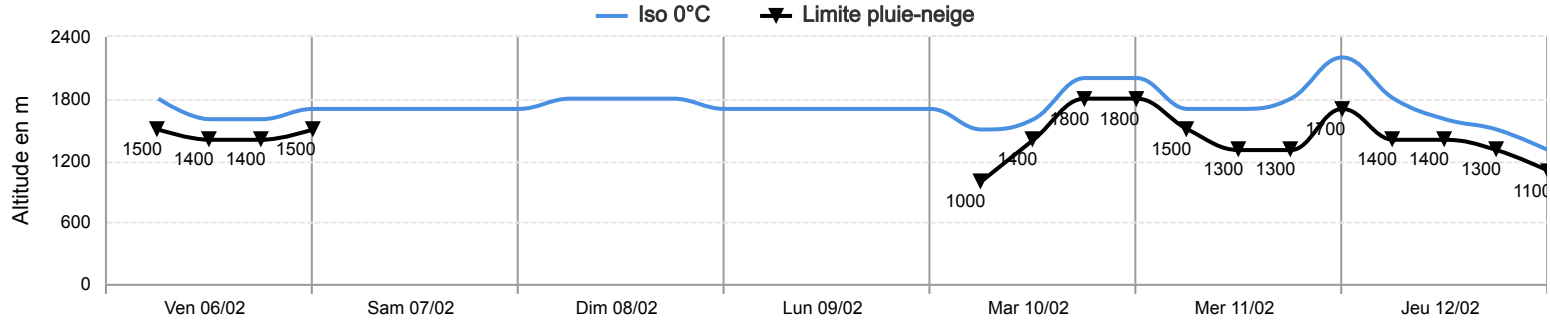

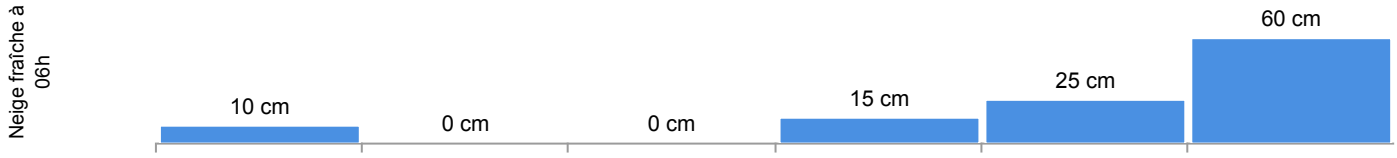

Risque d'avalanche	ven. 06/02	sam. 07/02	dim. 08/02	lun. 09/02	mar. 10/02	mer. 11/02	jeu. 12/02
		2	2	2	3	4	4

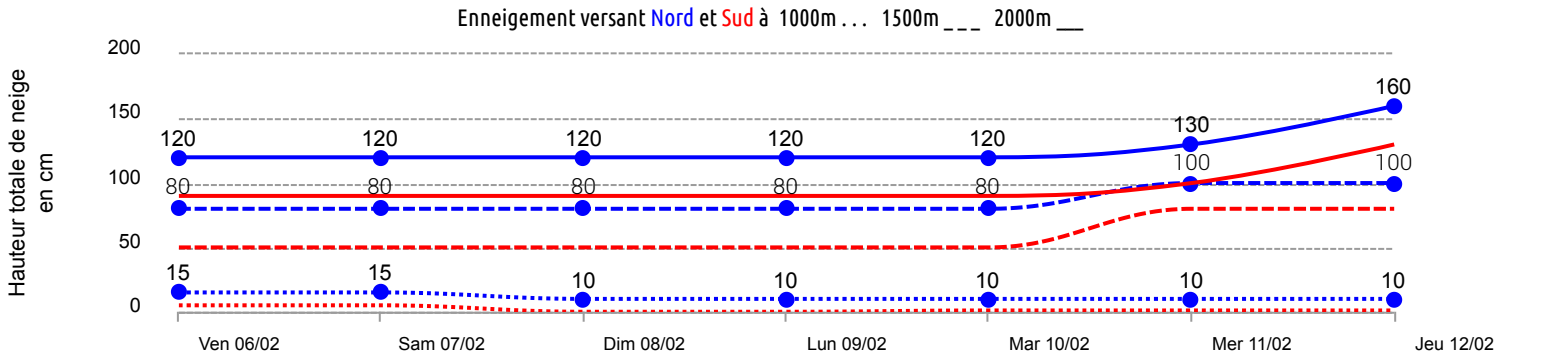

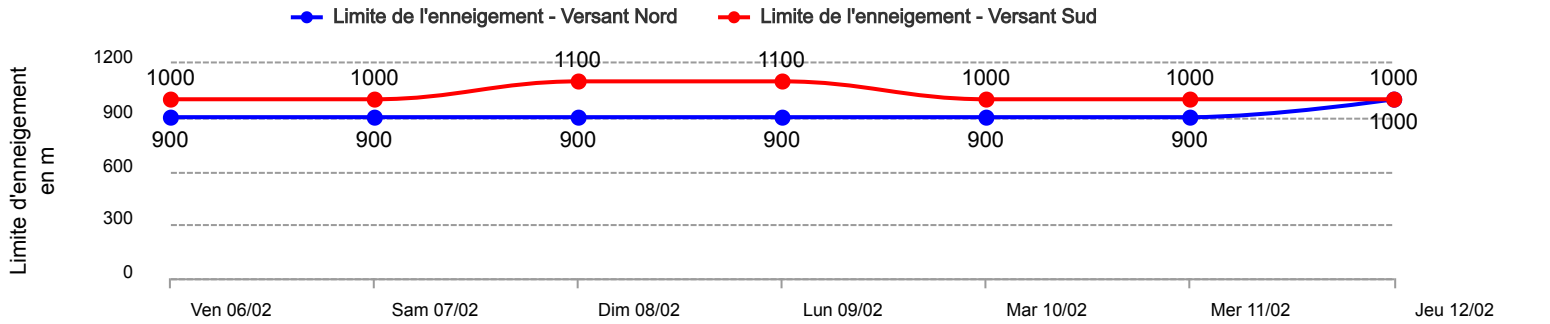

Pour consulter la vigilance en cours, veuillez vous rendre sur le site https://vigilance.meteofrance.fr/fr

Météo-France - 73 avenue de Paris, 94165 Saint-Mandé cedex - Contact : contact@meteo.fr

Bulletin neige & avalanches par téléphone au

0 892 68 10 20 Service 0,35 € / min + prix appel

Rédigé par Météo-France avec la contribution des observateurs du réseau nivo-météorologiques. Partenariat : ANMSM (Maires de Stations de Montagne), DSF (Domaines Skiables de France), ADSP (Directeurs de Pistes et de la Sécurité des Stations de Sports d'Hiver) et autres acteurs de la montagne.