RÉPUBLIQUE FRANÇAISE
Liberté Égalité Fraternité

METEO FRANCE
À VOS CÔTÉS, DANS UN CLIMAT QUI CHANGE

Bulletin d'estimation du risque d'avalanche

(valable en dehors des pistes balisées et ouvertes)

MASSIF : Grandes-Rousses

Rédigé le vendredi 13 février 2026 à 09h

Estimation des risques pour le : VENDREDI 13 FÉVRIER

JEUDI SOIR SITUATION AVALANCHEUSE ENCORE CRITIQUE EN ALTITUDE. VENDREDI FORTE INSTABILITE ESSENTIELLEMENT AU PASSAGE DE SKIEURS...

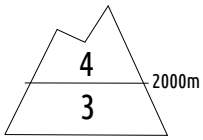

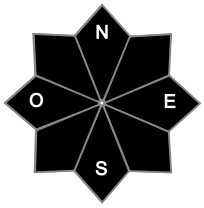

Jeudi soir...

Au-dessus de 2000m indice de risque fort, plus bas indice marqué.

Départs spontanés : Jeudi soir, encore de très grandes avalanches possibles, atteignant parfois les vallées.. Vendredi activité spontanée en atténuation se limitant à quelques pentes très raides/rochers lors d'éclaircies, aux altitudes modestes...

Déclenchements provoqués : En altitude fort risque accidentel persistant, près des crêtes comme en pleine pente parfois ? Sous 1800/2000m risque de plaque devenant plus localisé...

Indices de risque : 5 très fort - 4 fort - 3 marqué - 2 limité - 1 faible -- En noir : les pentes les plus dangereuses

Stabilité du manteau neigeux

Situation avalancheuse typique : neige ventée couche fragile persistante

Jeudi soir il neige encore, avec 80 cm à 1m20 de neige récente en altitude, des sous couches souvent instables, situation avalancheuse préoccupante...
Vendredi temps plus calme, amorce de stabilisation ... mais encore un fort risque accidentel, notamment au dessus de 2000m environ (risque de ruptures en "cascade")...

Départs spontanés :

Jeudi soir/en début de nuit : Neige encore et vent de Nord-Ouest, puis les précipitations vont s'atténuer. Avec des cumuls critiques en altitude (dépassant 1m voire 1m50 parfois), on peut s'attendre encore à de grandes avalanches, balayant couloirs et pentes raides. Celles ci peuvent parfois s'écouler jusqu'en en vallées/près des routes de moyenne montagne (dépôts plus humides). En haute montagne, la présence de sous couche fragile persistante pourrait faciliter quelques avalanches de très grande ampleur empruntant des trajectoires peu habituelles...

Vendredi en journée temps plus calme et sec. Fin attendue de la "crue" avalancheuse. Lors de brèves éclaircies coulées ou avalanches poudreuses possibles, près des rochers notamment. Aux altitudes modestes (sous 1600/1800m environ), la neige est assez humide en profondeur, on peut avoir quelques avalanches en pentes herbeuses, parfois de fond (glissement au terrain)

Déclenchements provoqués :

Haute montagne encore peu fréquentable vendredi dans la plupart des pentes. Nombreuses plaques encore bien instables, parfois loin des crêtes. Le vent a soufflé en diverses orientations. Noter qu'en large faces Nord des sous couches fragiles sont enfouies. Une première rupture pourrait entrainer une épaisse et large cassure en contrebas, entrainant un volume de neige très conséquent...

Plus bas que 1800/2000m environ, les sous couches sont un peu mieux stabilisées, risque de plaques surtout à proximité des crêtes. Le vent le plus récent soufflait du Nord-Ouest. Vendredi après-midi le vent de Sud se lèverait très localement...

Qualité de la neige

Qualification de l'enneigement : L'enneigement s'est encore amélioré en altitude, dans les combes, où il devient excellent pour la saison, notamment versant Vaujany. Il est en revanche médiocre plus bas que 1400m...

Limites skiables : vers 1200/1400 m...

Qualité de la neige vendredi :

Neige fraîche poudreuse plus épaisse en altitude et souvent soufflée/chahutée à l'abord des croupes et crêtes.

Fortes épaisseurs au dessus de 2200/2500m environ avec plus d'1m de neige récente vers 2500m, de grosses congères/corniches, des secteurs plus dégarnis...

Aperçu météo pour le vendredi 13 février

	nuit	matin	après-midi	soir

Jeudi soir averses de neige. Vendredi matin plus sec, calme. L'après-midi temps couvert en altitude, quelques flocons, un peu de vent de Sud...

Pluie-Neige	1 100 m		1 500 m	1 300 m
Iso 0 °C	1 400 m	2 000 m	1 800 m	1 700 m
Vent 2000 m	↘ 30 km/h	↗ 15 km/h	↖ 25 km/h	↖ 25 km/h
Vent 3000 m	→ 70 km/h	↗ 30 km/h	↖ 30 km/h	↖ 30 km/h

Pour consulter la vigilance en cours, veuillez vous rendre sur le site https://vigilance.meteofrance.fr/fr

Météo-France - 73 avenue de Paris, 94165 Saint-Mandé cedex - Contact : contact@meteo.fr

Rédigé par Météo-France avec la contribution des observateurs du réseau nivo-météorologiques. Partenariat : ANMSM (Maires de Stations de Montagne), DSF (Domaines Skiables de France), ADSP (Directeurs de Pistes et de la Sécurité des Stations de Sports d'Hiver) et autres acteurs de la montagne.

Bulletin neige & avalanches par téléphone au
0 892 68 10 20 Service 0,35 € / min + prix appel

Bulletin d'estimation du risque d'avalanche

(valable en dehors des pistes balisées et ouvertes)

MASSIF : Grandes-Rousses

Rédigé le vendredi 13 février 2026 à 09h

Épaisseur de neige hors-piste

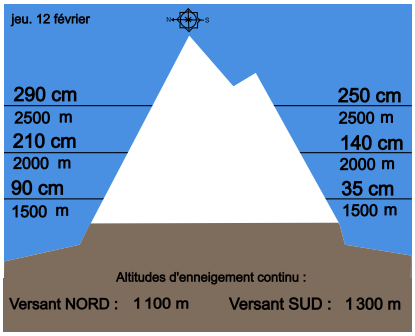

Précipitations à 1800 m

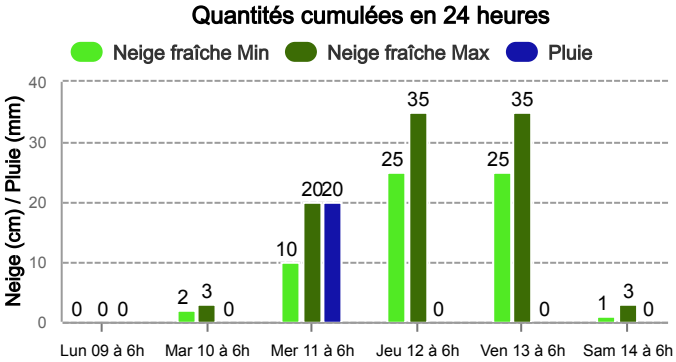

Tendance du samedi 14 février

Indice de risque fort

Risque d'avalanche stationnaire ou en légère baisse samedi matin (saupoudrage neigeux et vent faible). Mais samedi après-midi le vent de Nord pourra devenir sensible et former de nouvelles plaques instables...

Pour consulter la vigilance en cours, veuillez vous rendre sur le site https://vigilance.meteofrance.fr/fr

Météo-France - 73 avenue de Paris, 94165 Saint-Mandé cedex - Contact : contact@meteo.fr

Rédigé par Météo-France avec la contribution des observateurs du réseau nivo-météorologiques. Partenariat : ANMSM (Maires de Stations de Montagne), DSF (Domaines Skiables de France), ADSP (Directeurs de Pistes et de la Sécurité des Stations de Sports d'Hiver) et autres acteurs de la montagne.

Bulletin neige & avalanches par téléphone au

0 892 68 10 20 Service 0,35 € / min + prix appel

RÉPUBLIQUE FRANÇAISE
Liberté Égalité Fraternité

METEO FRANCE
À VOS CÔTÉS, DANS UN CLIMAT QUI CHANGE

Bulletin d'estimation du risque d'avalanche

(valable en dehors des pistes balisées et ouvertes)

MASSIF : Grandes-Rousses

Rédigé le vendredi 13 février 2026 à 09h

Conditions nivo-météo des 7 derniers jours

	ven. 06/02				sam. 07/02				dim. 08/02				lun. 09/02				mar. 10/02				mer. 11/02				jeu. 12/02			
	03h	09h	15h	21h	03h	09h	15h	21h	03h	09h	15h	21h	03h	09h	15h	21h	03h	09h	15h	21h	03h	09h	15h	21h	03h	09h	15h	21h
Météo																												
Vent (km/h)	45	30	25	20	20	10	10	10	15	20	25	25	30	15	15	25	35	35	50	60	100	85	85	100	100	100	90	75
à 3000m																												
Vent (km/h)	20	20	20	10	5	10	10	5	10	15	15	20	20	10	15	10	15	20	30	40	80	65	50	50	50	50	55	45
à 2000m																												

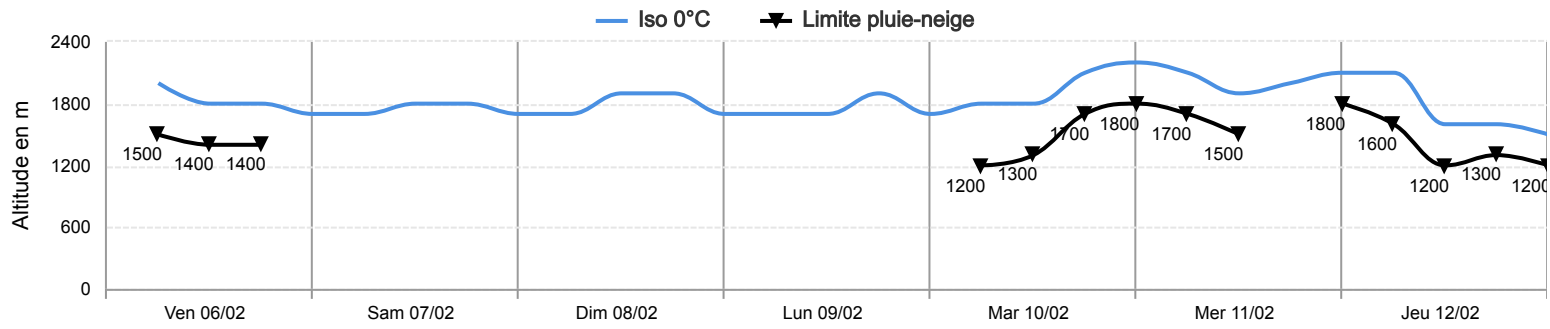

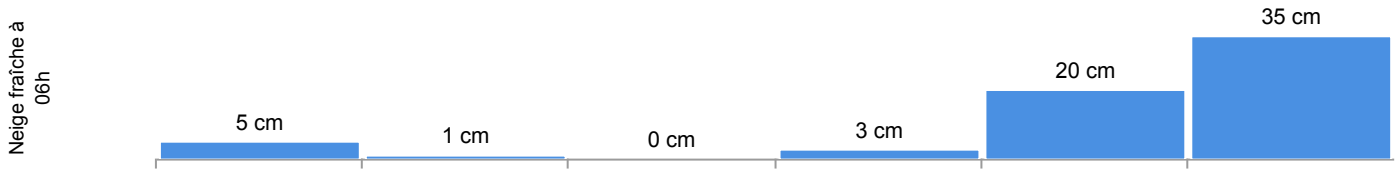

Risque d'avalanche	ven. 06/02	sam. 07/02	dim. 08/02	lun. 09/02	mar. 10/02	mer. 11/02	jeu. 12/02
		3	3	3	3	4	5

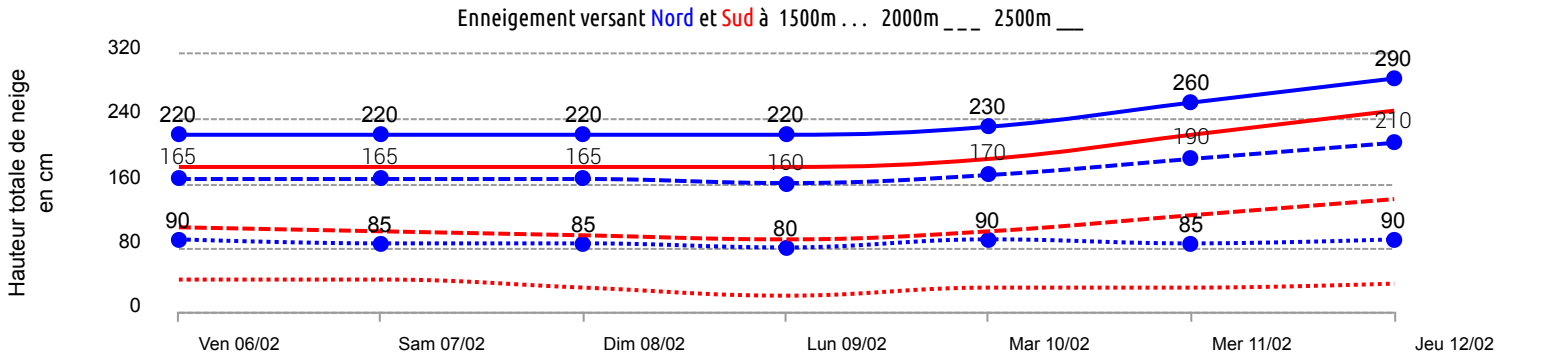

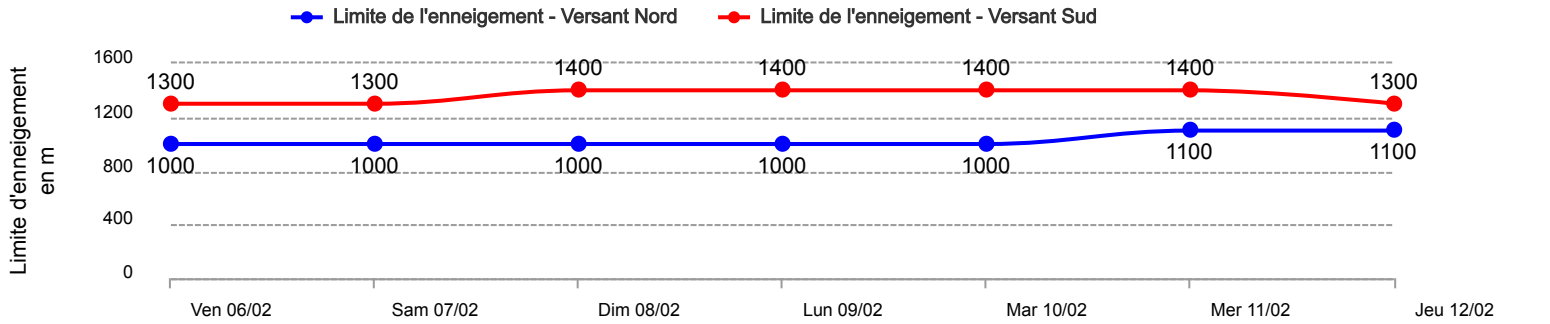

Pour consulter la vigilance en cours, veuillez vous rendre sur le site https://vigilance.meteofrance.fr/fr

Météo-France - 73 avenue de Paris, 94165 Saint-Mandé cedex - Contact : contact@meteo.fr

Rédigé par Météo-France avec la contribution des observateurs du réseau nivo-météorologiques. Partenariat : ANMSM (Maires de Stations de Montagne), DSF (Domaines Skiables de France), ADSP (Directeurs de Pistes et de la Sécurité des Stations de Sports d'Hiver) et autres acteurs de la montagne.

Bulletin neige & avalanches par téléphone au
0 892 68 10 20 Service 0,35 € / min + prix appel