# Bulletin d'estimation du risque d'avalanche
(valable en dehors des pistes balisées et ouvertes)

# MASSIF : Vercors

Rédigé le vendredi 13 février 2026 à 09h

## Estimation des risques pour le : VENDREDI 13 FÉVRIER

**IMPORTANTES QUANTITES DE NEIGE FRAICHE SOUFFLEE EN ALTITUDE, ENCORE BIEN INSTABLE JEUDI SOIR... VENDREDI ENCORE UN RISQUE DE PLAQUES VERS LES CRETES...**

3

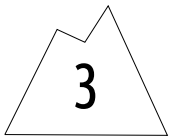


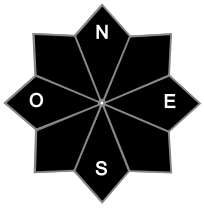


Barrière orientale

Indice de risque marqué.

**Départs spontanés :** Jeudi soir/début de nuit, encore quelques avalanches possibles sous le vent de Nord-Ouest (parfois grandes). Vendredi moins d'activité ou des avalanches plus superficielles/près des rochers. En pentes herbeuses rare départ de fond...

**Déclenchements provoqués :** Risque accidentel encore localement marqué vers les hautes crêtes et sommets. Accumulations sous le vent de Nord-Ouest, puis vendredi après-midi un peu de vent de Sud...

Indices de risque : 5 très fort - 4 fort - 3 marqué - 2 limité - 1 faible -- En noir : les pentes les plus dangereuses

## Stabilité du manteau neigeux

**Situation avalancheuse typique :** neige ventée avalanches de fond

Jeudi soir encore neigeux sous le vent de Nord-Ouest, des avalanches possibles en altitude. Vendredi plus calme et sec, mais risque accidentel de plaque encore localement marqué à l'abord des crêtes et sommets...

**Départs spontanés :**

Jeudi en soirée/début de nuit, encore des chutes de neige sous le vent de Nord-Ouest avec jusque 30/40 cm de fraîche en altitude. On attend quelques avalanches spontanées en pentes/couloirs d'altitude (barrière orientale), parfois de taille plus conséquente (ruptures linéaires).
Vendredi a priori moins d'activité. Néanmoins lors de brèves éclaircies on s'attend à des avalanches de surface en pentes "réchauffées", près des rochers...
Noter qu'en pentes herbeuses raides (sous 1600 voire 1800m), la neige est assez humide en profondeur, on s'attend à quelques avalanches de fond avec glissement possible jusqu'au terrain.

**Déclenchements provoqués :** Vendredi, encore un risque accidentel de plaques, notamment à proximité des crêtes et sommets, parfois en pieds de barres.
Un seul skieur peut parfois déclencher une plaque assez conséquente. (Sous couche plus poudreuse représentant une couche fragile temporaire)... A modeste altitude, en neige plus humide, plutôt un risque de coulée ponctuelle sous les skis...

## Qualité de la neige

**Qualification de l'enneigement :** L'enneigement s'est récemment dégradé aux basses altitudes, sous les sapins mais reste correct à bon pour la saison dès la moyenne montagne et dans les combes sommitales... Crêtes plus dégarnies alternant avec congères et corniches...
**Limites skiables :** Vers 1200/1400 m, sur les pistes forestières/clairières...

**Qualité de la neige vendredi :** A basse altitude, regel au matin, plaques de glace... dès la moyenne montagne neige poudreuse, plus conséquente au dessus de 1500/1700m : 20/40 cm environ. Souvent ventée vers les hautes crêtes et sommets/ durcie, sculptée parfois. Lors de timides éclaircies, neige s'humidifiant au soleil, plutôt sous 1500/1800m...

## Aperçu météo pour le vendredi 13 février

| | nuit | matin | après-midi | soir |
|---|---|---|---|---|
| | | | | |

Jeudi soir averses de neige. Vendredi matin plus sec, calme. L'après-midi temps couvert en altitude, 2 flocons, un peu de vent de Sud...

| | | | | |
|---|---|---|---|---|
| **Pluie-Neige** | 1 100 m | | 1 500 m | 1 300 m |
| **Iso 0 °C** | 1 400 m | 1 900 m | 1 800 m | 1 700 m |
| **Vent 1500 m** | ↓ 30 km/h | ↑ 15 km/h | ↑ 35 km/h | ↑ 20 km/h |
| **Vent 2000 m** | ↘ 50 km/h | ↑ 25 km/h | ↑ 35 km/h | ↑ 30 km/h |

## Épaisseur de neige hors-piste

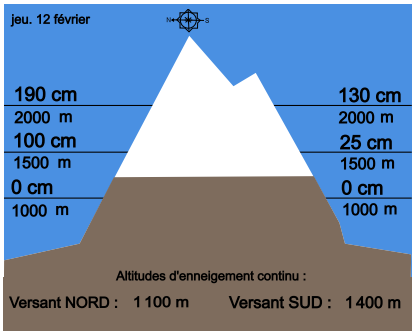


## Précipitations à 1800 m

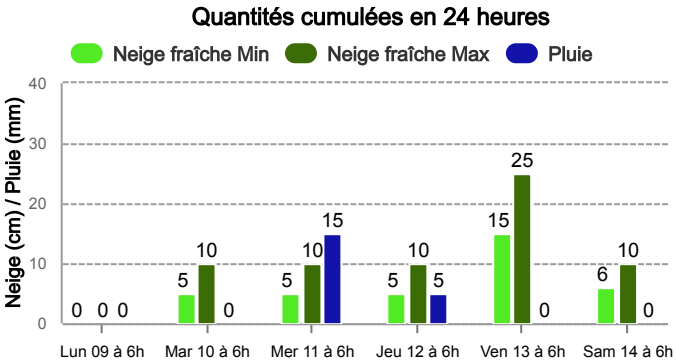


## Tendance du samedi 14 février

3 **Indice de risque marqué**

Peu d'évolution. Vent de Nord se renforçant l'après-midi/le soir avec des giboulées de neige en vue jusqu'à assez basse altitude (quantité plus conséquente sur l'Ouest du Vercors). Risque de plaques marqué à l'approche des crêtes.

Pour consulter la vigilance en cours, veuillez vous rendre sur le site https://vigilance.meteofrance.fr/fr

Météo-France - 73 avenue de Paris, 94165 Saint-Mandé cedex - Contact : contact@meteo.fr

Rédigé par Météo-France avec la contribution des observateurs du réseau nivo-météorologiques. Partenariat : ANMSM (Maires de Stations de Montagne), DSF (Domaines Skiables de France), ADSP (Directeurs de Pistes et de la Sécurité des Stations de Sports d'Hiver) et autres acteurs de la montagne.

Bulletin neige & avalanches par téléphone au
0 892 68 10 20 Service 0,35 € / min + prix appel

RÉPUBLIQUE FRANÇAISE
*Liberté Égalité Fraternité*

METEO FRANCE
À VOS CÔTÉS, DANS UN CLIMAT QUI CHANGE

# Bulletin d'estimation du risque d'avalanche
## (valable en dehors des pistes balisées et ouvertes)

# MASSIF : Vercors

Rédigé le vendredi 13 février 2026 à 09h

## Conditions nivo-météo des 7 derniers jours

| | ven. 06/02 | | | | sam. 07/02 | | | | dim. 08/02 | | | | lun. 09/02 | | | | mar. 10/02 | | | | mer. 11/02 | | | | jeu. 12/02 | | | |
|---|---|---|---|---|---|---|---|---|---|---|---|---|---|---|---|---|---|---|---|---|---|---|---|---|---|---|---|---|
| | 03h | 09h | 15h | 21h | 03h | 09h | 15h | 21h | 03h | 09h | 15h | 21h | 03h | 09h | 15h | 21h | 03h | 09h | 15h | 21h | 03h | 09h | 15h | 21h | 03h | 09h | 15h | 21h |
| Météo | | | | | | | | | | | | | | | | | | | | | | | | | | | | |
| Vent (km/h) | 55 | 25 | 25 | 15 | 15 | 15 | 15 | 10 | 25 | 20 | 25 | 20 | 10 | 25 | 25 | 35 | 50 | 40 | 50 | 70 | 80 | 65 | 55 | 100 | 85 | 70 | 70 | 65 |
| à 2000m | | | | | | | | | | | | | | | | | | | | | | | | | | | | |
| Vent (km/h) | 20 | 20 | 20 | 10 | 10 | 10 | 15 | 10 | 15 | 20 | 20 | 15 | 10 | 15 | 25 | 25 | 40 | 30 | 35 | 50 | 60 | 30 | 35 | 85 | 70 | 50 | 45 | 35 |
| à 1500m | | | | | | | | | | | | | | | | | | | | | | | | | | | | |

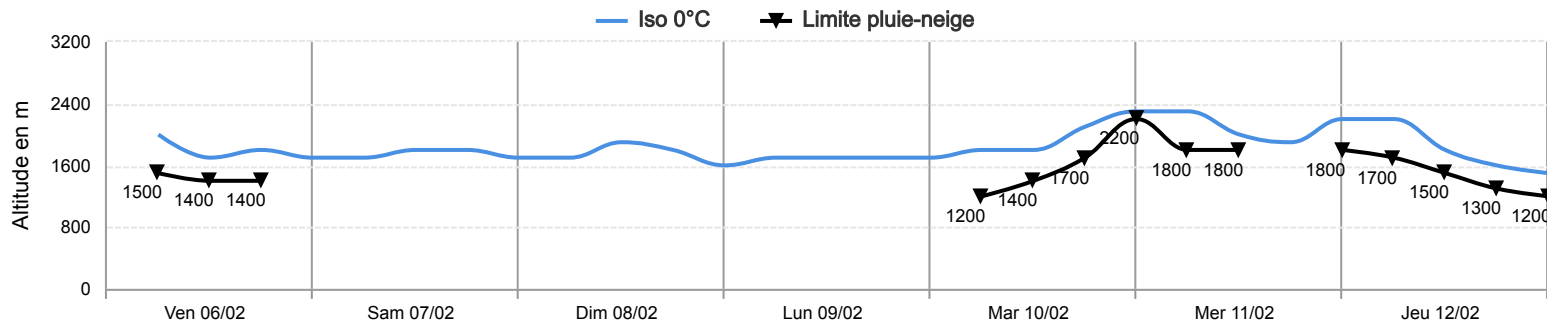


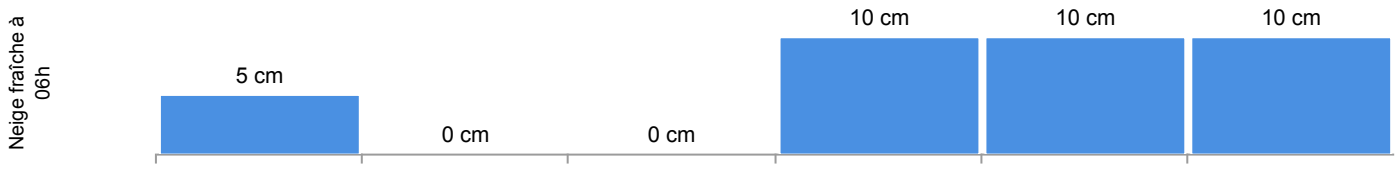


| Risque d'avalanche | ven. 06/02 | sam. 07/02 | dim. 08/02 | lun. 09/02 | mar. 10/02 | mer. 11/02 | jeu. 12/02 |
|---|---|---|---|---|---|---|---|
| | | 3 | 2 | 2 | 3 | 3 | 3 |

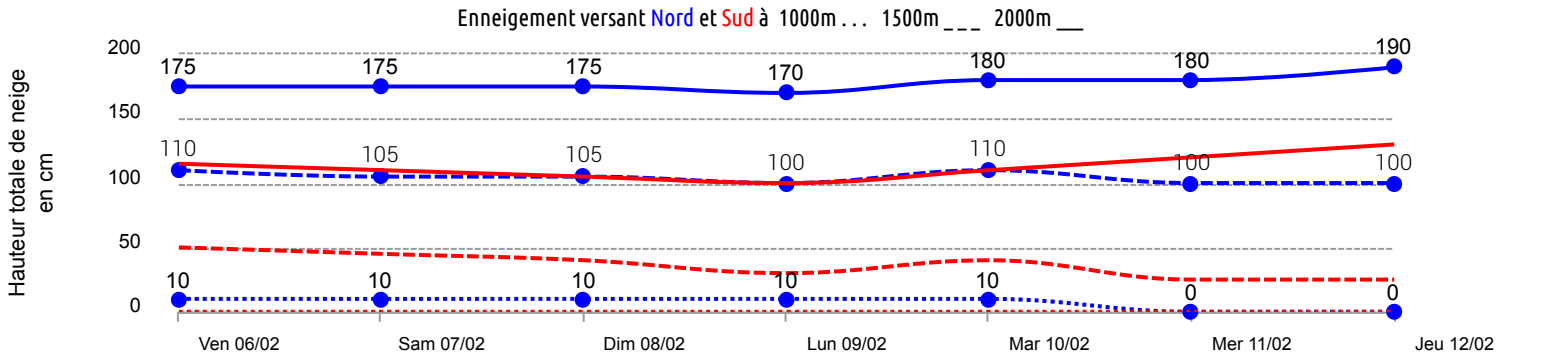


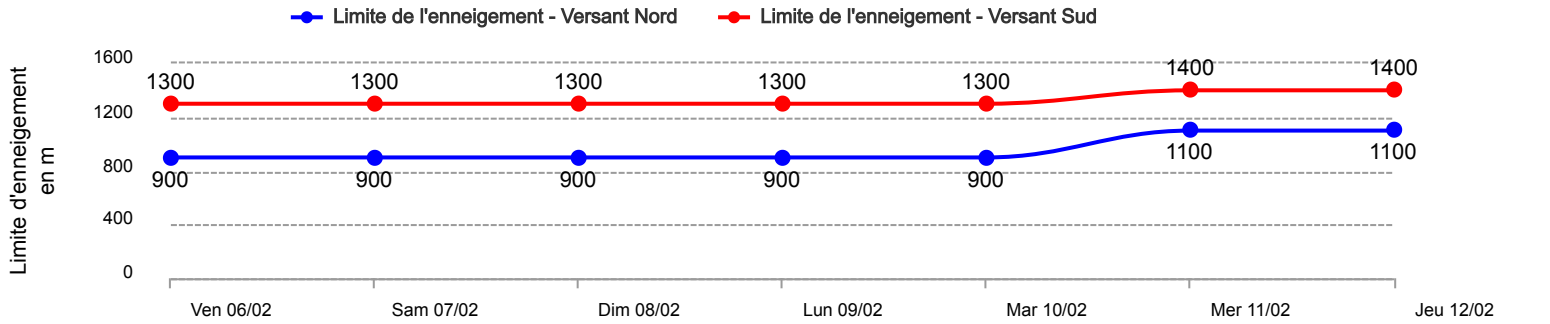


Pour consulter la vigilance en cours, veuillez vous rendre sur le site https://vigilance.meteofrance.fr/fr


Météo-France - 73 avenue de Paris, 94165 Saint-Mandé cedex - Contact : contact@meteo.fr



Rédigé par Météo-France avec la contribution des observateurs du réseau nivo-météorologiques. Partenariat : ANMSM (Maires de Stations de Montagne), DSF (Domaines Skiables de France), ADSP (Directeurs de Pistes et de la Sécurité des Stations de Sports d'Hiver) et autres acteurs de la montagne.


Bulletin neige & avalanches par téléphone au

**0 892 68 10 20** Service 0,35 € / min + prix appel