Bulletin d'estimation du risque d'avalanche

(valable en dehors des pistes balisées et ouvertes)

MASSIF : Bauges

Rédigé le vendredi 13 février 2026 à 16h

Estimation des risques pour le : SAMEDI 14 FÉVRIER

3

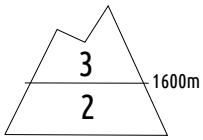

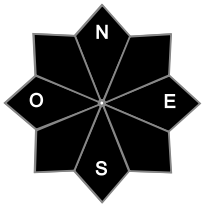

Au-dessus de 1600m indice de risque marqué, plus bas indice limité.

Départs spontanés : quelques plaques de fond

Déclenchements provoqués : des plaques dans la neige récente travaillée par le vent

Indices de risque : 5 très fort - 4 fort - 3 marqué - 2 limité - 1 faible -- En noir : les pentes les plus dangereuses

Stabilité du manteau neigeux

Situation avalancheuse typique : neige ventée — avalanches de fond

Déclenchements provoqués :

* **plaques friables** nouvelles, formées dans la couche de neige récente. Surtout dans les zones travaillées et/ou accumulées. Le vent a soufflé de SW/W ce vendredi, puis de N samedi après-midi. La plupart de ces plaques sont friables, mais certaines peuvent aussi être dures, notamment en altitude au voisinage des crêtes. Les orientations NW, N, NE et E sont les plus concernées. Cassure épaisse possible, 20/40 cm en moyenne, mais 60/80 cm dans une accumulation, pas forcément visible. Taille 2 (moyenne) voire 3 (grande).
Observables : fissures devant les skis, neige un peu "mâte", changement de qualité de neige sur une courte distance.
* attention aux **corniches** récentes, fragiles

Départs spontanés :

* **plaques de fond**. Possibles à toute heure, en pentes très raides et lisses, en herbe ou dalles rocheuses. Taille 2, éventuellement 3 avec un départ au-dessus de 1800 m.

Qualité de la neige

Enneigement : bon. On peut chausser les skis vers 1200/1400 m. Nombreuses congères et grosses corniches.

Qualité de la neige ce samedi :
En dessous de 1500/1800 m : neige récente poudreuse ou finement croûtée. On touche un fond encore un peu humide des dernières pluies, gardant les skis.
Au-dessus de 1800 m : poudreuse ou travaillée par le vent de SW/W. Un peu croûtée en adrets.

Aperçu météo pour le samedi 14 février

nuit	matin	après-midi	soir

Nuageux le matin. Averses de neige l'après-midi. -2/-3 DG vers 2000 m.

Pluie-Neige			1 200 m	800 m
Iso 0 °C	1 800 m	1 600 m	1 400 m	1 000 m
Vent 1500 m	20 km/h	20 km/h	30 km/h	30 km/h
Vent 2000 m	30 km/h	30 km/h	40 km/h	40 km/h

Épaisseur de neige hors-piste

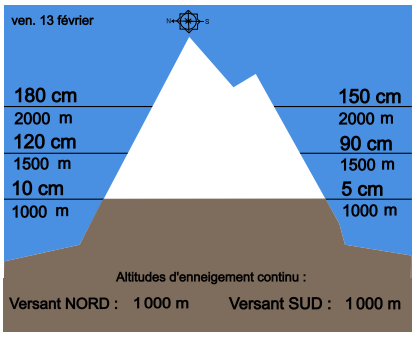

Précipitations à 1800 m

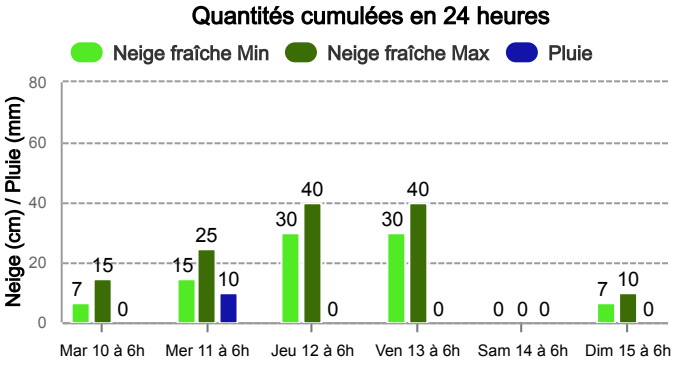

Tendance du dimanche 15 février

3

Indice de risque marqué

Risque stationnaire ou en légère baisse.

Pour consulter la vigilance en cours, veuillez vous rendre sur le site https://vigilance.meteofrance.fr/fr

Météo-France - 73 avenue de Paris, 94165 Saint-Mandé cedex - Contact : contact@meteo.fr

Rédigé par Météo-France avec la contribution des observateurs du réseau nivo-météorologiques. Partenariat : ANMSM (Maires de Stations de Montagne), DSF (Domaines Skiables de France), ADSP (Directeurs de Pistes et de la Sécurité des Stations de Sports d'Hiver) et autres acteurs de la montagne.

Bulletin neige & avalanches par téléphone au 0 892 68 10 20 Service 0,35 € / min + prix appel

Bulletin d'estimation du risque d'avalanche

(valable en dehors des pistes balisées et ouvertes)

MASSIF : Bauges

Rédigé le vendredi 13 février 2026 à 16h

Conditions nivo-météo des 7 derniers jours

	sam. 07/02				dim. 08/02				lun. 09/02				mar. 10/02				mer. 11/02				jeu. 12/02				ven. 13/02			
	03h	09h	15h	21h	03h	09h	15h	21h	03h	09h	15h	21h	03h	09h	15h	21h	03h	09h	15h	21h	03h	09h	15h	21h	03h	09h	15h	21h
Météo																												
Vent (km/h)	20	10	10	10	10	10	15	10	10	15	25	45	45	55	40	50	65	50	45	65	60	60	50	60	50	40	40	30
à 2000m																												
Vent (km/h)	10	5	5	5	5	5	10	5	5	10	15	35	35	40	30	40	50	40	35	55	50	40	40	50	40	30	20	20
à 1500m																												

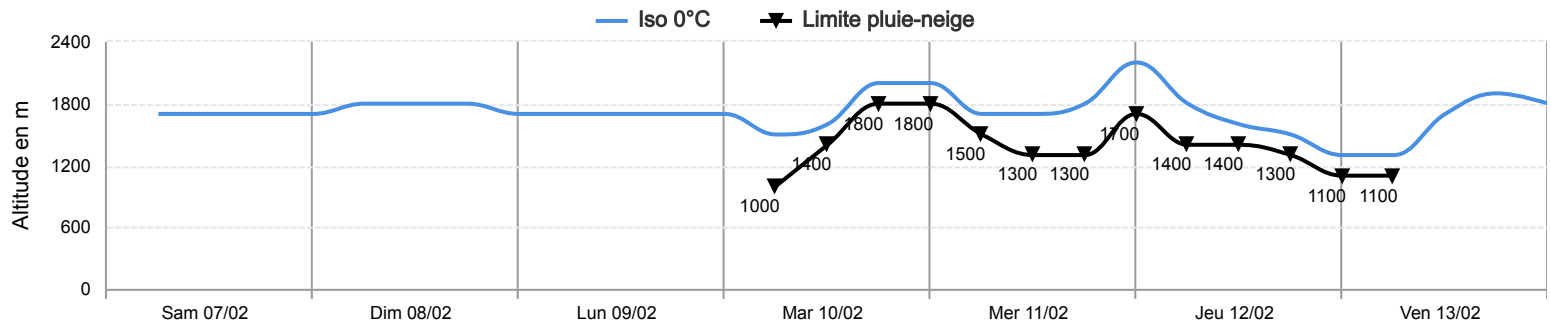

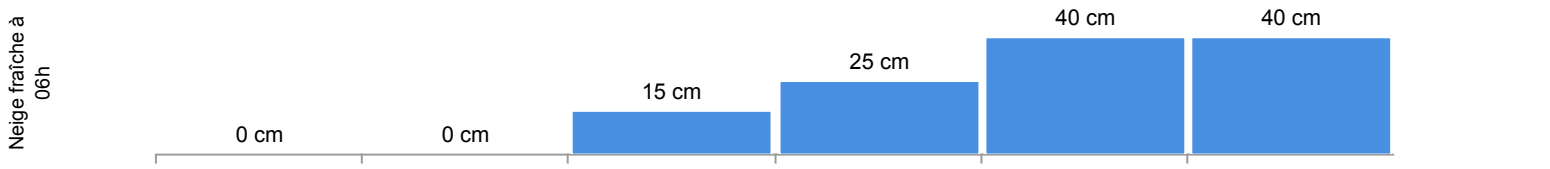

Risque d'avalanche	sam. 07/02	dim. 08/02	lun. 09/02	mar. 10/02	mer. 11/02	jeu. 12/02	ven. 13/02
	2	2	2	3	4	4	3

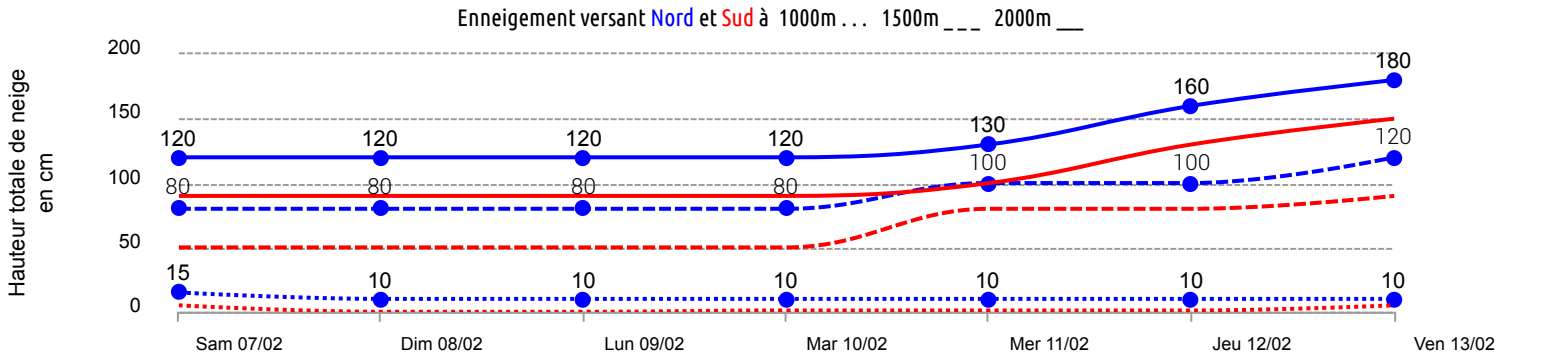

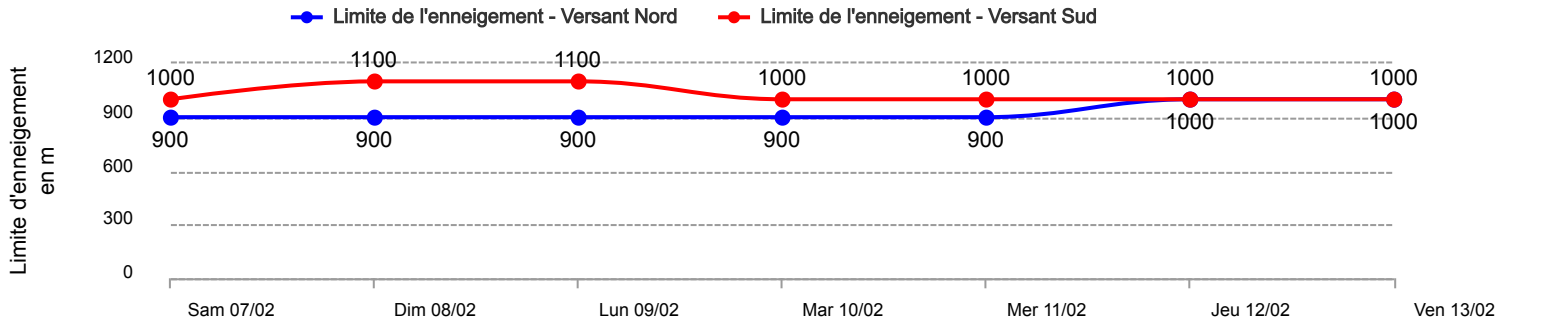

Pour consulter la vigilance en cours, veuillez vous rendre sur le site https://vigilance.meteofrance.fr/fr

Météo-France - 73 avenue de Paris, 94165 Saint-Mandé cedex - Contact : contact@meteo.fr

Rédigé par Météo-France avec la contribution des observateurs du réseau nivo-météorologiques. Partenariat : ANMSM (Maires de Stations de Montagne), DSF (Domaines Skiables de France), ADSP (Directeurs de Pistes et de la Sécurité des Stations de Sports d'Hiver) et autres acteurs de la montagne.

Bulletin neige & avalanches par téléphone au 0 892 68 10 20 Service 0,35 € / min + prix appel