Bulletin d'estimation du risque d'avalanche
(valable en dehors des pistes balisées et ouvertes)

MASSIF : Belledonne

Rédigé le vendredi 13 février 2026 à 16h

Estimation des risques pour le : SAMEDI 14 FÉVRIER

RISQUE ACCIDENTEL ENCORE BIEN MARQUE SURTOUT EN ALTITUDE

3

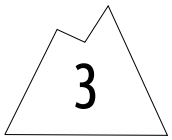

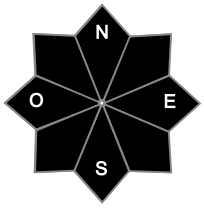

instable en altitude

Indice de risque marqué.

Départs spontanés : Activité en nette baisse hormis sur quelques pentes très raides/rochers lors d'éclaircies à des altitudes plus modestes.

Déclenchements provoqués : En altitude le risque accidentel est généralisé avec de nombreuses plaques facilement déclenchables. Le vent de Nord se renforce et forme de nouvelles plaques.

Indices de risque : 5 très fort - 4 fort - 3 marqué - 2 limité - 1 faible -- En noir : les pentes les plus dangereuses

Stabilité du manteau neigeux

Situation avalancheuse typique :

neige ventée

couche fragile persistante

Départs spontanés :

Samedi, lors de brèves éclaircies, coulées ou avalanches poudreuses possibles, près des rochers notamment. Aux altitudes modestes (sous 1600/1800m environ), la neige est assez humide en profondeur, on peut avoir quelques avalanches en pentes herbeuses, parfois de fond (glissement au terrain). Ailleurs le risque est plus limité.

Déclenchements provoqués :

Le risque reste encore conséquent en altitude, particulièrement au-dessus de 1800/2000m. Nombreuses plaques potentiellement instables, parfois loin des crêtes. Le vent a soufflé en diverses orientations et passe d'une tendance Sud à une tendance plus Nord pour samedi, accentuant le transport de neige. En secteur Nord des sous couches fragiles sont encore enfouies et une première rupture de plauqe peut entrainer une épaisse et large cassure en contrebas, entrainant un volume de neige très conséquent (larges cassures observées récemment en faces Nord de Belle Etoile)...
Plus bas que 2000/2200m environ, les sous couches sont un peu mieux stabilisées. Risque de plaques surtout à proximité des crêtes avec départs possibles au passage d'un unique skieur mais avec une épaisseur mobilisable plus limitée. Travail du vent/congères sont assez visibles.

Qualité de la neige

Qualification de l'enneigement : L'enneigement s'est encore amélioré en altitude, dans les combes, où il devient excellent pour la saison. Il est en revanche médiocre plus bas que 1300/1400m...
Limites skiables : vers 1100/1300 m.

Qualité de la neige samedi :

Neige fraîche poudreuse plus épaisse en altitude et souvent soufflée/chahutée à l'abord des croupes et crêtes. A 1100/1300m, fine couche de 5/10cm au matin.
Fortes épaisseurs au dessus de 2200/2400m environ avec plus d'1m de neige récente vers 2500m, de grosses congères/corniches, des secteurs plus dégarnis...

Aperçu météo pour le samedi 14 février

	nuit	matin	après-midi	soir

Journée plutot nuageuse avec de faibles averses de neige et un vent de Nord qui se renforce.

Pluie-Neige	1 100 m	1 100 m	1 200 m	600 m
Iso 0 °C	1 800 m	1 500 m	1 500 m	1 100 m
Vent 2000 m	↖ 10 km/h	↙ 10 km/h	↓ 35 km/h	↓ 30 km/h
Vent 3000 m	↑ 20 km/h	← 20 km/h	↓ 50 km/h	↓ 50 km/h

Épaisseur de neige hors-piste

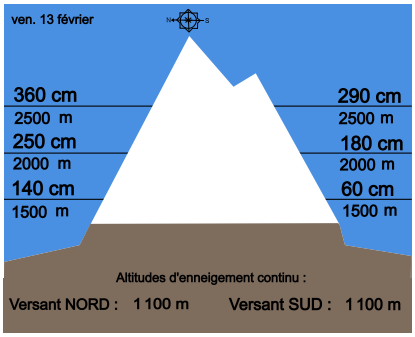

Précipitations à 1800 m

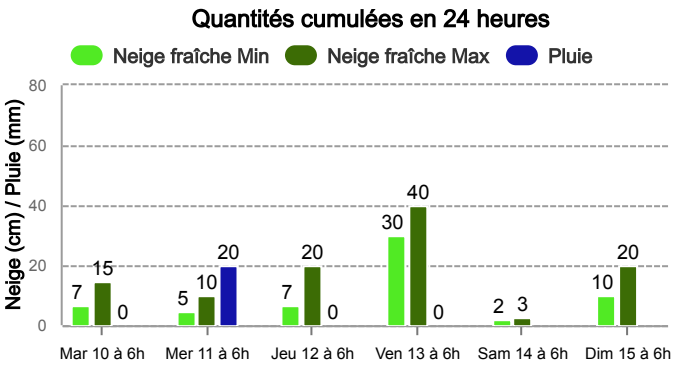

Tendance du dimanche 15 février

3

Indice de risque marqué

Tendance à la stabilisation avec un temps plus calme à venir.

Pour consulter la vigilance en cours, veuillez vous rendre sur le site https://vigilance.meteofrance.fr/fr

Météo-France - 73 avenue de Paris, 94165 Saint-Mandé cedex - Contact : contact@meteo.fr

Rédigé par Météo-France avec la contribution des observateurs du réseau nivo-météorologiques. Partenariat : ANMSM (Maires de Stations de Montagne), DSF (Domaines Skiables de France), ADSP (Directeurs de Pistes et de la Sécurité des Stations de Sports d'Hiver) et autres acteurs de la montagne.

Bulletin neige & avalanches par téléphone au
0 892 68 10 20 Service 0,35 € / min + prix appel

Bulletin d'estimation du risque d'avalanche

(valable en dehors des pistes balisées et ouvertes)

MASSIF : Belledonne

Rédigé le vendredi 13 Février 2026 à 16h

Conditions nivo-météo des 7 derniers jours

	sam. 07/02				dim. 08/02				lun. 09/02				mar. 10/02				mer. 11/02				jeu. 12/02				ven. 13/02			
	03h	09h	15h	21h	03h	09h	15h	21h	03h	09h	15h	21h	03h	09h	15h	21h	03h	09h	15h	21h	03h	09h	15h	21h	03h	09h	15h	21h
Météo																												
Vent (km/h)	15	10	5	5	15	25	20	25	30	30	35	40	50	40	50	70	100	85	85	100	100	100	90	50	40	30	35	15
à 3000m																												
Vent (km/h)	10	5	10	10	10	10	10	15	20	10	15	20	35	25	40	50	80	55	55	90	80	85	75	30	25	10	10	15
à 2000m																												

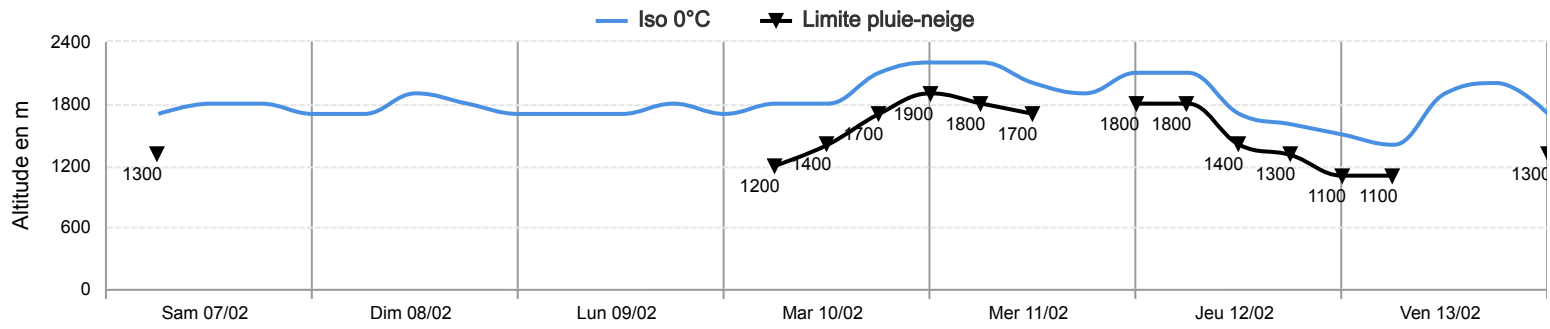

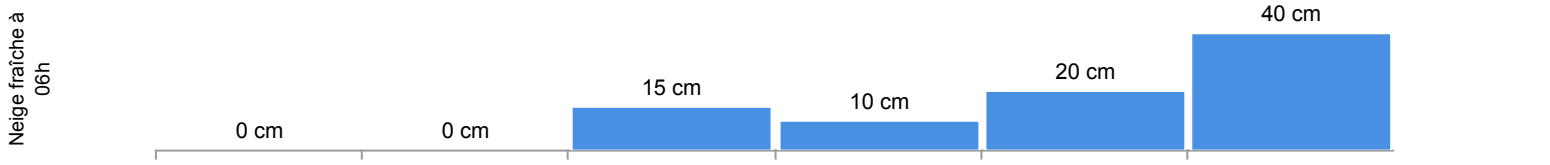

Risque d'avalanche	sam. 07/02	dim. 08/02	lun. 09/02	mar. 10/02	mer. 11/02	jeu. 12/02	ven. 13/02
	3	3	2	3	4	4	4

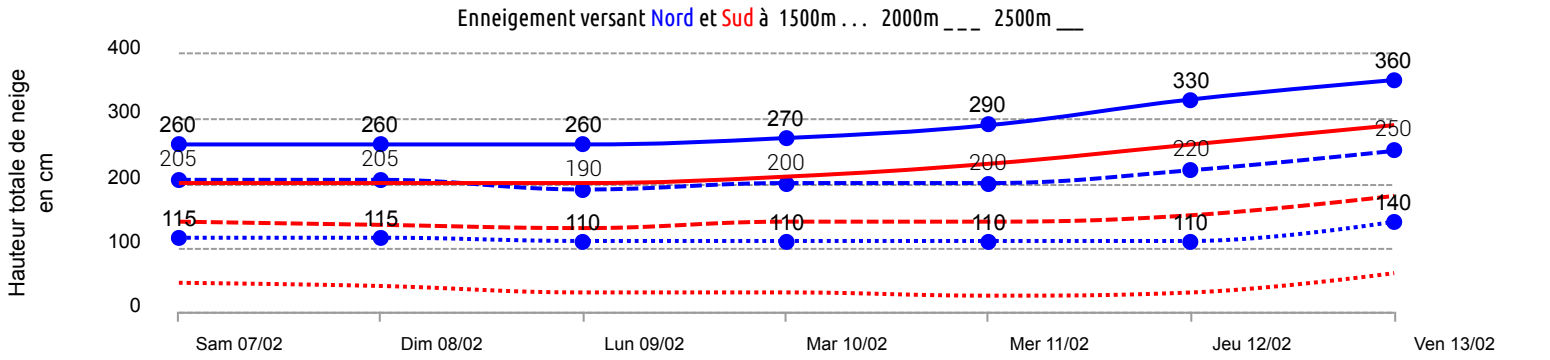

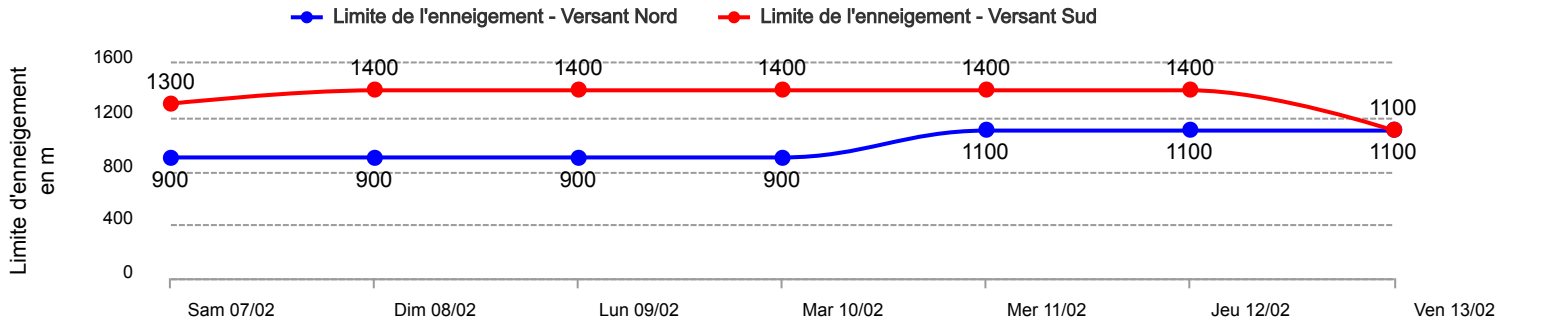

Pour consulter la vigilance en cours, veuillez vous rendre sur le site https://vigilance.meteofrance.fr/fr

Météo-France - 73 avenue de Paris, 94165 Saint-Mandé cedex - Contact : contact@meteo.fr

Rédigé par Météo-France avec la contribution des observateurs du réseau nivo-météorologiques. Partenariat : ANMSM (Maires de Stations de Montagne), DSF (Domaines Skiables de France), ADSP (Directeurs de Pistes et de la Sécurité des Stations de Sports d'Hiver) et autres acteurs de la montagne.

Bulletin neige & avalanches par téléphone au

0 892 68 10 20 Service 0,35 € / min + prix appel