Bulletin d'estimation du risque d'avalanche

(valable en dehors des pistes balisées et ouvertes)

MASSIF : Cerdagne Canigou

Rédigé le vendredi 13 février 2026 à 16h

Estimation des risques pour le : SAMEDI 14 FÉVRIER

ENCORE QUELQUES STRUCTURES DE PLAQUES EN ALTITUDE

2

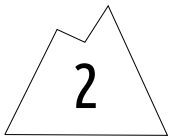

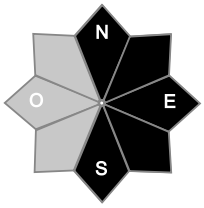

Indice de risque limité.

Départs spontanés : En altitude, peu probable ou par surcharge de neige par le vent; avalanches de fond sous 2000 m

Déclenchements provoqués : Fines plaques à vent en altitude

Indices de risque : 5 très fort - 4 fort - 3 marqué - 2 limité - 1 faible -- En noir : les pentes les plus dangereuses

Stabilité du manteau neigeux

Situation avalancheuse typique : neige ventée — avalanches de fond

Déclenchements provoqués :
Surtout en altitude, des structures de plaques dures, encore déclenchables sont présentes et se forment en journée avec le vent de nord-ouest et les quelques précipitations neigeuses. Elles sont surtout dans un large secteur Est (du nord au sud en passant par l'est), généralement fines, et pourront mener à des avalanches de taille 1 à 2 (petites à moyennes).
Observable : zone d'accumulations dures sous le vent, neige travaillée par le vent en surface.

Départs spontanés :
En altitude, peu probable ou par surcharge de neige par le vent dans les pentes d'un large secteur Nord-Est à Sud-Est d'altitude.
En dessous de 2000m environ, des avalanches de fond peuvent encore se produire en toutes orientations et à toute heure. Elle pourront générer des avalanches de taille petite à moyenne (taille 1 à 2)
Observable : Large fissure d'apparition récente en pentes herbeuses / dalles rocheuses.

Qualité de la neige

Enneigement :
Après plusieurs hivers déficitaires, l'enneigement sur le massif en cette mi-Février demeure largement au-dessus des normales et nettement supérieur à celui des cinq dernières années.
Malgré le fort redoux du début de semaine, la limite de skiabilité se situe encore au plus bas vers 1300/1400 m dans les meilleures configurations. On peut skier plus confortablement vers 1500/1600m

État de la neige :
Au petit matin, un peu de neige récente très ventée recouvrira en dessous de 2000m une neige croutée plus ou moins portante. En altitude, on trouvera une neige souvent dure et travaillée par le vent, pas forcément agréable à skier. Au son cœur, le manteau neigeux restera encore souvent imbibé d'eau liquide en dessous de 2000 m et les skis pourront coller quand en surface ils auront rencontré une neige plus froide.

Aperçu météo pour le samedi 14 février

En marge des chutes de neige venant du nord-ouest. Renforcement du vent de nord-ouest restant fort toute la journée de samedi.

	nuit	matin	après-midi	soir
Pluie-Neige	1 300 m	1 200 m	1 200 m	
Iso 0 °C	1 700 m	1 700 m	1 800 m	1 600 m
Vent 2000 m	↘ 70 km/h	↘ 70 km/h	↘ 80 km/h	↘ 80 km/h
Vent 3000 m	↓ 90 km/h	↓ 90 km/h	↘ 100 km/h	↘ 100 km/h

Épaisseur de neige hors-piste

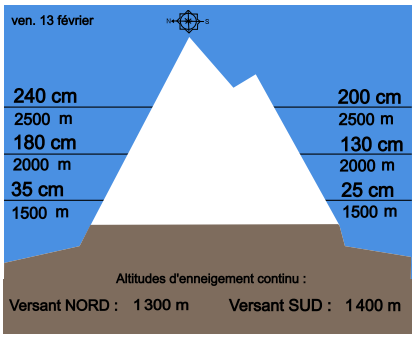

Précipitations à 1800 m

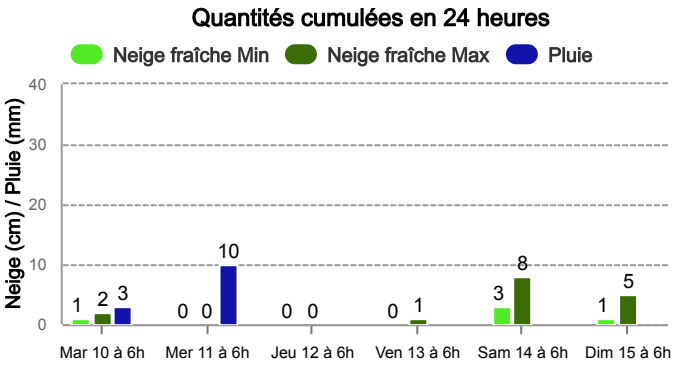

Tendance du dimanche 15 février

3

Indice de risque marqué

Risque stationnaire avec de nouvelles précipitations dimanche et une limite pluie-neige en hausse.

Pour consulter la vigilance en cours, veuillez vous rendre sur le site https://vigilance.meteofrance.fr/fr

Météo-France - 73 avenue de Paris, 94165 Saint-Mandé cedex - Contact : contact@meteo.fr

Rédigé par Météo-France avec la contribution des observateurs du réseau nivo-météorologiques. Partenariat : ANMSM (Maires de Stations de Montagne), DSF (Domaines Skiables de France), ADSP (Directeurs de Pistes et de la Sécurité des Stations de Sports d'Hiver) et autres acteurs de la montagne.

Bulletin neige & avalanches par téléphone au 0 892 68 10 20 Service 0,35 € / min + prix appel

RÉPUBLIQUE FRANÇAISE
Liberté Égalité Fraternité

METEO FRANCE
À VOS CÔTÉS, DANS UN CLIMAT QUI CHANGE

Bulletin d'estimation du risque d'avalanche

(valable en dehors des pistes balisées et ouvertes)

MASSIF : Cerdagne Canigou

Rédigé le vendredi 13 février 2026 à 16h

Conditions nivo-météo des 7 derniers jours

	sam. 07/02				dim. 08/02				lun. 09/02				mar. 10/02				mer. 11/02				jeu. 12/02				ven. 13/02			
	03h	09h	15h	21h	03h	09h	15h	21h	03h	09h	15h	21h	03h	09h	15h	21h	03h	09h	15h	21h	03h	09h	15h	21h	03h	09h	15h	21h
Météo																												
Vent (km/h)	30	20	25	50	55	50	50	40	50	35	55	45	50	50	55	60	75	75	60	70	90	120	115	80	75	85	60	90
à 3000m																												
Vent (km/h)	20	15	15	40	45	40	35	25	30	20	25	20	30	30	30	40	45	45	35	50	65	90	90	55	45	50	35	60
à 2000m																												

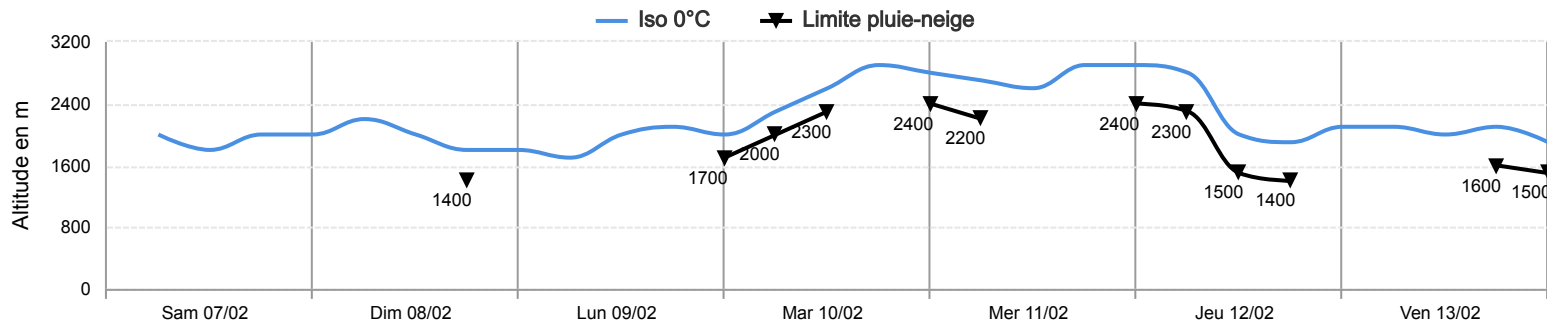

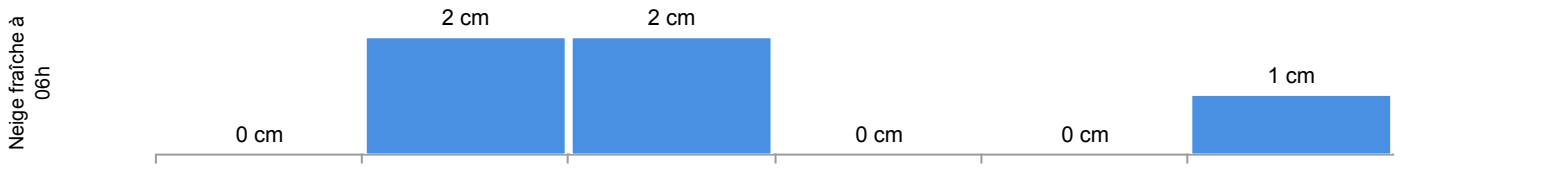

Risque d'avalanche	sam. 07/02	dim. 08/02	lun. 09/02	mar. 10/02	mer. 11/02	jeu. 12/02	ven. 13/02
	2	2	2	2	3	2	2

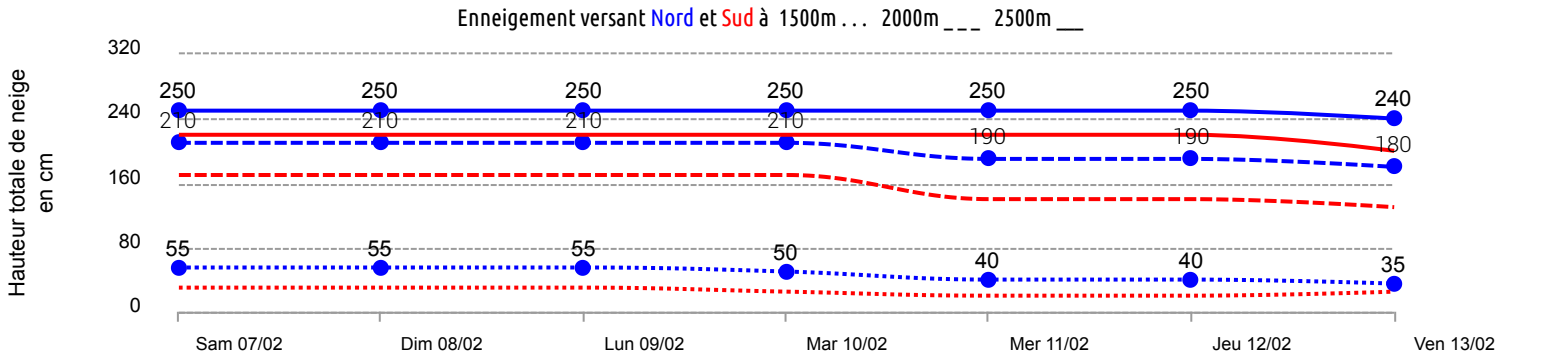

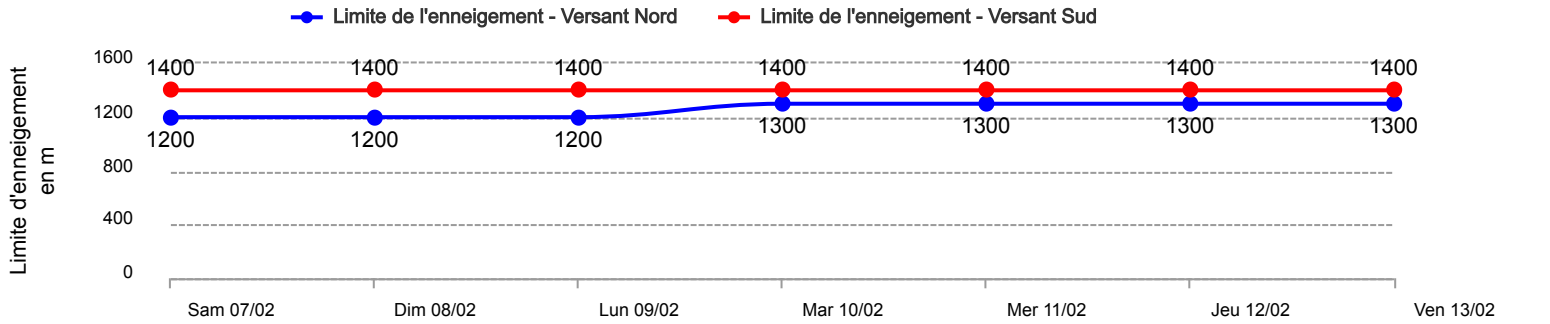

Pour consulter la vigilance en cours, veuillez vous rendre sur le site https://vigilance.meteofrance.fr/fr

Météo-France - 73 avenue de Paris, 94165 Saint-Mandé cedex - Contact : contact@meteo.fr

Bulletin neige & avalanches par téléphone au **0 892 68 10 20** Service 0,35 € / min + prix appel

Rédigé par Météo-France avec la contribution des observateurs du réseau nivo-météorologiques. Partenariat : ANMSM (Maires de Stations de Montagne), DSF (Domaines Skiables de France), ADSP (Directeurs de Pistes et de la Sécurité des Stations de Sports d'Hiver) et autres acteurs de la montagne.