Bulletin d'estimation du risque d'avalanche
(valable en dehors des pistes balisées et ouvertes)

MASSIF : Chablais

Rédigé le vendredi 13 février 2026 à 16h

Estimation des risques pour le : SAMEDI 14 FÉVRIER

3

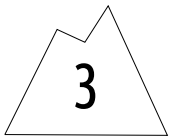

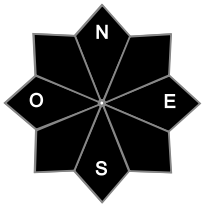

Indice de risque marqué.

Départs spontanés : quelques plaques de fond

Déclenchements provoqués : encore des plaques friables, surtout en altitude

Indices de risque : 5 très fort - 4 fort - 3 marqué - 2 limité - 1 faible -- En noir : les pentes les plus dangereuses

Stabilité du manteau neigeux

Situation avalancheuse typique : neige fraîche couche fragile persistante

Déclenchements provoqués :

* **encore des plaques friables dans l'épaisse couche de neige récente.** Plaques possibles toutes orientations, surtout NW, N, NE, E, à fortiori au-dessus de 1800 m et aux endroits propices au transport par le vent. Le vent a soufflé d'W à S jeudi-vendredi, puis de SE la nuit de vendredi à samedi, puis tournant N samedi en journée. **Taille 2 à 3 (moyenne à grande).** Distinctions géographiques : plutôt des plaques à vent (semi-dures) sur les secteurs frontière suisse et Cornettes de Bise. Plutôt des plaques friables de neige récente sur le reste du Chablais et Haut-Giffre.
* facteur aggravant : en versants NW/N/NE/E, au-dessus de 2000 m, possibles **départs en cascade** : une première avalanche de surface peut solliciter l'ancienne couche fragile persistante enfouie et décrocher une plaque épaisse en blocs (cassure 1m à 1,50m, taille 3+).
* attention aux **corniches** formées récemment, grosses et fragiles.

Départs spontanés :

* quelques plaques de fond possibles à toute heure en dessous de 2000 m. Sur pentes très raides, lisses, herbeuses. Taille 2, voire 3.

Qualité de la neige

Enneigement : bon. On peut chausser les skis vers 1200/1400 m. Nombreuses congères et grosses corniches.

Qualité de la neige ce samedi :

- épaisse couche de neige récente, 40/60 cm en cours de tassement. Elle est restée assez froide en versants N, mais a déjà pris un petit coup de chaud en adrets ce vendredi matin, fine croûte probable. Neige travaillée par le vent de SW en altitude (tournant N samedi en journée).
- en dessous de 1500/1800 m, le fond est encore lourd suite aux pluies de mardi/mercredi.

Aperçu météo pour le samedi 14 février

	nuit	matin	après-midi	soir

Nuageux le matin. Averses de neige l'après-midi. -2/-3 DG vers 2000 m.

Pluie-Neige			1 200 m	1 000 m
Iso 0 °C	1 800 m	1 600 m	1 400 m	1 200 m
Vent 2000 m	← 10 km/h	↙ 10 km/h	↓ 20 km/h	↓ 30 km/h
Vent 2500 m	← 20 km/h	↙ 20 km/h	↓ 30 km/h	↓ 40 km/h

Épaisseur de neige hors-piste

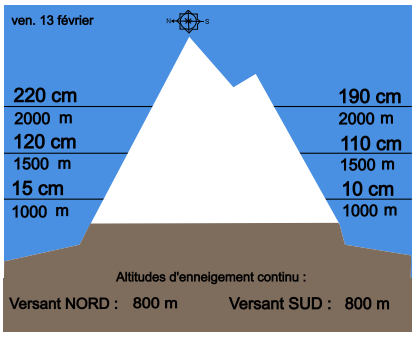

Précipitations à 1800 m

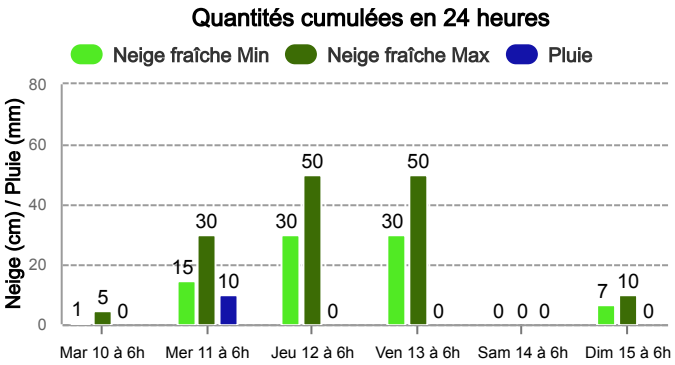

Tendance du dimanche 15 février

3

Indice de risque marqué

Risque stationnaire ou en légère baisse.
Encore des plaques friables.

Pour consulter la vigilance en cours, veuillez vous rendre sur le site https://vigilance.meteofrance.fr/fr

Météo-France - 73 avenue de Paris, 94165 Saint-Mandé cedex - Contact : contact@meteo.fr

Rédigé par Météo-France avec la contribution des observateurs du réseau nivo-météorologiques. Partenariat : ANMSM (Maires de Stations de Montagne), DSF (Domaines Skiables de France), ADSP (Directeurs de Pistes et de la Sécurité des Stations de Sports d'Hiver) et autres acteurs de la montagne.

Bulletin neige & avalanches par téléphone au

0 892 68 10 20 Service 0,35 € / min + prix appel

Bulletin d'estimation du risque d'avalanche

(valable en dehors des pistes balisées et ouvertes)

MASSIF : Chablais

Rédigé le vendredi 13 Février 2026 à 16h

Conditions nivo-météo des 7 derniers jours

	sam. 07/02				dim. 08/02				lun. 09/02				mar. 10/02				mer. 11/02				jeu. 12/02				ven. 13/02			
	03h	09h	15h	21h	03h	09h	15h	21h	03h	09h	15h	21h	03h	09h	15h	21h	03h	09h	15h	21h	03h	09h	15h	21h	03h	09h	15h	21h
Météo																												
Vent (km/h)	20	10	10	10	10	10	15	5	5	20	35	50	60	60	60	75	90	70	70	90	80	80	70	50	50	40	40	30
à 2500m																												
Vent (km/h)	10	5	5	5	5	5	10	5	5	15	25	45	45	45	45	60	60	55	55	60	55	50	50	40	40	30	30	20
à 2000m																												

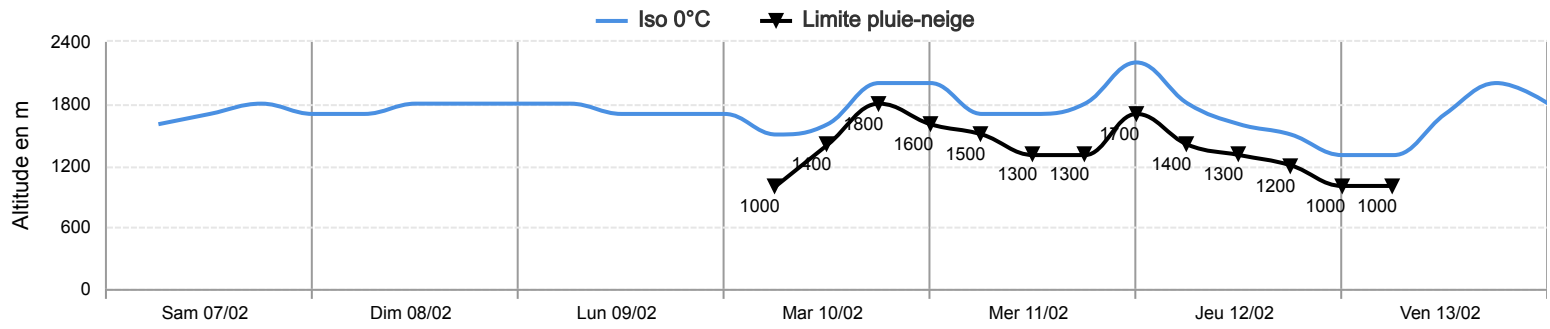

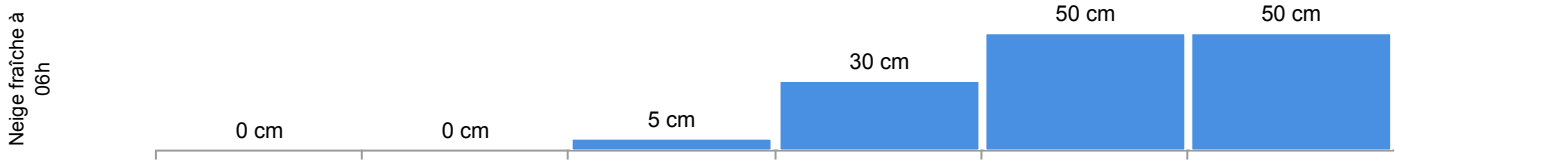

Risque d'avalanche	sam. 07/02	dim. 08/02	lun. 09/02	mar. 10/02	mer. 11/02	jeu. 12/02	ven. 13/02
	3	2	2	3	4	5	4

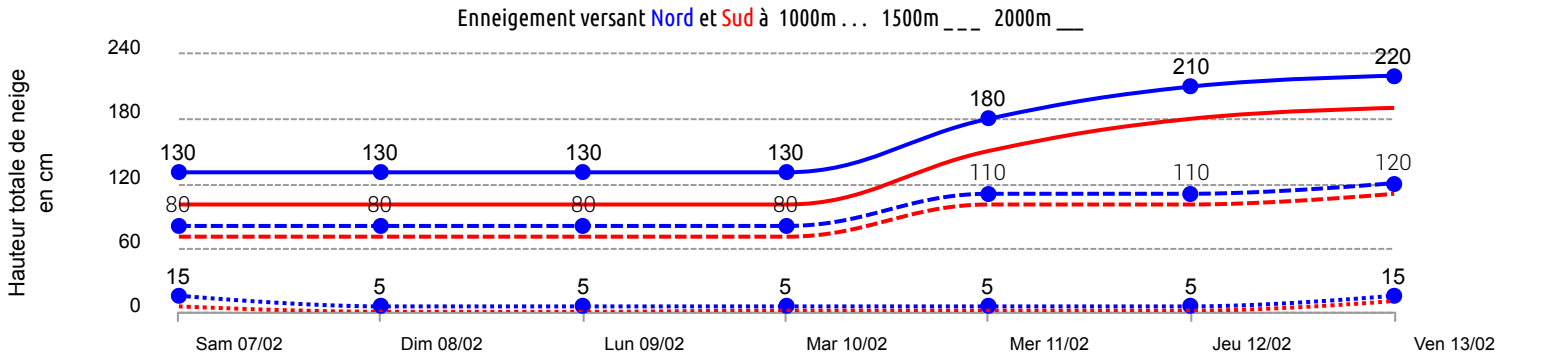

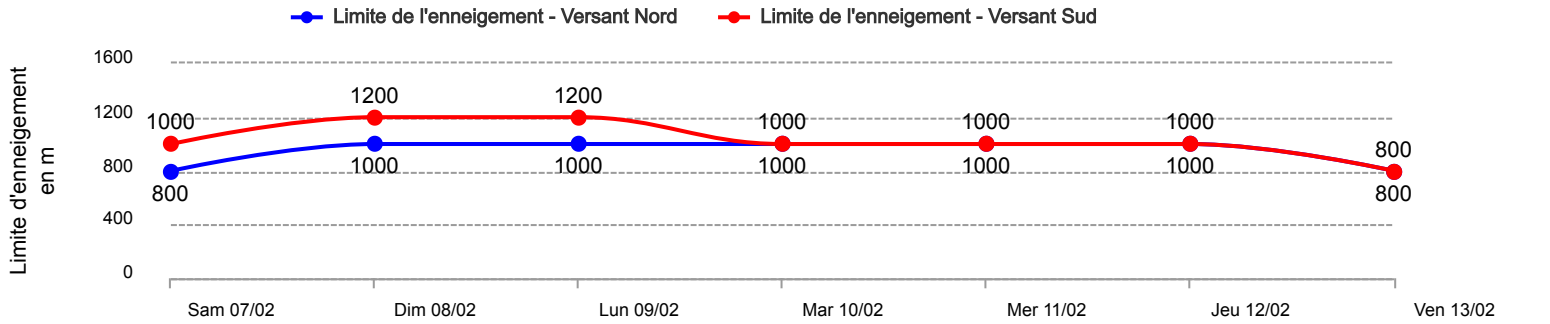

Pour consulter la vigilance en cours, veuillez vous rendre sur le site https://vigilance.meteofrance.fr/fr

Météo-France - 73 avenue de Paris, 94165 Saint-Mandé cedex - Contact : contact@meteo.fr

Rédigé par Météo-France avec la contribution des observateurs du réseau nivo-météorologiques. Partenariat : ANMSM (Maires de Stations de Montagne), DSF (Domaines Skiables de France), ADSP (Directeurs de Pistes et de la Sécurité des Stations de Sports d'Hiver) et autres acteurs de la montagne.

Bulletin neige & avalanches par téléphone au 0 892 68 10 20 Service 0,35 € / min + prix appel