Bulletin d'estimation du risque d'avalanche

(valable en dehors des pistes balisées et ouvertes)

MASSIF : Couserans

Rédigé le vendredi 13 février 2026 à 16h

Estimation des risques pour le : SAMEDI 14 FÉVRIER

MANTEAU DEVENANT DE PLUS EN PLUS INSTABLE AU COURS DE LA JOURNÉE AVEC DES CUMULS DE NEIGE DEVENANT CONSÉQUENTS

3

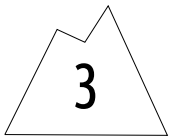

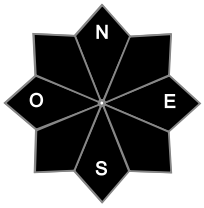

Indice de risque marqué.

Départs spontanés : Avalanches au fur et à mesure des chutes de neige, départs ponctuels ou linéaires

Déclenchements provoqués : Nombreuses instabilités dans les chutes de neige fraiche ventées conséquentes

Indices de risque : 5 très fort - 4 fort - 3 marqué - 2 limité - 1 faible -- En noir : les pentes les plus dangereuses

Stabilité du manteau neigeux

Situation avalancheuse typique : neige fraîche

Épisode de neige démarrant vendredi soir et se poursuivant jusque dans la nuit de samedi à dimanche avec des cumuls de neige fraiche conséquents de 30 à 50 cm et localement plus sur l'épisode.

Déclenchements provoqués :
En tous versants, des déclenchements d'avalanche sont facilement déclenchables au passage d'un skieur. De nouvelles structures de plaques se forment dans la neige récente au fil des chutes de neige, parfois même loin des crêtes. Elles peuvent être difficilement identifiables, car potentiellement d'aspect poudreux. Les avalanches seront le plus souvent de taille petite à moyenne. Elles pourraient même devenir grandes à partir la mi-journée, notamment dans les pentes d'un large secteur Nord-Est à Sud-Est d'altitude, favorables aux accumulations, avec le vent de nord-ouest qui reste soutenu tout au long de la journée.
Observables : quantité de neige fraiche, fissures sous les skis, couverture de neige hétérogène en surface.

Départs spontanés :
En cours de journée de samedi, avec les cumuls de neige devenant importants, des départs ponctuels et plus rarement linéaires, sont à attendre dans les pentes raides en tous versants. Ces avalanches pourront alors emporter l'ensemble des chutes de neige en cours et seront de taille petite à moyenne et parfois grande, dans les pentes d'un large secteur Nord-Est à Sud-Est, propices aux accumulations.

Qualité de la neige

Enneigement :
Après plusieurs hivers déficitaires, l'enneigement sur le massif pour mi-février est légèrement au-dessus des normales et nettement supérieures à celui des cinq dernières années. Le nouvel épisode neigeux commençant vendredi soir va redonner un bel aspect hivernal après le redoux de cette semaine.

Qualité de la neige :
Samedi matin, la montagne retrouve un aspect bien blanc dès 1100 m d'altitude. On trouvera quelques cm dès 1100 m et déjà 10/15 cm dès 1500 m. Cette couche de neige fraîche va devenir de plus en plus épaisse en cours de journée avec les précipitations qui se poursuivent pour atteindre 30/50 cm dès 1500 m et localement plus à l'intérieur des massifs et au-dessus de 1800m. Le fort vent de nord-ouest va venir travailler cette neige récente avec certainement une couverture très hétérogène, avec des accumulations conséquentes sur les versants Est.

Aperçu météo pour le samedi 14 février

Chutes de neige conséquentes démarrant vendredi soir et s'accompagnant d'un fort vent de nord à nord-ouest.

	nuit	matin	après-midi	soir
Pluie-Neige	1 100 m	1 100 m	900 m	600 m
Iso 0 °C	1 400 m	1 400 m	1 300 m	1 000 m
Vent 2000 m	65 km/h	70 km/h	65 km/h	60 km/h
Vent 3000 m	90 km/h	90 km/h	90 km/h	85 km/h

Épaisseur de neige hors-piste

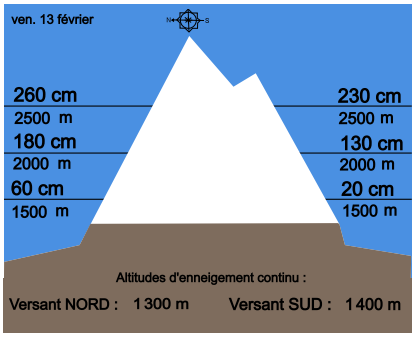

Précipitations à 1800 m

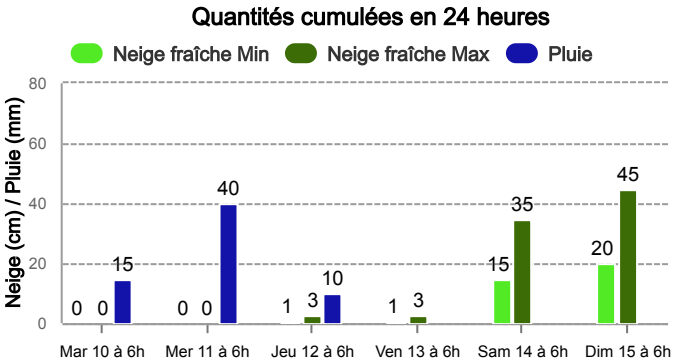

Tendance du dimanche 15 février

Indice de risque fort

Risque potentiellement en hausse en fonction des quantité de précipitations et l'humidification de la neige dimanche.

Pour consulter la vigilance en cours, veuillez vous rendre sur le site https://vigilance.meteofrance.fr/fr

Météo-France - 73 avenue de Paris, 94165 Saint-Mandé cedex - Contact : contact@meteo.fr

Rédigé par Météo-France avec la contribution des observateurs du réseau nivo-météorologiques. Partenariat : ANMSM (Maires de Stations de Montagne), DSF (Domaines Skiables de France), ADSP (Directeurs de Pistes et de la Sécurité des Stations de Sports d'Hiver) et autres acteurs de la montagne.

Bulletin neige & avalanches par téléphone au

0 892 68 10 20 Service 0,35 € / min + prix appel

RÉPUBLIQUE FRANÇAISE
Liberté Égalité Fraternité

METEO FRANCE
À VOS CÔTÉS, DANS UN CLIMAT QUI CHANGE

Bulletin d'estimation du risque d'avalanche

(valable en dehors des pistes balisées et ouvertes)

MASSIF : Couserans

Rédigé le vendredi 13 Février 2026 à 16h

Conditions nivo-météo des 7 derniers jours

	sam. 07/02				dim. 08/02				lun. 09/02				mar. 10/02				mer. 11/02				jeu. 12/02				ven. 13/02			
	03h	09h	15h	21h	03h	09h	15h	21h	03h	09h	15h	21h	03h	09h	15h	21h	03h	09h	15h	21h	03h	09h	15h	21h	03h	09h	15h	21h
Météo																												
Vent (km/h)	30	20	20	55	55	25	50	45	40	40	60	50	40	45	50	65	70	60	65	70	95	100	90	70	75	80	70	80
à 3000m																												
Vent (km/h)	20	15	15	40	45	10	45	40	35	25	50	30	30	30	40	45	50	35	40	55	65	80	75	40	40	55	35	65
à 2000m																												

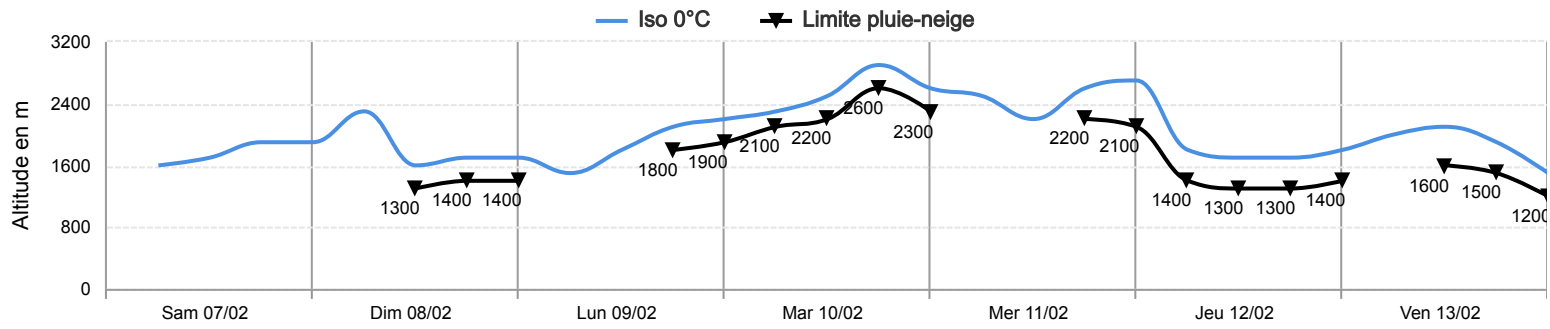

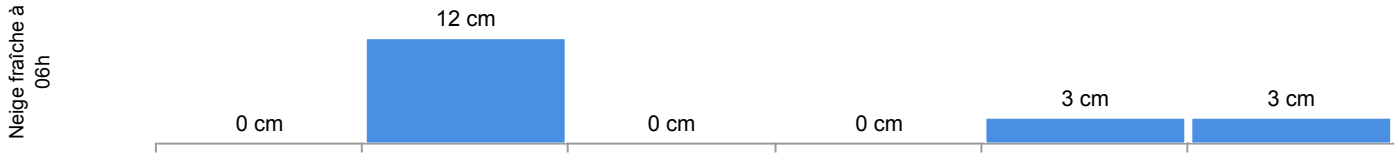

Risque d'avalanche	sam. 07/02	dim. 08/02	lun. 09/02	mar. 10/02	mer. 11/02	jeu. 12/02	ven. 13/02
	2	2	2	4	4	3	2

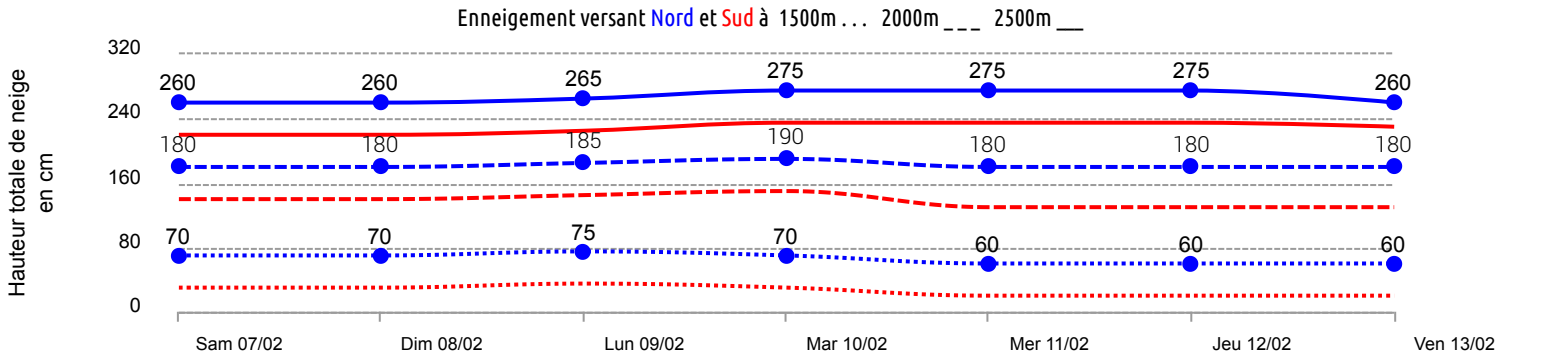

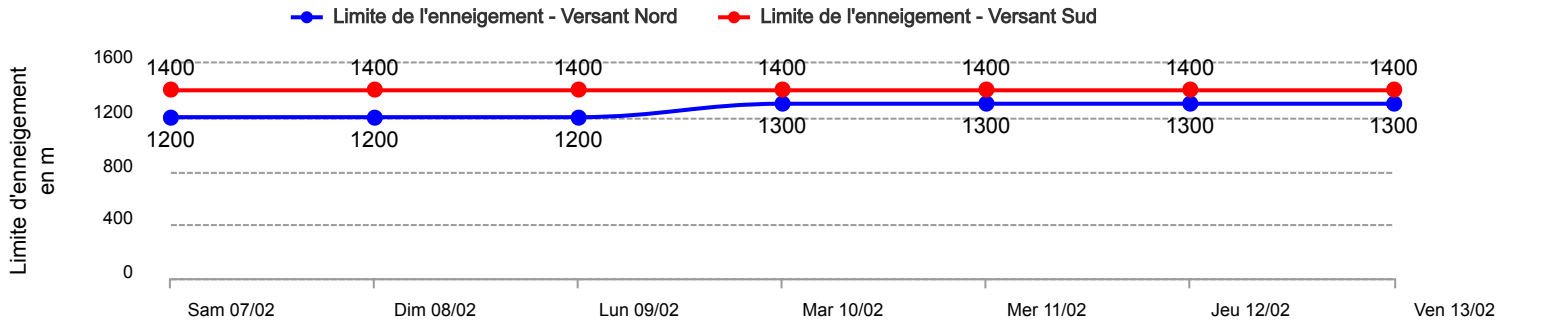

Pour consulter la vigilance en cours, veuillez vous rendre sur le site https://vigilance.meteofrance.fr/fr

Météo-France - 73 avenue de Paris, 94165 Saint-Mandé cedex - Contact : contact@meteo.fr

Rédigé par Météo-France avec la contribution des observateurs du réseau nivo-météorologiques. Partenariat : ANMSM (Maires de Stations de Montagne), DSF (Domaines Skiables de France), ADSP (Directeurs de Pistes et de la Sécurité des Stations de Sports d'Hiver) et autres acteurs de la montagne.

Bulletin neige & avalanches par téléphone au

0 892 68 10 20 Service 0,35 € / min + prix appel