Bulletin d'estimation du risque d'avalanche

(valable en dehors des pistes balisées et ouvertes)

MASSIF : Mont-Blanc

Rédigé le vendredi 13 février 2026 à 16h

Estimation des risques pour le : SAMEDI 14 FÉVRIER

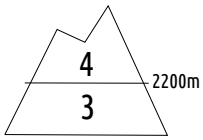

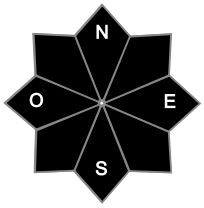

Au-dessus de 2200m indice de risque fort, plus bas indice marqué.

Départs spontanés : rares grandes avalanches encore possibles

Déclenchements provoqués : encore des plaques épaisses dans la neige récente + travaillée par le Foehn

Indices de risque : 5 très fort - 4 fort - 3 marqué - 2 limité - 1 faible -- En noir : les pentes les plus dangereuses

Stabilité du manteau neigeux

Situation avalancheuse typique : neige ventée couche fragile persistante

Déclenchements provoqués :

* **encore des plaques dans l'épaisse couche de neige récente** malgré une relative stabilisation progressive par tassement. Plaques friables ou dures selon les secteurs. La plupart se trouvent en zones propices au travail par le vent. Le vent a soufflé de SW/W jeudi, puis de S/Foehn la nuit de vendredi à samedi. Zones les plus concernées : intérieur du massif + Miages/Tondu + frontière suisse + Aiguilles Rouges au-dessus de 2200 m. Cassure épaisse, gros dépôt. Taille 2 à 3 (moyenne à grande).
* facteur aggravant : la présence d'une couche fragile persistante, enfouie dans les versants NW/N/NE/E au-dessus de 2000 m. Plutôt difficile à atteindre à skis car elle est enfouie assez profondément, mais en cas d'**avalanches en cascade** (une première de surface en déclenche une seconde plus épaisse), **cassure 1 à 2 m possible**. Taille 3+.
* attention aux **corniches** formées récemment, grosses et fragiles.

Départs spontanés :

* ruptures de plaques dans les pentes raides ou couloirs surchargées par le vent de Foehn, surtout la nuit de vendredi à samedi et samedi matin. Principalement dans un large secteur N. Taille 2, éventuellement 3 dans un grand ubac.
* rares plaques de fond possibles à toute heure en dessous de 2000 m. Sur pentes très raides, lisses, herbeuses. Taille 2.

Qualité de la neige

Enneigement : bon. On peut chausser les skis vers 1200/1400 m. Nombreuses congères et grosses corniches.

Qualité de la neige ce samedi :

- épaisse couche de neige récente (70 à 120 cm). Elle est restée froide en ubacs, mais déjà un peu croûtée en adrets de moyenne-montagne suite au soleil tiède de vendredi matin. Neige travaillée par le Foehn la nuit de vendredi à samedi, surtout au-dessus de 2200 m.
- sous 1800/2000 m, on retrouve un fond lourd humide en cours de regel.

Aperçu météo pour le samedi 14 février

	nuit	matin	après-midi	soir

Foehn la nuit. Nuageux samedi matin. Averses de neige l'après-midi. -3 DG vers 2000 m.

Pluie-Neige			1 300 m	1 000 m
Iso 0 °C	1 900 m	1 600 m	1 600 m	1 200 m
Vent 2000 m	↖ 20 km/h	↓ 20 km/h	↓ 20 km/h	↓ 20 km/h
Vent 4000 m	↑ 60 km/h	↖ 50 km/h	↓ 40 km/h	↓ 40 km/h

Épaisseur de neige hors-piste

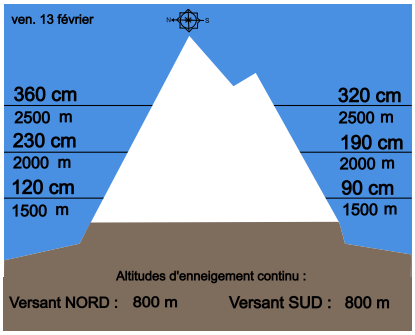

Précipitations à 1800 m

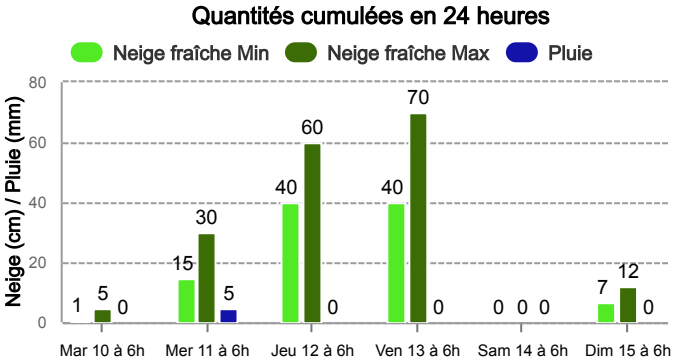

Tendance du dimanche 15 février

Indice de risque marqué

Risque stationnaire ou en légère baisse.

Pour consulter la vigilance en cours, veuillez vous rendre sur le site https://vigilance.meteofrance.fr/fr

Météo-France - 73 avenue de Paris, 94165 Saint-Mandé cedex - Contact : contact@meteo.fr

Rédigé par Météo-France avec la contribution des observateurs du réseau nivo-météorologiques. Partenariat : ANMSM (Maires de Stations de Montagne), DSF (Domaines Skiables de France), ADSP (Directeurs de Pistes et de la Sécurité des Stations de Sports d'Hiver) et autres acteurs de la montagne.

Bulletin neige & avalanches par téléphone au 0 892 68 10 20 Service 0,35 € / min + prix appel

Bulletin d'estimation du risque d'avalanche

(valable en dehors des pistes balisées et ouvertes)

MASSIF : Mont-Blanc

Rédigé le vendredi 13 février 2026 à 16h

Conditions nivo-météo des 7 derniers jours

	sam. 07/02				dim. 08/02				lun. 09/02				mar. 10/02				mer. 11/02				jeu. 12/02				ven. 13/02			
	03h	09h	15h	21h	03h	09h	15h	21h	03h	09h	15h	21h	03h	09h	15h	21h	03h	09h	15h	21h	03h	09h	15h	21h	03h	09h	15h	21h
Météo																												
Vent (km/h)	30	15	15	15	25	15	10	10	10	20	30	40	40	60	90	90	110	90	100	110	100	100	100	80	70	70	80	80
à 4000m																												
Vent (km/h)	10	5	5	5	10	10	5	5	5	5	15	25	35	40	50	55	65	50	50	70	50	50	50	30	30	20	10	10
à 2000m																												

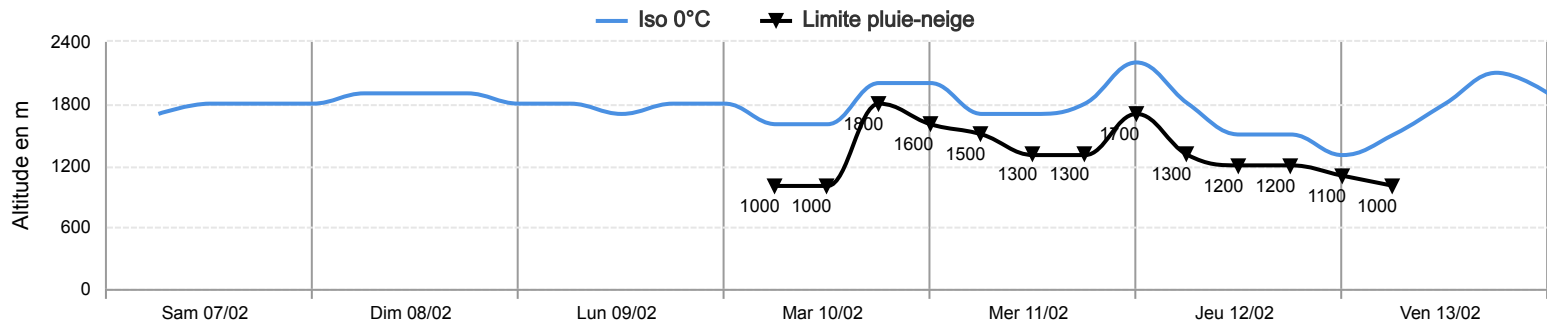

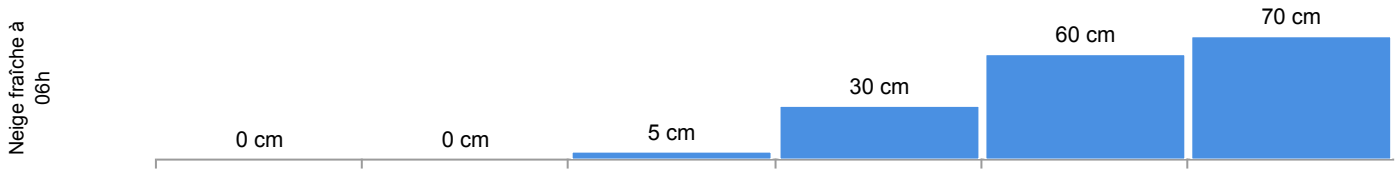

Risque d'avalanche	sam. 07/02	dim. 08/02	lun. 09/02	mar. 10/02	mer. 11/02	jeu. 12/02	ven. 13/02
	3	3	3	3	4	5	4

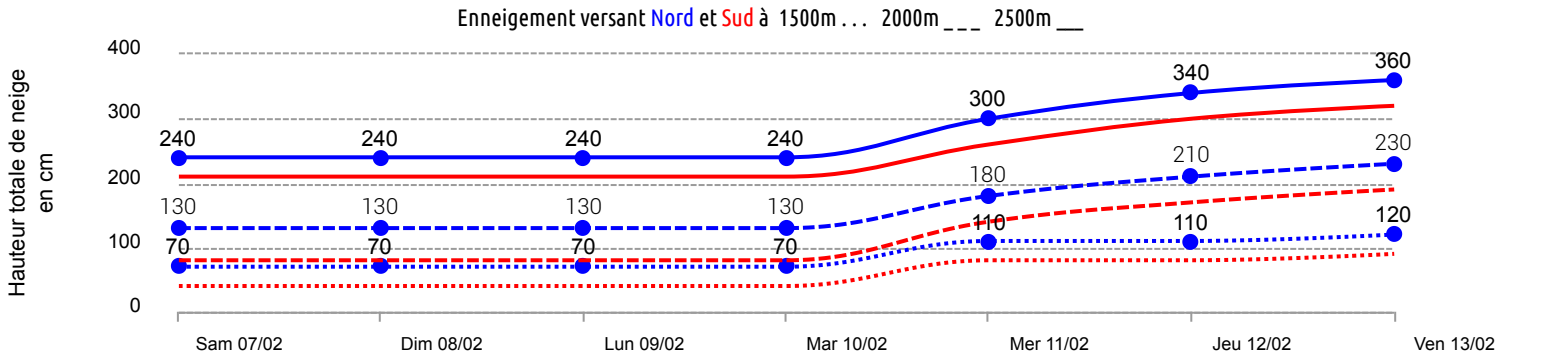

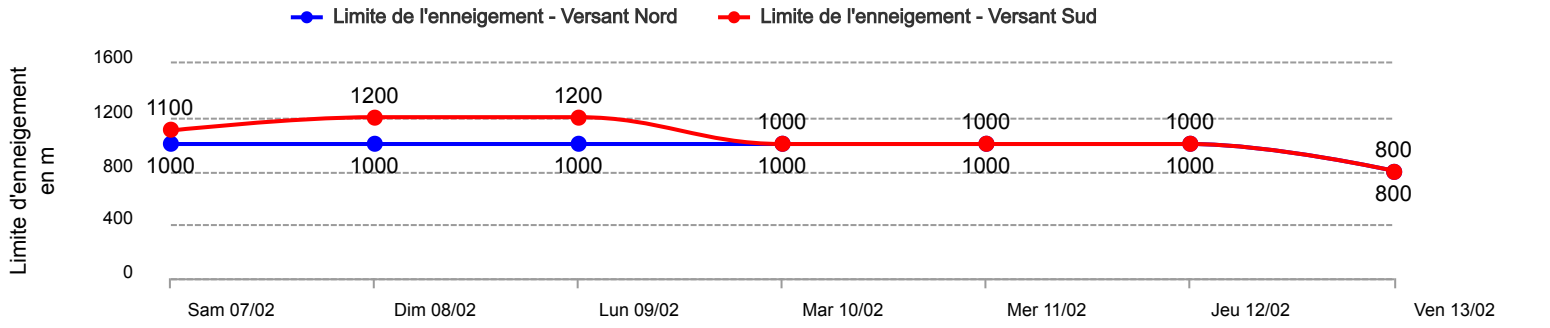

Pour consulter la vigilance en cours, veuillez vous rendre sur le site https://vigilance.meteofrance.fr/fr

Météo-France - 73 avenue de Paris, 94165 Saint-Mandé cedex - Contact : contact@meteo.fr

Rédigé par Météo-France avec la contribution des observateurs du réseau nivo-météorologiques. Partenariat : ANMSM (Maires de Stations de Montagne), DSF (Domaines Skiables de France), ADSP (Directeurs de Pistes et de la Sécurité des Stations de Sports d'Hiver) et autres acteurs de la montagne.

Bulletin neige & avalanches par téléphone au

0 892 68 10 20 Service 0,35 € / min + prix appel