Bulletin d'estimation du risque d'avalanche

(valable en dehors des pistes balisées et ouvertes)

MASSIF : Oisans

Rédigé le vendredi 13 février 2026 à 16h

Estimation des risques pour le : SAMEDI 14 FÉVRIER

FORTE INSTABILITE SURTOUT EN DEPARTS PROVOQUES ET EN ALTITUDE

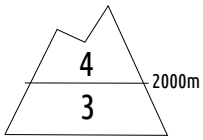

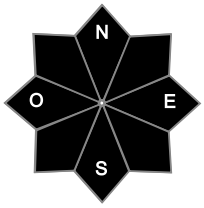

instable en altitude

Au-dessus de 2000m indice de risque fort, plus bas indice marqué.

Départs spontanés : activité spontanée en nette baisse se limitant à quelques pentes très raides/rochers lors d'éclaircies, aux altitudes modestes. Rares départs d'ampleur possible à plus haute altitude encore possible.

Déclenchements provoqués : En altitude fort risque accidentel toujours présent, près des crêtes comme en pleine pente avvec la variation du vent de Sud puis de Nord, la formation de nouvelles plaques s'intensifie.

Indices de risque : 5 très fort - 4 fort - 3 marqué - 2 limité - 1 faible -- En noir : les pentes les plus dangereuses

Stabilité du manteau neigeux

Situation avalancheuse typique :

neige ventée

neige fraîche

Départs spontanés :

Ce risque est en nette baisse par rapport au derniers jours.

Pour samedi, on peut attendre lors de brèves éclaircies, encore quelques coulées ou avalanches poudreuses près des rochers notamment. Aux altitudes modestes (sous 1600/1800m environ), la neige est assez humide en profondeur, on peut avoir quelques avalanches en pentes herbeuses, parfois de fond (glissement au terrain).

En haute montagne (au-dessus de 2200/2400m), la présence de sous couche fragile persistante qui pourrait rendre quelques rares avalanches de très grande ampleur encore possible.

Déclenchements provoqués :

Le risque accidentel reste fort en haute montagne et dès 2000/2200m, de nombreuses plaques encore bien instables, parfois loin des crêtes. Le vent a soufflé en diverses orientations et passe d'un secteur Sud à un secteur Nord en journée de samedi ce qsui favorise la formation de nouvelles plaques.

Dans un large secteur Nord, des sous couches fragiles sont encore enfouies et une première rupture de plaque pourrait entrainer une épaisse et large cassure en contrebas, entrainant un volume de neige très conséquent.

Plus bas que 1800/2000m environ, les sous couches sont un peu mieux stabilisées, risque de plaques surtout à proximité des crêtes, il est globalement plus faible.

Qualité de la neige

Qualification de l'enneigement : L'enneigement s'est encore amélioré en altitude, dans les combes, où il devient excellent pour la saison. Il est en revanche médiocre plus bas que 1400m...

Limites skiables : vers 1100/1300 m...

Qualité de la neige samedi :

Neige fraîche poudreuse plus épaisse en altitude et souvent soufflée/chahutée à l'abord des croupes et crêtes.

A 1100/1300m, fine couche de 5/10cm au matin.

Fortes épaisseurs au dessus de 2200/2500m environ avec plus d'1m de neige récente vers 2500m, de grosses congères/corniches, des secteurs plus dégarnis...

Aperçu météo pour le samedi 14 février

	nuit	matin	après-midi	soir

Journée plutot nuageuse avec de faibles averses de neige et un vent de Nord qui se renforce.

Pluie-Neige	1 100 m		1 200 m	
Iso 0 °C	1 800 m	1 600 m	1 700 m	1 200 m
Vent 2500 m	← 15 km/h	← 20 km/h	↓ 10 km/h	↙ 15 km/h
Vent 3500 m	↖ 20 km/h	↙ 25 km/h	↓ 45 km/h	↓ 50 km/h

Épaisseur de neige hors-piste

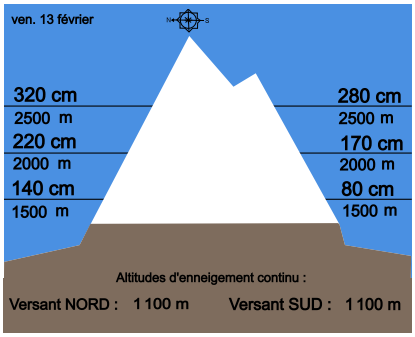

Précipitations à 1800 m

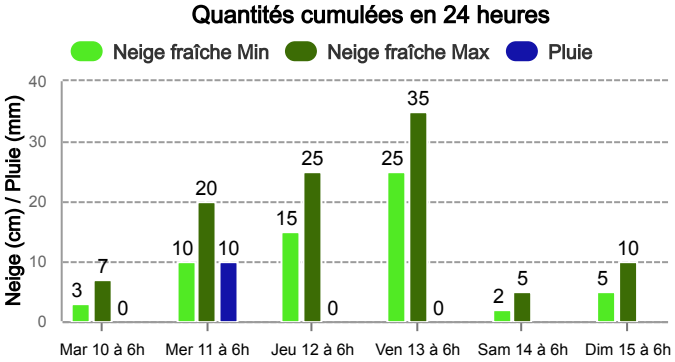

Tendance du dimanche 15 février

Indice de risque fort

Tendance à la stabilisation avec un temps plus calme à venir.

Pour consulter la vigilance en cours, veuillez vous rendre sur le site https://vigilance.meteofrance.fr/fr

Météo-France - 73 avenue de Paris, 94165 Saint-Mandé cedex - Contact : contact@meteo.fr

Rédigé par Météo-France avec la contribution des observateurs du réseau nivo-météorologiques. Partenariat : ANMSM (Maires de Stations de Montagne), DSF (Domaines Skiables de France), ADSP (Directeurs de Pistes et de la Sécurité des Stations de Sports d'Hiver) et autres acteurs de la montagne.

Bulletin neige & avalanches par téléphone au

0 892 68 10 20 Service 0,35 € / min + prix appel

RÉPUBLIQUE FRANÇAISE
Liberté Égalité Fraternité

METEO FRANCE
À VOS CÔTÉS, DANS UN CLIMAT QUI CHANGE

Bulletin d'estimation du risque d'avalanche
(valable en dehors des pistes balisées et ouvertes)

MASSIF : Oisans

Rédigé le vendredi 13 Février 2026 à 16h

Conditions nivo-météo des 7 derniers jours

	sam. 07/02				dim. 08/02				lun. 09/02				mar. 10/02				mer. 11/02				jeu. 12/02				ven. 13/02			
	03h	09h	15h	21h	03h	09h	15h	21h	03h	09h	15h	21h	03h	09h	15h	21h	03h	09h	15h	21h	03h	09h	15h	21h	03h	09h	15h	21h
Météo																												
Vent (km/h)	15	10	10	10	15	25	20	15	15	25	15	20	25	30	45	70	90	100	95	100	110	110	110	35	30	20	25	15
à 3500m																												
Vent (km/h)	10	5	10	10	10	25	10	10	5	20	15	15	15	15	30	45	50	50	70	85	90	100	90	35	25	15	10	10
à 2500m																												

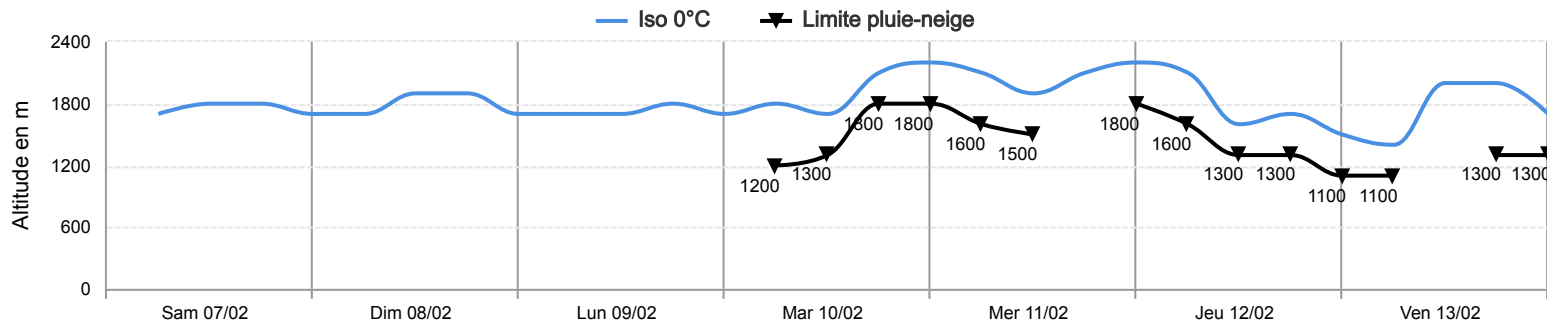

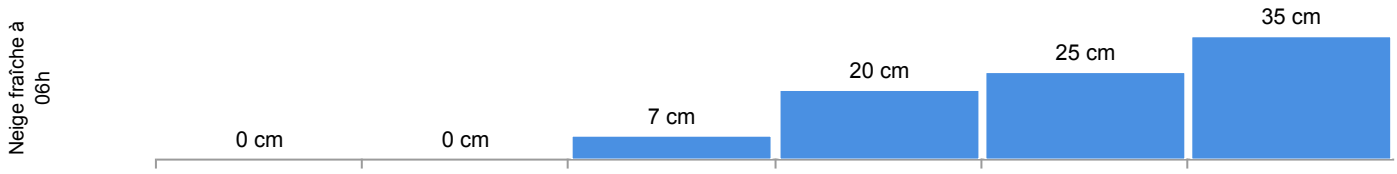

Risque d'avalanche	sam. 07/02	dim. 08/02	lun. 09/02	mar. 10/02	mer. 11/02	jeu. 12/02	ven. 13/02
	3	3	3	3	4	5	4

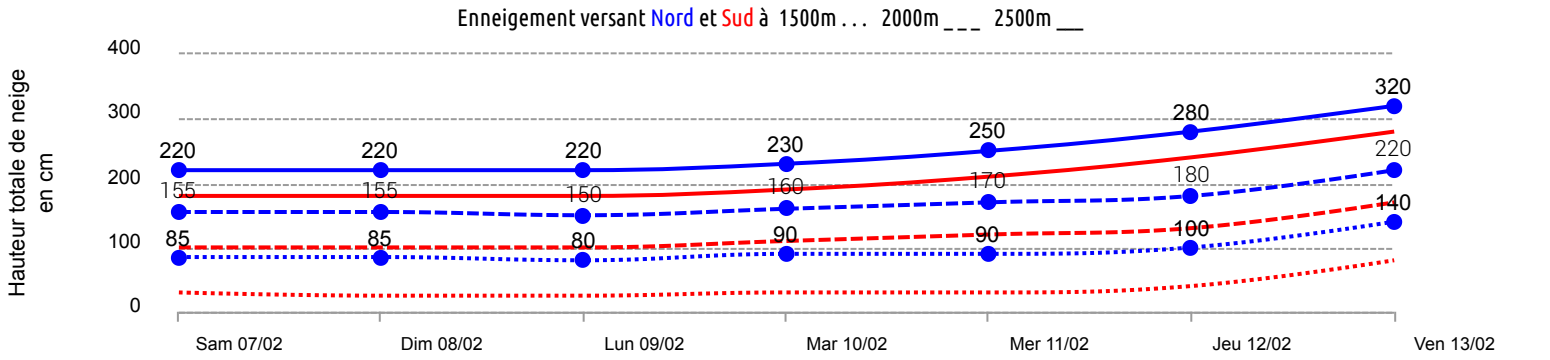

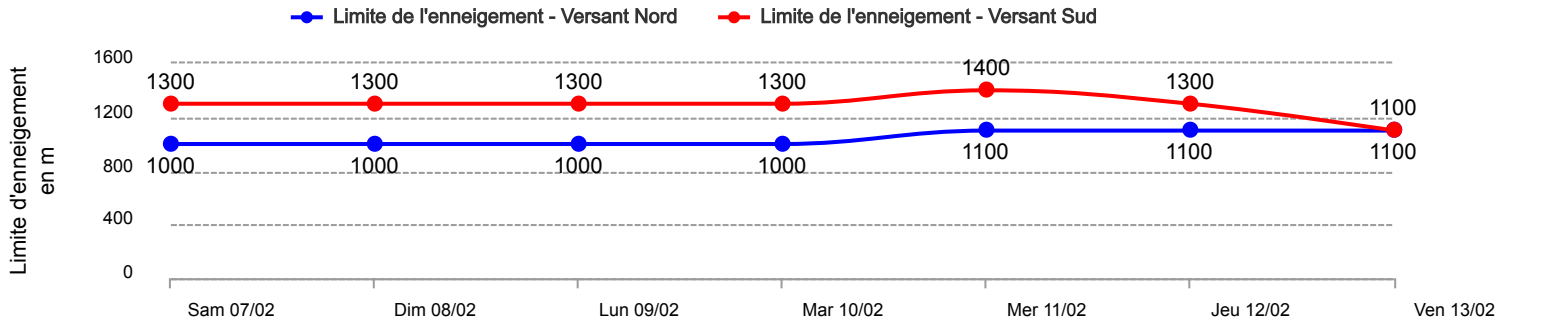

Pour consulter la vigilance en cours, veuillez vous rendre sur le site https://vigilance.meteofrance.fr/fr

Météo-France - 73 avenue de Paris, 94165 Saint-Mandé cedex - Contact : contact@meteo.fr

Rédigé par Météo-France avec la contribution des observateurs du réseau nivo-météorologiques. Partenariat : ANMSM (Maires de Stations de Montagne), DSF (Domaines Skiables de France), ADSP (Directeurs de Pistes et de la Sécurité des Stations de Sports d'Hiver) et autres acteurs de la montagne.

Bulletin neige & avalanches par téléphone au
0 892 68 10 20 Service 0,35 € / min + prix appel