Bulletin d'estimation du risque d'avalanche

(valable en dehors des pistes balisées et ouvertes)

MASSIF : Renoso Incudine

Rédigé le vendredi 13 février 2026 à 16h

Estimation des risques pour le : SAMEDI 14 FÉVRIER

NOUVELLES CHUTES DE NEIGE LA NUIT PROCHAINE, COUCHE RÉCENTE INSTABLE ET FORMATION DE NOUVELLES PLAQUES PAR LE VENT

3

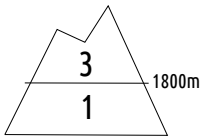

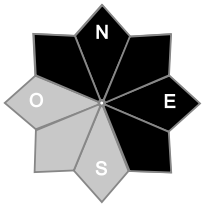

Au-dessus de 1800m indice de risque marqué, plus bas indice faible.

Départs spontanés : Coulées et avalanches de neige sèche surtout au-dessus de 1800 m

Déclenchements provoqués : Formation de nouvelles plaques en altitude, facilement déclenchables

Indices de risque : 5 très fort - 4 fort - 3 marqué - 2 limité - 1 faible -- En noir : les pentes les plus dangereuses

Stabilité du manteau neigeux

Situation avalancheuse typique : neige ventée

Déclenchements provoqués : Cette nuit de vendredi à samedi, des chutes de neige transportées par un vent fort de Sud génèrent de nouvelles plaques au-dessus de 1800 à 2000 m, surtout dans les orientations Nord. Elles s'ajoutent aux anciennes plaques, pas encore bien stabilisées (présence de plusieurs couches fragiles composées de neige roulée plus ou moins enfouies). Localement, les volumes mobilisables peuvent être importants. En altitude, le passage d'un seul skieur suffit à déclencher une plaque.
En dessous de 1800 m, la vieille neige est bien tassée. Les nouvelles plaques en neige humide sont peu épaisses et plus difficiles à solliciter.

Départs spontanés : Cette nuit de vendredi à samedi, au-dessus de 1800 m, les chutes de neige entrainent des coulées et avalanches de neige sèche de taille moyenne, rarement de grandes avalanches (taille 3), dans les zones d'accumulation. En journée de samedi, le risque de départ spontané diminue.

Autres : Risque de glissade en neige dure ou glacée sur les crêtes et sommets balayés par les vents de Sud puis de Nord.

Qualité de la neige

Qualification de l'enneigement : L'enneigement est excellent pour la saison à toutes altitudes. On relève plus de 2 mètres dans les combes abritées.
Limite d'enneigement skiable : vers 1500 m.
État de la neige : Avec les récentes pluies, la neige est devenue humide jusque vers 1600 à 1800 m environ, généralement portante (parfois soupe à basse altitude). En altitude, elle reste sèche, légère et profonde à l'abri du vent d'Ouest. On trouve localement des accumulations de neige roulée. La neige est très changeante (dure, carton, regelée) dans les secteurs ventés. Corniches et accumulations parfois volumineuses en place. Les crêtes et sommets, balayés par le vent d'Ouest, sont souvent durs et glacés.

Aperçu météo pour le samedi 14 février

	nuit	matin	après-midi	soir
	Chutes de neige et vent fort la nuit, averses en journée			
Pluie-Neige	1 500 m	1 600 m	1 600 m	1 600 m
Iso 0 °C	1 800 m	1 900 m	1 900 m	1 900 m
Vent 1500 m	40 km/h	20 km/h	35 km/h	35 km/h
Vent 2000 m	50 km/h	20 km/h	40 km/h	50 km/h

Épaisseur de neige hors-piste

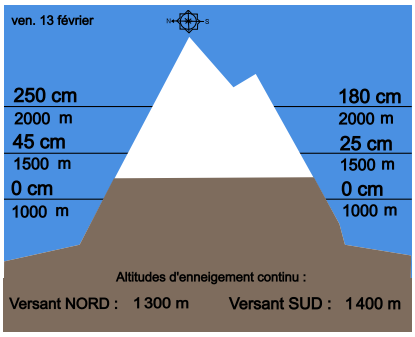

Précipitations à 1800 m

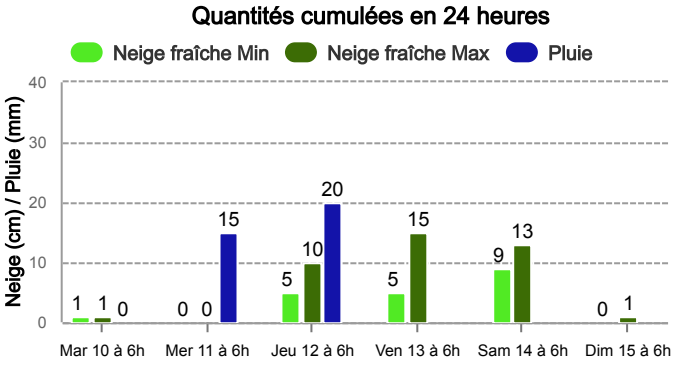

Tendance du dimanche 15 février

3 **Indice de risque marqué**

Temps ensoleillé. Plaques en cours de stabilisation. Risque en baisse.

Pour consulter la vigilance en cours, veuillez vous rendre sur le site https://vigilance.meteofrance.fr/fr

Météo-France - 73 avenue de Paris, 94165 Saint-Mandé cedex - Contact : contact@meteo.fr

Rédigé par Météo-France avec la contribution des observateurs du réseau nivo-météorologiques. Partenariat : ANMSM (Maires de Stations de Montagne), DSF (Domaines Skiables de France), ADSP (Directeurs de Pistes et de la Sécurité des Stations de Sports d'Hiver) et autres acteurs de la montagne.

Bulletin neige & avalanches par téléphone au **0 892 68 10 20** Service 0,35 € / min + prix appel

Bulletin d'estimation du risque d'avalanche

(valable en dehors des pistes balisées et ouvertes)

MASSIF : Renoso Incudine

Rédigé le vendredi 13 février 2026 à 16h

Conditions nivo-météo des 7 derniers jours

	sam. 07/02				dim. 08/02				lun. 09/02				mar. 10/02				mer. 11/02				jeu. 12/02				ven. 13/02			
	03h	09h	15h	21h	03h	09h	15h	21h	03h	09h	15h	21h	03h	09h	15h	21h	03h	09h	15h	21h	03h	09h	15h	21h	03h	09h	15h	21h
Météo																												
Vent (km/h)	55	55	45	50	50	15	30	15	10	5	15	10	20	20	30	50	80	110	120	110	80	120	120	120	60	50	35	70
à 2000m																												
Vent (km/h)	60	45	65	50	60	15	25	15	15	15	15	10	15	15	25	40	60	100	110	100	80	120	130	120	60	45	30	40
à 1500m																												

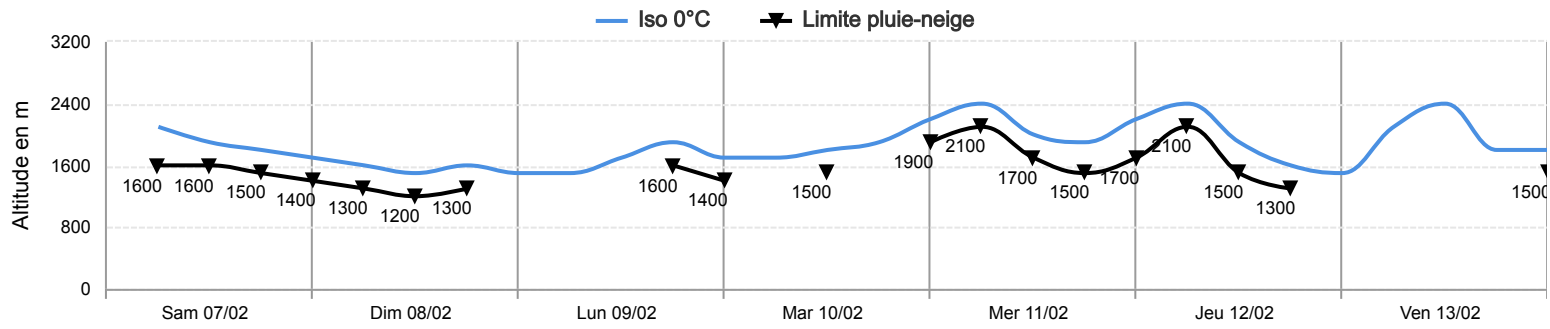

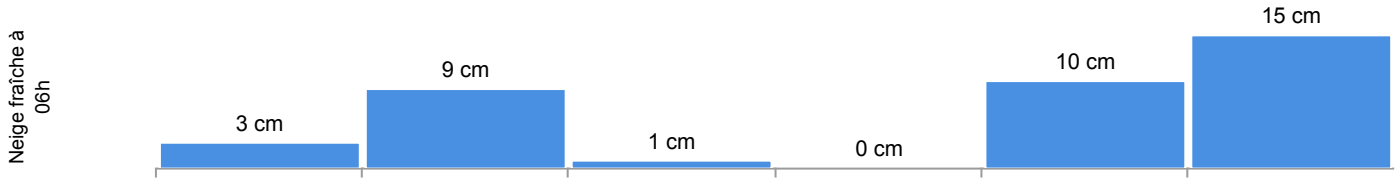

Risque d'avalanche	sam. 07/02	dim. 08/02	lun. 09/02	mar. 10/02	mer. 11/02	jeu. 12/02	ven. 13/02
	3	3	3	2	3	3	3

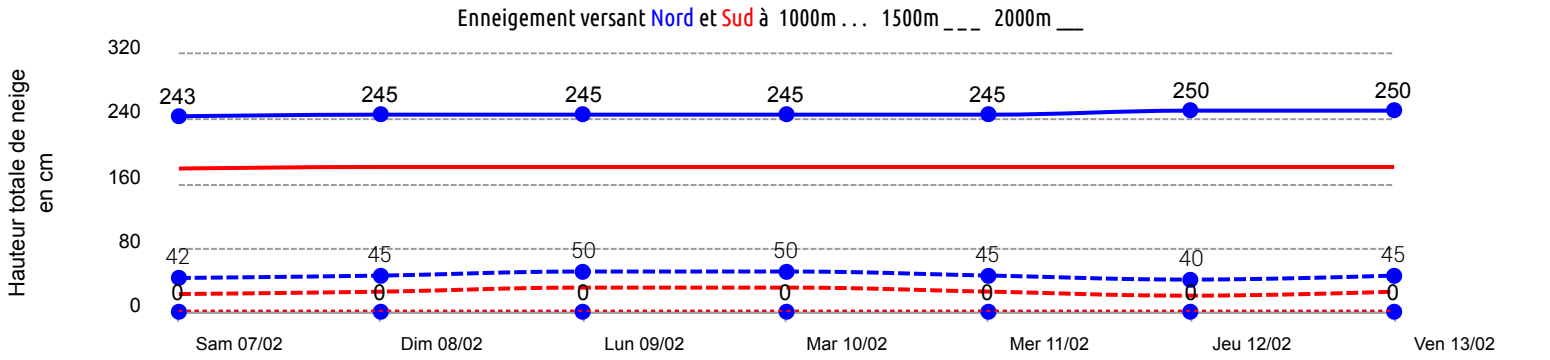

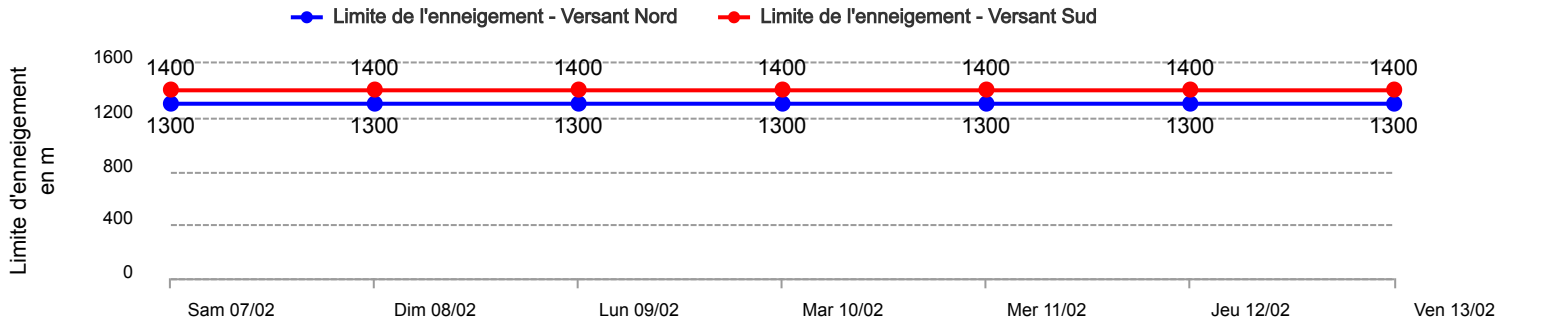

Pour consulter la vigilance en cours, veuillez vous rendre sur le site https://vigilance.meteofrance.fr/fr

Météo-France - 73 avenue de Paris, 94165 Saint-Mandé cedex - Contact : contact@meteo.fr

Rédigé par Météo-France avec la contribution des observateurs du réseau nivo-météorologiques. Partenariat : ANMSM (Maires de Stations de Montagne), DSF (Domaines Skiables de France), ADSP (Directeurs de Pistes et de la Sécurité des Stations de Sports d'Hiver) et autres acteurs de la montagne.

Bulletin neige & avalanches par téléphone au 0 892 68 10 20 Service 0,35 € / min + prix appel