Bulletin d'estimation du risque d'avalanche

(valable en dehors des pistes balisées et ouvertes)

MASSIF : Vercors

Rédigé le vendredi 13 février 2026 à 16h

Estimation des risques pour le : SAMEDI 14 FÉVRIER

NEIGE FRAICHE SOUFFLÉE EN ALTITUDE

3

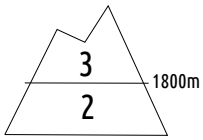

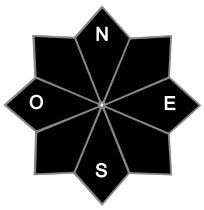

Au-dessus de 1800m indice de risque marqué, plus bas indice limité.

Départs spontanés : Acitvité en baisse, quelques départs possibles en pentes

Déclenchements provoqués : Risque accidentel encore localement marqué vers les hautes crêtes et sommets.

Indices de risque : 5 très fort - 4 fort - 3 marqué - 2 limité - 1 faible -- En noir : les pentes les plus dangereuses

Stabilité du manteau neigeux

Situation avalancheuse typique : neige ventée neige fraîche

Départs spontanés :
Activité en nette baisse pour samedi. Néanmoins lors de brèves éclaircies on s'attend à des avalanches de surface en pentes "réchauffées", près des rochers...
Noter qu'en pentes herbeuses raides (sous 1600 voire 1800m), la neige est assez humide en profondeur, on s'attend à quelques avalanches de fond avec glissement possible jusqu'au terrain.

Déclenchements provoqués : Vendredi, encore un risque accidentel de plaques, notamment à proximité des crêtes et sommets, parfois en pieds de barres.
Un seul skieur peut parfois déclencher une plaque assez conséquente. (Sous couche plus poudreuse représentant une couche fragile temporaire)... A modeste altitude, en neige plus humide, plutôt un risque de coulée ponctuelle sous les skis...

Qualité de la neige

Qualification de l'enneigement : L'enneigement s'est récemment dégradé aux basses altitudes, sous les sapins mais il est bon pour la saison dès la moyenne montagne et dans les combes sommitales... Crêtes parfois dégarnies/ congères et corniches...
Limites skiables : Vers 1100/1300 m, sur les pistes forestières/clairières...

Qualité de la neige samedi : Fine couche de neige fraiche au matin dès 1200/1300m. A basse altitude, regel au matin, plaques de glace... dès la moyenne montagne neige poudreuse, plus conséquente au dessus de 1500/1700m : 40/60 cm environ. Souvent ventée vers les hautes crêtes et sommets/ durcie, sculptée parfois. Lors de timides éclaircies, neige s'humidifiant au soleil, plutôt sous 1500/1800m...

Aperçu météo pour le samedi 14 février

	nuit	matin	après-midi	soir

Journée plutot nuageuse avec de faibles averses de neige et un vent de Nord qui se renforce.

Pluie-Neige	1 100 m	1 100 m	1 000 m	400 m
Iso 0 °C	1 700 m	1 500 m	1 400 m	800 m
Vent 1500 m	← 5 km/h	↘ 10 km/h	↓ 20 km/h	↘ 20 km/h
Vent 2000 m	↙ 15 km/h	↙ 25 km/h	↻ 45 km/h	↓ 45 km/h

Épaisseur de neige hors-piste

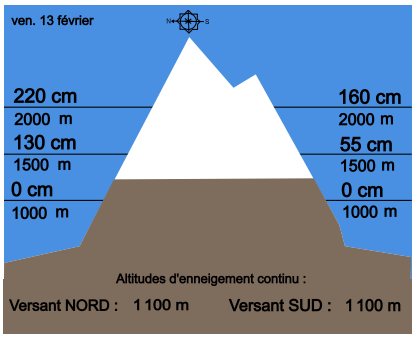

Précipitations à 1800 m

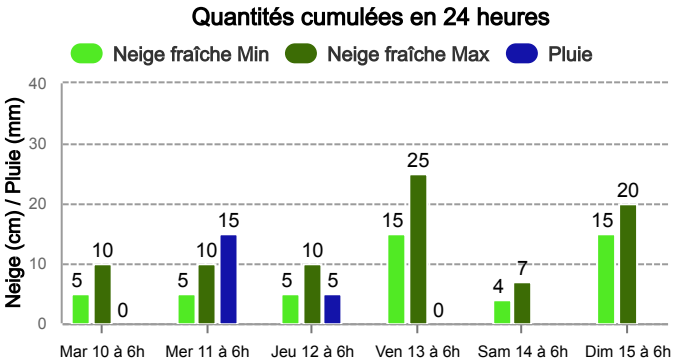

Tendance du dimanche 15 février

3 **Indice de risque marqué**

Tendance à la stabilisation avec un temps plus calme à venir.

Pour consulter la vigilance en cours, veuillez vous rendre sur le site https://vigilance.meteofrance.fr/fr

Météo-France - 73 avenue de Paris, 94165 Saint-Mandé cedex - Contact : contact@meteo.fr

Rédigé par Météo-France avec la contribution des observateurs du réseau nivo-météorologiques. Partenariat : ANMSM (Maires de Stations de Montagne), DSF (Domaines Skiables de France), ADSP (Directeurs de Pistes et de la Sécurité des Stations de Sports d'Hiver) et autres acteurs de la montagne.

Bulletin neige & avalanches par téléphone au 0 892 68 10 20 Service 0,35 € / min + prix appel

Bulletin d'estimation du risque d'avalanche

(valable en dehors des pistes balisées et ouvertes)

MASSIF : Vercors

Rédigé le vendredi 13 février 2026 à 16h

Conditions nivo-météo des 7 derniers jours

	sam. 07/02				dim. 08/02				lun. 09/02				mar. 10/02				mer. 11/02				jeu. 12/02				ven. 13/02			
	03h	09h	15h	21h	03h	09h	15h	21h	03h	09h	15h	21h	03h	09h	15h	21h	03h	09h	15h	21h	03h	09h	15h	21h	03h	09h	15h	21h
Météo																												
Vent (km/h)	15	15	15	10	25	20	25	20	10	25	25	35	50	40	50	70	80	65	55	100	85	70	70	55	50	20	35	35
à 2000m																												
Vent (km/h)	10	10	15	10	15	20	20	15	10	15	25	25	40	30	35	50	60	30	35	85	70	50	45	15	15	10	10	5
à 1500m																												

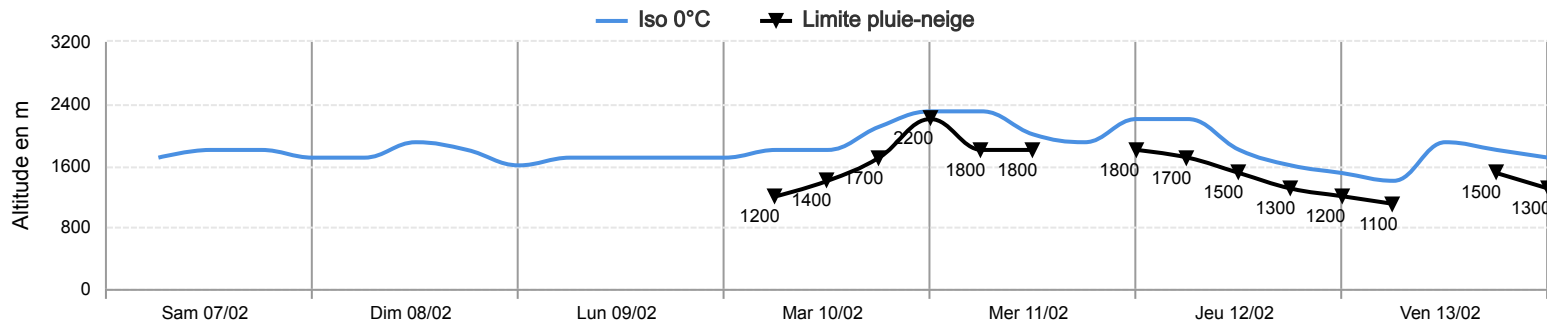

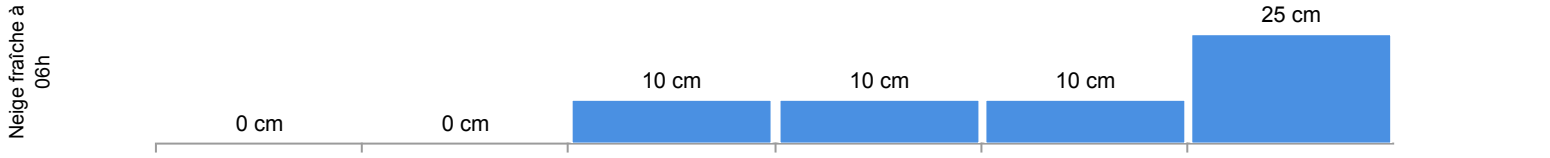

Risque d'avalanche	sam. 07/02	dim. 08/02	lun. 09/02	mar. 10/02	mer. 11/02	jeu. 12/02	ven. 13/02
	3	2	2	3	3	3	3

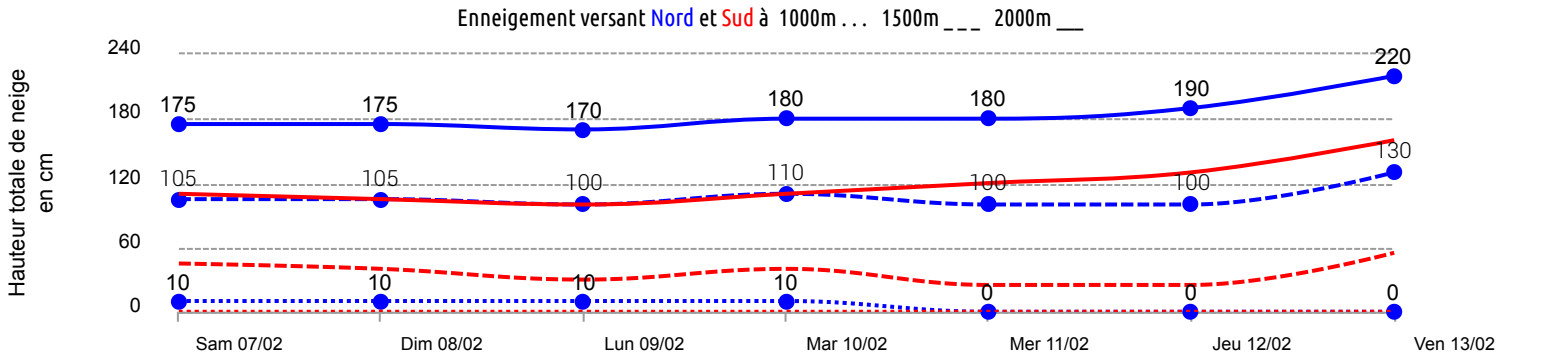

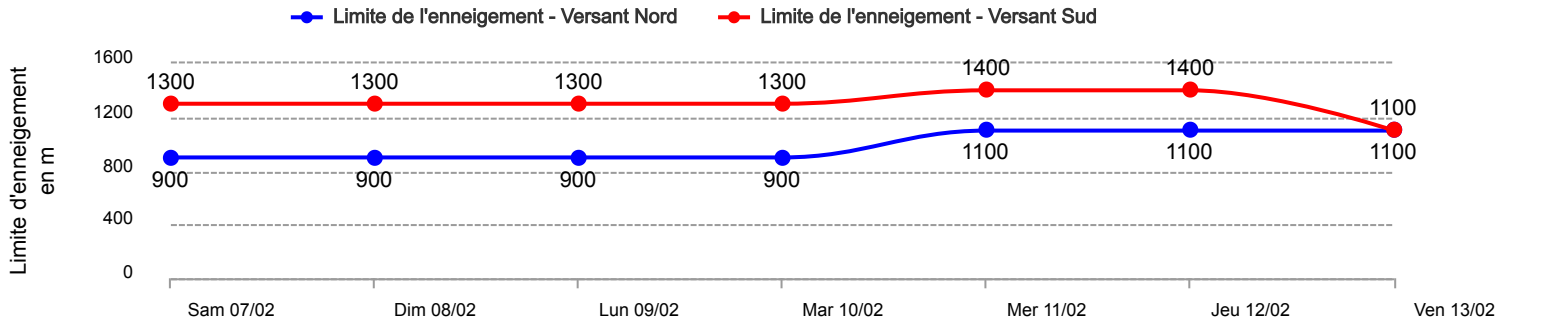

Pour consulter la vigilance en cours, veuillez vous rendre sur le site https://vigilance.meteofrance.fr/fr

Météo-France - 73 avenue de Paris, 94165 Saint-Mandé cedex - Contact : contact@meteo.fr

Rédigé par Météo-France avec la contribution des observateurs du réseau nivo-météorologiques. Partenariat : ANMSM (Maires de Stations de Montagne), DSF (Domaines Skiables de France), ADSP (Directeurs de Pistes et de la Sécurité des Stations de Sports d'Hiver) et autres acteurs de la montagne.

Bulletin neige & avalanches par téléphone au 0 892 68 10 20 Service 0,35 € / min + prix appel