Bulletin d'estimation du risque d'avalanche

(valable en dehors des pistes balisées et ouvertes)

MASSIF : Beaufortain

Rédigé le vendredi 13 février 2026 à 17h

Estimation des risques pour le : SAMEDI 14 FÉVRIER

NOMBREUSES PLAQUES ENTRETENUES PAR L'ÉPISODE DE FOEHN : FORT RISQUE ACCIDENTEL.

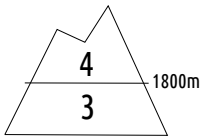

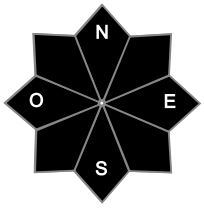

Au-dessus de 1800m indice de risque fort, plus bas indice marqué.

Départs spontanés : quelques départs linéaires dans les secteurs foehnés.

Déclenchements provoqués : nombreuses plaques faciles à déclencher, en tous versants.

Indices de risque : 5 très fort - 4 fort - 3 marqué - 2 limité - 1 faible -- En noir : les pentes les plus dangereuses

Stabilité du manteau neigeux

Situation avalancheuse typique : neige ventée couche fragile persistante

Déclenchements provoqués : nombreuses plaques friables dans la neige récente ventée. Plaques épaisses et fortement réactives au passage d'un seul skieur. Déclenchements possibles en tous versants, essentiellement au-dessus de 1800 m. Avalanches de taille moyenne (2).
Facteur aggravant : possible déclenchement en cascade si un premier départ sollicite une couche fragile persistante enfouie plus profondément. Ces avalanches peuvent alors mobiliser de grands volumes (taille 3, grande avalanche possible).

Départs spontanés : dans les secteurs soumis au foehn dans la nuit de vendredi à samedi, des départs linéaires (plaques) sont possibles dans la neige récente. Quelques avalanches d'ampleur généralement limitée, mais toujours potentiellement des grandes tailles en cas de départ en cascade. Ces avalanches s'arrêtent le matin, une fois le foehn tombé.

Qualité de la neige

Enneigement : le bilan des chutes de neige est largement positif dès 1500 m d'altitude, les hauteurs sont à nouveau excédentaires au-delà. Il est tombé en moyenne 100/130 cm de neige au-dessus de 2000 m depuis mardi.

Limite skiable : en nord, skiable sur l'herbe ou sur pistes forestières dès 1000 m, dans les sous-bois dès 1200 m. En sud, skiable dès 1200 m en prairies pas trop raides, 1600 m en Sud raide.

Qualité de la neige : très gros cumuls de neige ventée en haute montagne, avec plus d'1 m dans les zones d'accumulations tandis que les croupes sont moins chargées.
La neige s'est humidifiée vendredi en sud/sud-est jusque vers 2000/2200 m, ces orientation pourront être croutées et désagréables à skier ce samedi.

Aperçu météo pour le samedi 14 février

	nuit	matin	après-midi	soir
Pluie-Neige			1 200 m	700 m
Iso 0 °C	1 600 m	1 600 m	1 600 m	1 200 m
Vent 2000 m	30 km/h	10 km/h	25 km/h	25 km/h
Vent 3000 m	35 km/h	15 km/h	40 km/h	40 km/h

Ciel couvert. A partir de l'après-midi, le vent tourne au nord et de faibles chutes de neige se déclenchent, parfois sous forme d'averses.

Épaisseur de neige hors-piste

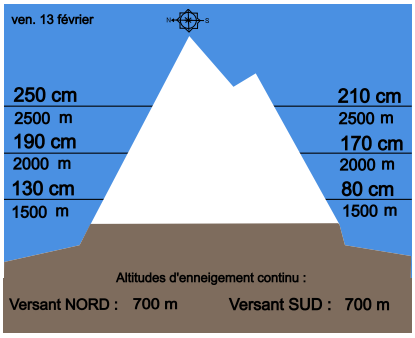

Précipitations à 1800 m

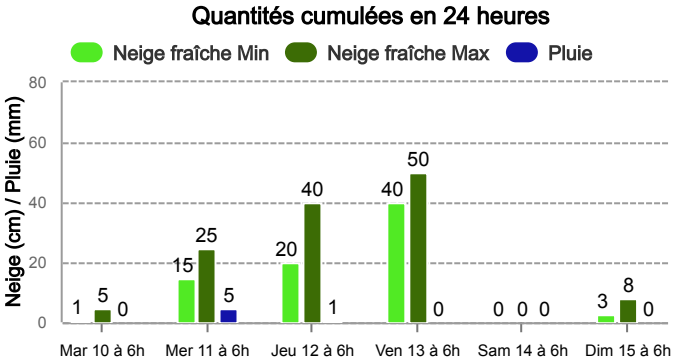

Tendance du dimanche 15 février

Indice de risque marqué

Temps calme et couvert avant l'arrivée d'une nouvelle perturbation en soirée. Risque marqué avec encore des plaques ventées dans la neige récente.

Pour consulter la vigilance en cours, veuillez vous rendre sur le site https://vigilance.meteofrance.fr/fr

Météo-France - 73 avenue de Paris, 94165 Saint-Mandé cedex - Contact : contact@meteo.fr

Rédigé par Météo-France avec la contribution des observateurs du réseau nivo-météorologiques. Partenariat : ANMSM (Maires de Stations de Montagne), DSF (Domaines Skiables de France), ADSP (Directeurs de Pistes et de la Sécurité des Stations de Sports d'Hiver) et autres acteurs de la montagne.

Bulletin neige & avalanches par téléphone au 0 892 68 10 20 Service 0,35 € / min + prix appel

RÉPUBLIQUE FRANÇAISE
Liberté Égalité Fraternité

METEO FRANCE
À VOS CÔTÉS, DANS UN CLIMAT QUI CHANGE

Bulletin d'estimation du risque d'avalanche

(valable en dehors des pistes balisées et ouvertes)

MASSIF : Beaufortain

Rédigé le vendredi 13 février 2026 à 17h

Conditions nivo-météo des 7 derniers jours

	sam. 07/02				dim. 08/02				lun. 09/02				mar. 10/02				mer. 11/02				jeu. 12/02				ven. 13/02			
	03h	09h	15h	21h	03h	09h	15h	21h	03h	09h	15h	21h	03h	09h	15h	21h	03h	09h	15h	21h	03h	09h	15h	21h	03h	09h	15h	21h
Météo																												
Vent (km/h)	15	10	5	5	15	20	20	20	20	15	20	25	30	35	45	55	70	55	45	75	90	90	85	70	50	40	40	50
à 3000m																												
Vent (km/h)	5	5	0	0	10	15	10	10	10	10	10	10	15	20	25	35	50	40	25	50	70	75	65	40	25	15	30	40
à 2000m																												

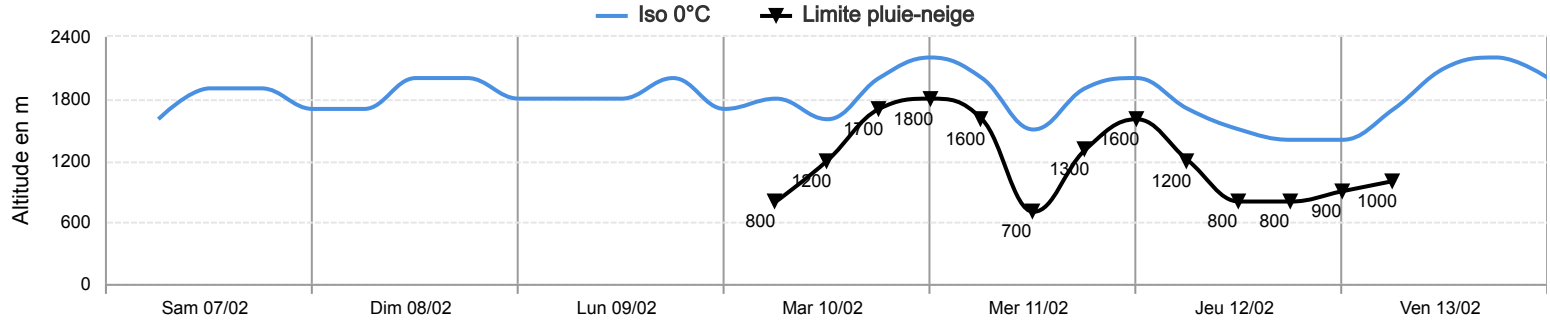

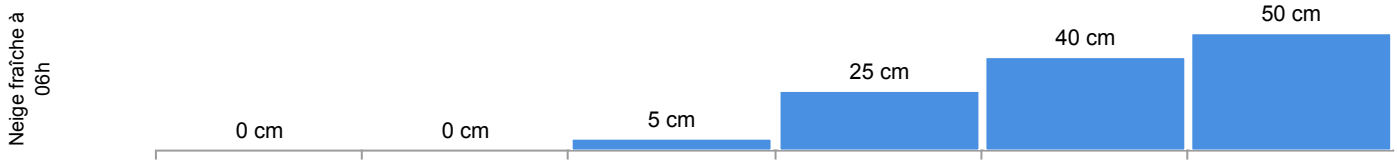

Risque d'avalanche	sam. 07/02	dim. 08/02	lun. 09/02	mar. 10/02	mer. 11/02	jeu. 12/02	ven. 13/02
	3	2	2	3	4	5	4

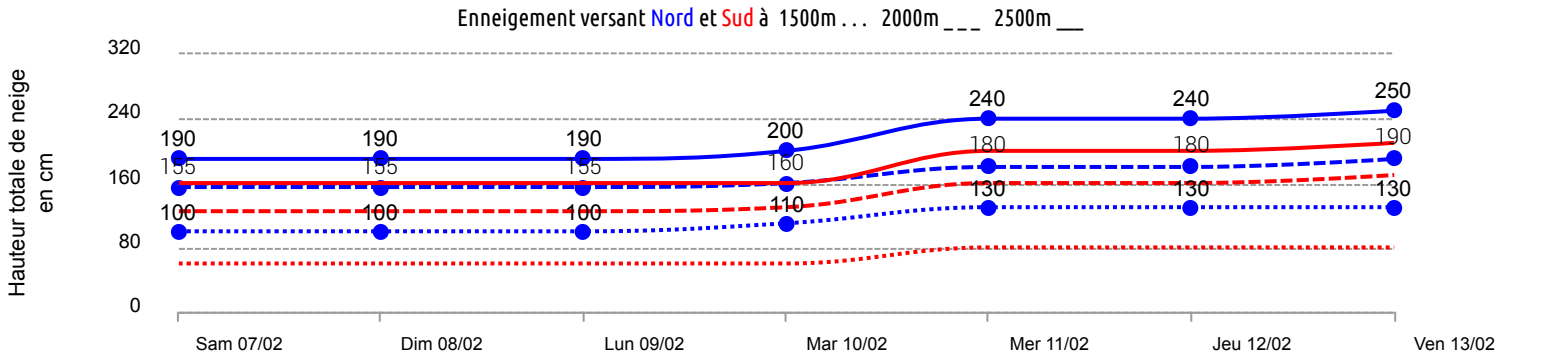

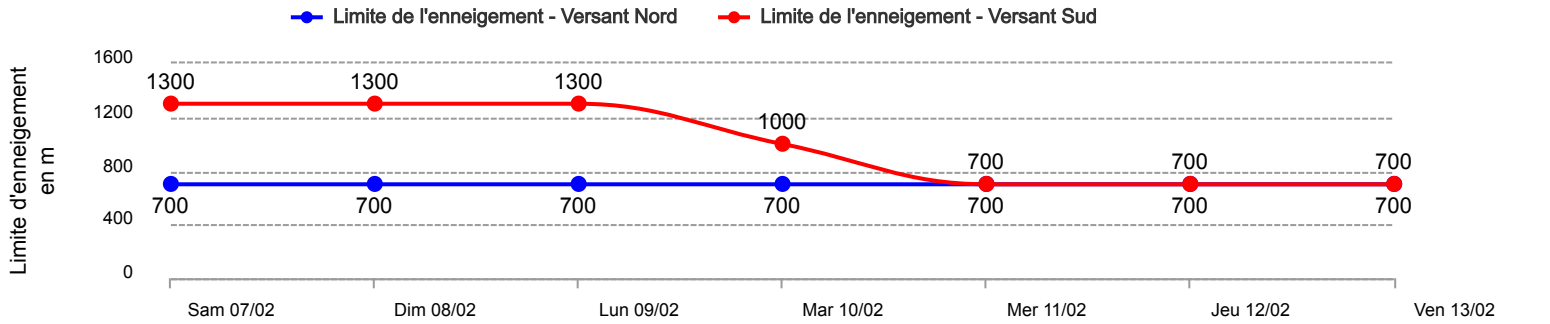

Pour consulter la vigilance en cours, veuillez vous rendre sur le site https://vigilance.meteofrance.fr/fr

Météo-France - 73 avenue de Paris, 94165 Saint-Mandé cedex - Contact : contact@meteo.fr

Rédigé par Météo-France avec la contribution des observateurs du réseau nivo-météorologiques. Partenariat : ANMSM (Maires de Stations de Montagne), DSF (Domaines Skiables de France), ADSP (Directeurs de Pistes et de la Sécurité des Stations de Sports d'Hiver) et autres acteurs de la montagne.

Bulletin neige & avalanches par téléphone au
0 892 68 10 20
Service 0,35 € / min + prix appel