Bulletin d'estimation du risque d'avalanche
(valable en dehors des pistes balisées et ouvertes)

MASSIF : Haut-Var Haut-Verdon

Rédigé le vendredi 13 février 2026 à 17h

Estimation des risques pour le : SAMEDI 14 FÉVRIER

NOMBREUSES INSTABILITÉS DANS LA NEIGE RÉCENTE, PARFOIS VOLUMINEUSES.

3

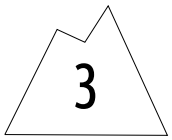

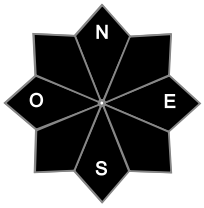

Indice de risque marqué.

Départs spontanés : départs dans la neige fraiche ventée, rarement grand.

Déclenchements provoqués : nombreuses instabilités dans la neige fraiche ventée, parfois volumineuses.

Indices de risque : 5 très fort - 4 fort - 3 marqué - 2 limité - 1 faible -- En noir : les pentes les plus dangereuses

Stabilité du manteau neigeux

Situation avalancheuse typique : neige fraîche neige ventée

Déclenchements provoqués : nombreuses plaques en place dans la neige récente ventée, possibles en toutes orientations. Plaques souvent en neige durcie par le vent, mais pouvant être masqués par la couche de neige fraîche en surface. Elles sont déclenchables par un seul skieur, et généralement de taille petite à moyenne (taille 1 à 2), parfois grande (taille 3) dans les zones de forte accumulation par le vent. En orientations ouest, nord et est d'altitude supérieure à 2000 m environ sur le Haut-Verdon, on retrouve plaques plus volumineuses reposantes sur des couches fragiles persistantes enfouies en profondeur, difficile à solliciter par un skieur isolé, mais pouvant l'être par un premier départ de surface. Avalanche de grande taille (taille 3) voir très grande taille non exclue (taille 4) sur le Haut-Verdon, avec des cassures larges et épaisses.

Départs spontanés : départs ponctuels pendant les chutes de neige et départs linéaires avec le transport de neige fraiche par le vent. Avalanche de taille petite à moyenne (taille 1 à 2), parfois grande (taille 3) dans les zones de forte accumulation par le vent, ou en cas de déstabilisations d'une plaque plus ancienne.

Qualité de la neige

Enneigement abondant, très excédentaire pour un mois de février.
Données observées vers 2000 m en fond de vallon : 150 à 180 cm.

Enneigement skiable dès 1200/1400 m sur terrains favorables.

État de la neige en surface : On retrouve en surface 10 à 15 cm de neige fraîche, fortement travaillée/durcie par le vent. Elle repose sur une sous-couche généralement dure ou regelée, mais parfois en poudreuse dense en ubacs abrités du vent. Neige s'humidifiant en journée en dessous de 1800/2200 selon les orientations.

Aperçu météo pour le samedi 14 février

	nuit	matin	après-midi	soir
	Temps voilé à couvert, quelques éclaircies en fin de journée.			
Pluie-Neige	1 000 m			
Iso 0 °C	1 600 m	1 900 m	2 100 m	2 000 m
Vent 2000 m	35 km/h	45 km/h	40 km/h	35 km/h
Vent 3000 m	70 km/h	70 km/h	60 km/h	40 km/h

Épaisseur de neige hors-piste

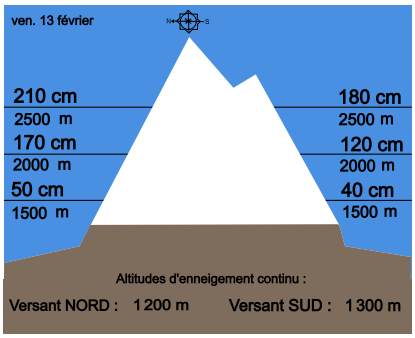

Précipitations à 1800 m

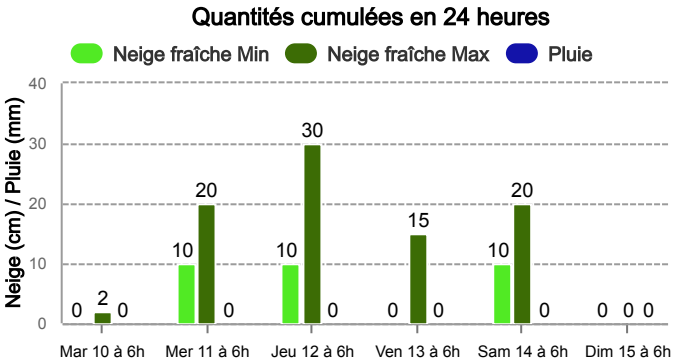

Tendance du dimanche 15 février

3

Indice de risque marqué

Risque restant marqué avec des plaques toujours en place dans la neige récente, se stabilisant lentement.

Pour consulter la vigilance en cours, veuillez vous rendre sur le site https://vigilance.meteofrance.fr/fr

Météo-France - 73 avenue de Paris, 94165 Saint-Mandé cedex - Contact : contact@meteo.fr

Rédigé par Météo-France avec la contribution des observateurs du réseau nivo-météorologiques. Partenariat : ANMSM (Maires de Stations de Montagne), DSF (Domaines Skiables de France), ADSP (Directeurs de Pistes et de la Sécurité des Stations de Sports d'Hiver) et autres acteurs de la montagne.

Bulletin neige & avalanches par téléphone au 0 892 68 10 20 Service 0,35 € / min + prix appel

Bulletin d'estimation du risque d'avalanche

(valable en dehors des pistes balisées et ouvertes)

MASSIF : Haut-Var Haut-Verdon

Rédigé le vendredi 13 février 2026 à 17h

Conditions nivo-météo des 7 derniers jours

	sam. 07/02				dim. 08/02				lun. 09/02				mar. 10/02				mer. 11/02				jeu. 12/02				ven. 13/02			
	03h	09h	15h	21h	03h	09h	15h	21h	03h	09h	15h	21h	03h	09h	15h	21h	03h	09h	15h	21h	03h	09h	15h	21h	03h	09h	15h	21h
Météo																												
Vent (km/h)	35	15	15	10	15	30	30	25	15	15	20	30	30	35	50	65	100	110	60	70	80	100	140	130	90	30	40	55
à 3000m																												
Vent (km/h)	20	10	10	10	10	15	20	20	10	5	15	10	10	15	20	20	20	20	30	40	80	90	120	115	60	15	20	25
à 2000m																												

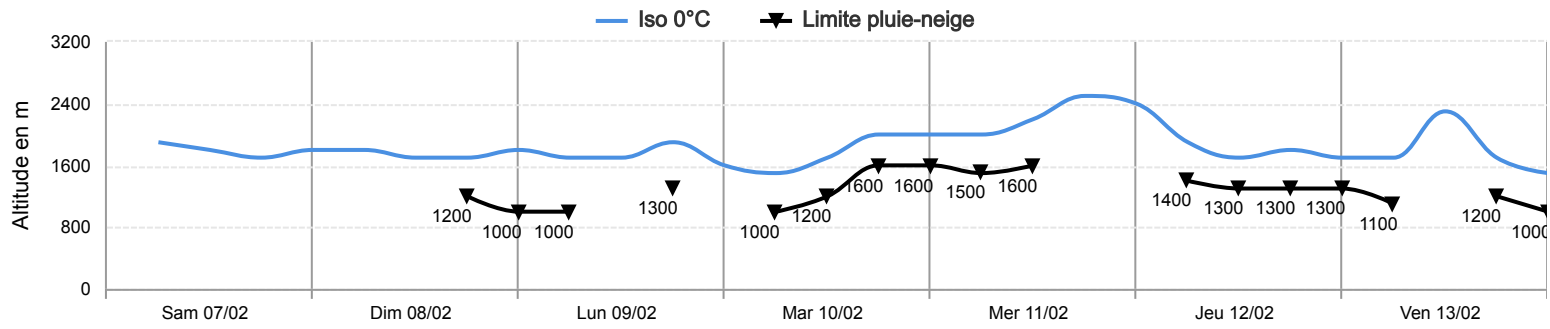

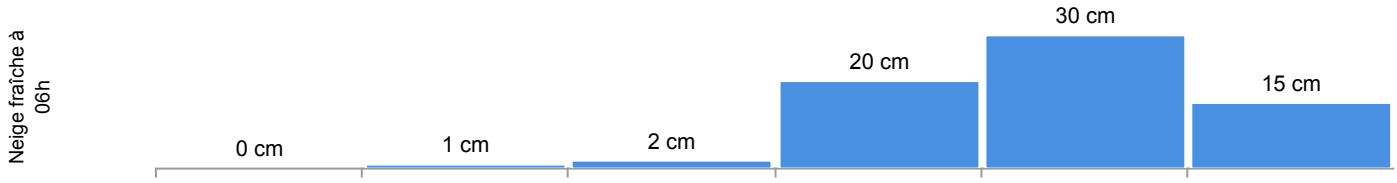

Risque d'avalanche	sam. 07/02	dim. 08/02	lun. 09/02	mar. 10/02	mer. 11/02	jeu. 12/02	ven. 13/02
	3	3	3	3	3	4	4

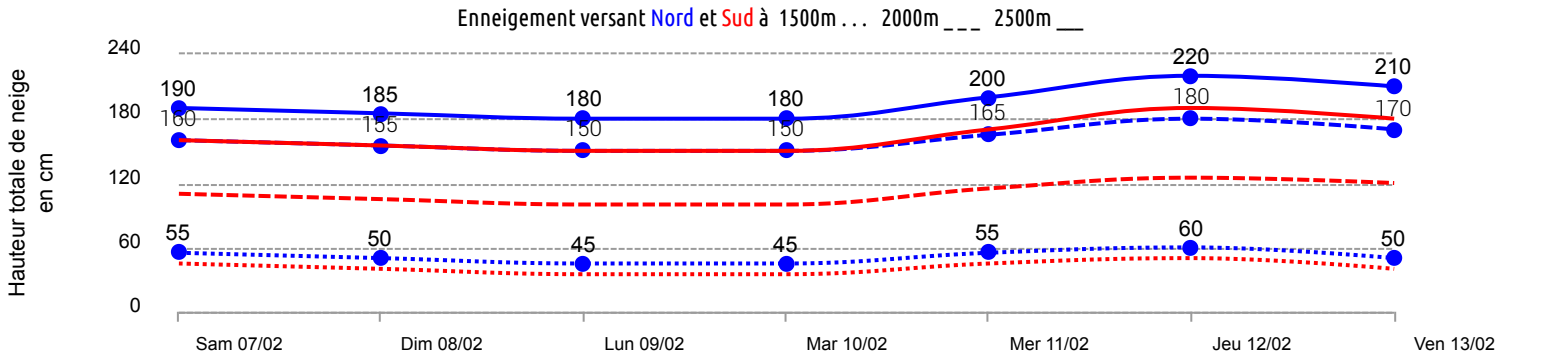

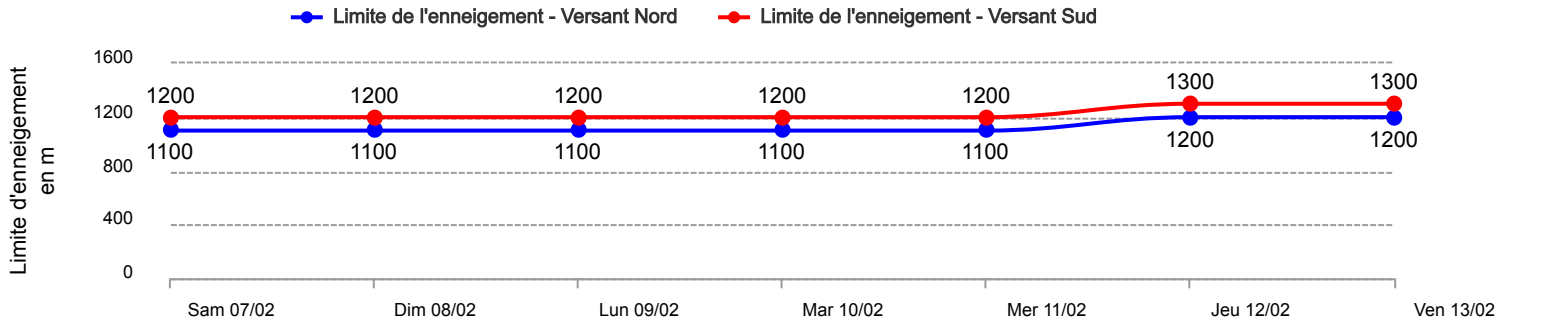

Pour consulter la vigilance en cours, veuillez vous rendre sur le site https://vigilance.meteofrance.fr/fr

Météo-France - 73 avenue de Paris, 94165 Saint-Mandé cedex - Contact : contact@meteo.fr

Bulletin neige & avalanches par téléphone au 0 892 68 10 20 Service 0,35 € / min + prix appel

Rédigé par Météo-France avec la contribution des observateurs du réseau nivo-météorologiques. Partenariat : ANMSM (Maires de Stations de Montagne), DSF (Domaines Skiables de France), ADSP (Directeurs de Pistes et de la Sécurité des Stations de Sports d'Hiver) et autres acteurs de la montagne.