Bulletin d'estimation du risque d'avalanche

(valable en dehors des pistes balisées et ouvertes)

MASSIF : Haute-Tarentaise

Rédigé le vendredi 13 février 2026 à 17h

Estimation des risques pour le : SAMEDI 14 FÉVRIER

DU FOEHN CETTE NUIT SUR UN MANTEAU ENCORE TRÈS INSTABLE : RISQUE ACCIDENTEL MAXIMAL.

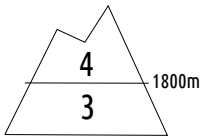

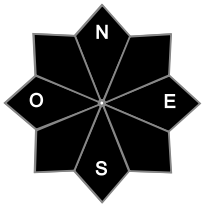

Au-dessus de 1800m indice de risque fort, plus bas indice marqué.

Départs spontanés : quelques départs linéaires sous le foehn la nuit, d'ampleur généralement limitée.

Déclenchements provoqués : le risque reste maximal avec de nombreuses plaques très réactives dès 1800 m.

Indices de risque : 5 très fort - 4 fort - 3 marqué - 2 limité - 1 faible -- En noir : les pentes les plus dangereuses

Stabilité du manteau neigeux

Situation avalancheuse typique : neige ventée couche fragile persistante

Déclenchements provoqués : plaques **nombreuses** et **fortement réactives**, déclenchables localement comme **à distance**. Risque généralisé dans **tous les versants, dès 1800 m d'altitude**. D'une part, des plaques friables sont en place dans la neige récente ventée par le foehn, qui souffle notamment vendredi soir (vallons frontaliers et secteur du Pisaillas particulièrement concernés). D'autre part, **la couche fragile enfouie (grains anguleux)** est encore sollicitable, donnant des **cassures parfois très épaisses pouvant largement dépasser le mètre**. Dans tous les cas, les plaques sont en place **même loin des crêtes**, les **écoulements** vont **vite** et **loin**, et une première avalanche en neige ventée pourra facilement solliciter en cascade la couche fragile enfouie, engendrant alors une **taille 3 (grande avalanche)**.

Départs spontanés : quelques départs linéaires possibles dans la nuit sous le foehn, plutôt d'ampleur limitée mais **un départ linéaire d'ampleur (taille 3, grande avalanche) reste non-exclu**. Dès l'aube, avec l'arrêt du vent, la probabilité d'un départ spontané devient faible.

Qualité de la neige

Enneigement : le bilan des chutes de neige est largement positif dès 1500 m d'altitude, les hauteurs sont à nouveau excédentaires au-delà. Il est tombé en moyenne 80/100 cm de neige au-dessus de 2000 m, sur les dernières 48 h.

Limite skiable : en nord, skiable sur l'herbe ou sur pistes forestières dès 1000 m, dans les sous-bois dès 1200 m. En sud, skiable dès 1200 m en prairies pas trop raides, 1600 m en Sud raide.

Qualité de la neige : très gros cumuls de neige ventée en haute montagne, avec plus d'1 m dans les zones d'accumulations tandis que les croupes sont moins chargées.
La neige s'est humidifiée vendredi en sud/sud-est jusque vers 2000/2200 m, ces orientation pourront être croutées et désagréables à skier ce samedi.

Aperçu météo pour le samedi 14 février

	nuit	matin	après-midi	soir

Ciel couvert. Rares précipitations frontalières jusqu'au matin, puis bascule en flux de nord : quelques averses possibles partout.

	nuit	matin	après-midi	soir
Pluie-Neige	1 200 m		1 200 m	900 m
Iso 0 °C	1 600 m	1 600 m	1 600 m	1 200 m
Vent 2500 m	← 30 km/h	↓ 10 km/h	↘ 10 km/h	↘ 25 km/h
Vent 3500 m	↖ 40 km/h	← 15 km/h	↓ 15 km/h	↘ 30 km/h

Épaisseur de neige hors-piste

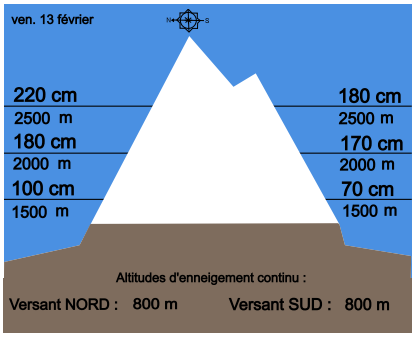

Précipitations à 1800 m

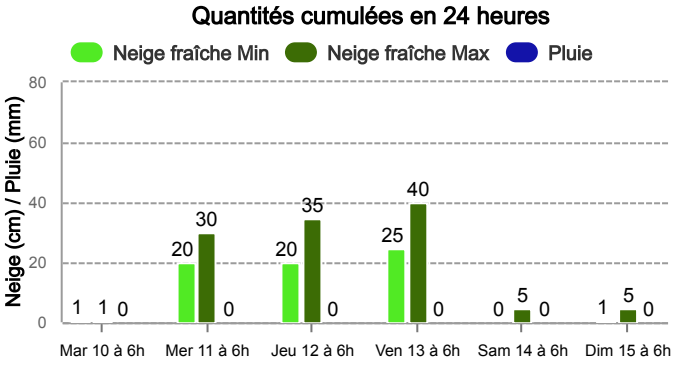

Tendance du dimanche 15 février

Indice de risque marqué

Temps calme et couvert avant l'arrivée d'une nouvelle perturbation en soirée. Risque marqué avec encore des plaques ventées dans la neige récente.

Pour consulter la vigilance en cours, veuillez vous rendre sur le site https://vigilance.meteofrance.fr/fr

Météo-France - 73 avenue de Paris, 94165 Saint-Mandé cedex - Contact : contact@meteo.fr

Rédigé par Météo-France avec la contribution des observateurs du réseau nivo-météorologiques. Partenariat : ANMSM (Maires de Stations de Montagne), DSF (Domaines Skiables de France), ADSP (Directeurs de Pistes et de la Sécurité des Stations de Sports d'Hiver) et autres acteurs de la montagne.

Bulletin neige & avalanches par téléphone au **0 892 68 10 20** Service 0,35 € / min + prix appel

Bulletin d'estimation du risque d'avalanche

(valable en dehors des pistes balisées et ouvertes)

MASSIF : Haute-Tarentaise

Rédigé le vendredi 13 Février 2026 à 17h

Conditions nivo-météo des 7 derniers jours

	sam. 07/02				dim. 08/02				lun. 09/02				mar. 10/02				mer. 11/02				jeu. 12/02				ven. 13/02			
	03h	09h	15h	21h	03h	09h	15h	21h	03h	09h	15h	21h	03h	09h	15h	21h	03h	09h	15h	21h	03h	09h	15h	21h	03h	09h	15h	21h
Météo																												
Vent (km/h)	15	15	15	15	20	30	30	25	20	15	20	25	30	40	55	60	60	55	45	50	70	80	75	65	55	30	40	50
à 3500m																												
Vent (km/h)	5	5	5	5	10	25	25	20	10	10	10	10	20	30	45	50	50	40	35	40	50	65	65	55	35	20	30	40
à 2500m																												

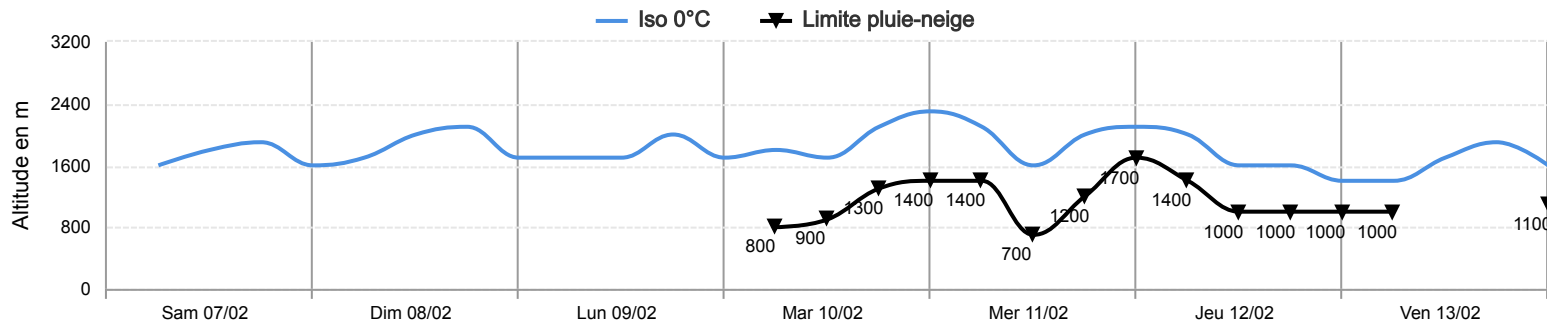

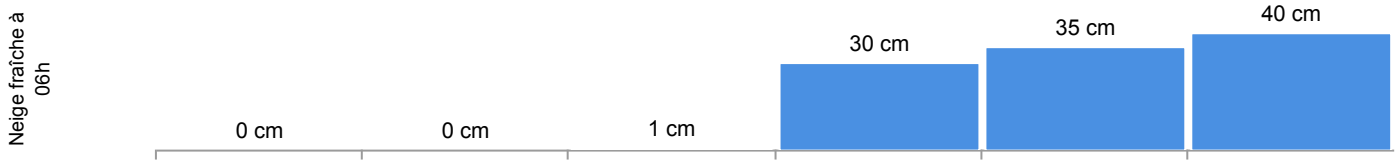

Risque d'avalanche	sam. 07/02	dim. 08/02	lun. 09/02	mar. 10/02	mer. 11/02	jeu. 12/02	ven. 13/02
	3	3	3	3	4	5	4

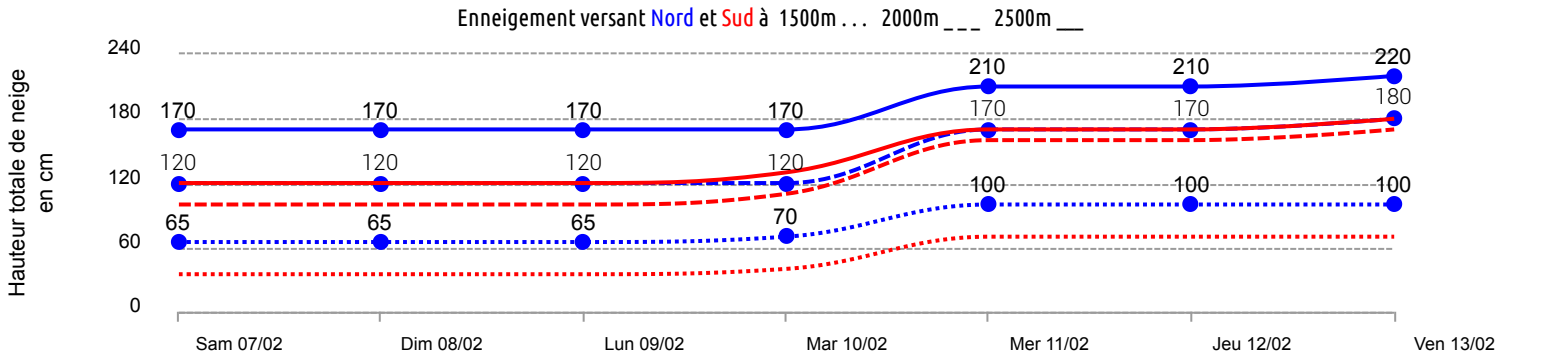

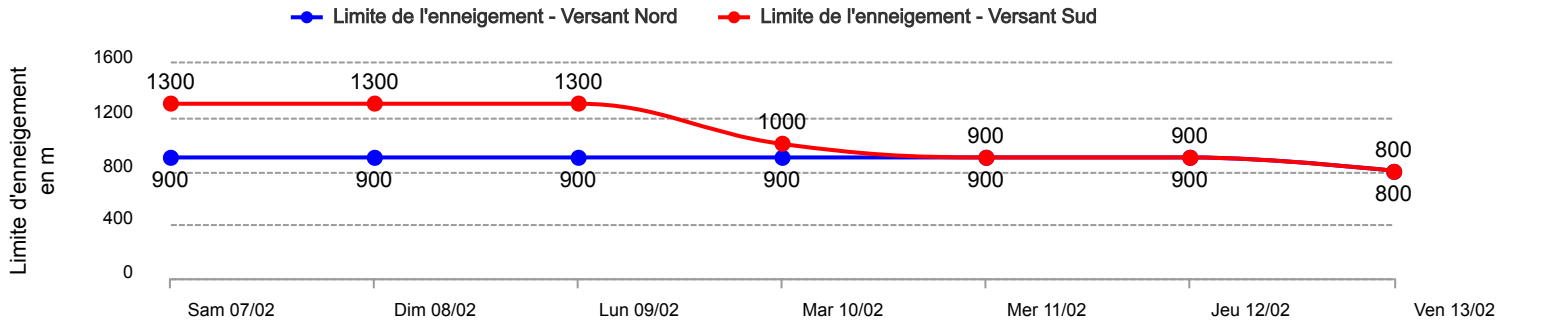

Pour consulter la vigilance en cours, veuillez vous rendre sur le site https://vigilance.meteofrance.fr/fr

Météo-France - 73 avenue de Paris, 94165 Saint-Mandé cedex - Contact : contact@meteo.fr

Bulletin neige & avalanches par téléphone au

0 892 68 10 20 Service 0,35 € / min + prix appel

Rédigé par Météo-France avec la contribution des observateurs du réseau nivo-météorologiques. Partenariat : ANMSM (Maires de Stations de Montagne), DSF (Domaines Skiables de France), ADSP (Directeurs de Pistes et de la Sécurité des Stations de Sports d'Hiver) et autres acteurs de la montagne.