# Bulletin d'estimation du risque d'avalanche

(valable en dehors des pistes balisées et ouvertes)

# MASSIF : Luchonnais

Rédigé le vendredi 13 février 2026 à 17h

## Estimation des risques pour le : SAMEDI 14 FÉVRIER

**NEIGE FRAÎCHE VENTEE**

3

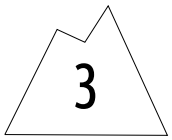


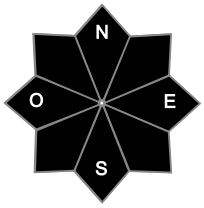


Neige fraîche

Indice de risque marqué.

**Départs spontanés :** En neige fraîche, nombreuses moyennes à rarement grandes.

**Déclenchements provoqués :** Plaques fragiles temporaires en neige ventée.

Indices de risque : 5 très fort - 4 fort - 3 marqué - 2 limité - 1 faible -- En noir : les pentes les plus dangereuses

## Stabilité du manteau neigeux

**Situation avalancheuse typique :** neige fraîche

**Déclenchements provoqués :**
De nombreuses plaques à vent se forment dès cette nuit avec des cumuls de 15 à 25 cm de neige en fin de nuit et tout autant en journée samedi vers 2400 m (cumuls de l'épisode 30 cm vers 1500 m, au lever dimanche matin, 35 à 50 cm vers 2400 m). Ces structures fragiles temporaires seront facilement déclenchables en secteurs déventés, possiblement loin des cols et crêtes avec ce vent fort de nord-ouest à nord. Avalanches généralement de tailles 2 (moyenne) à parfois 3 (grandes) possibles samedi en journée dans les secteurs d'accumulation en SUD à EST déventés. Au vent, côté nord des pentes, plaques plus dures moins facilement sollicitables.

**Départs spontanés** : Dès cette nuit (de vendredi à samedi) des avalanches se déclenchent, plus nombreuses en fin de nuit, de taille 1 à 2, elles peuvent plus rarement atteindre le stade de grande avalanche (taille 3) en journée samedi dans les secteurs d'accumulation EST à large SUD. Départs ponctuels réguliers en neige fraîche en pentes raides, départs de plaques (linéaires) facilités par le vent fort.

**Autres : intensités neigeuses parfois fortes sur cet épisode.**

## Qualité de la neige

**Enneigement** : L'enneigement résiste ce vendredi, les crêtes, cols et sommets en expositions ouest sont souvent pelés, ou en glace. Le manteau gagne rapidement en épaisseur jusqu'à 1200 m pour atteindre 25 à 35 cm samedi soir vers 1500 m, des cumuls attendus de 40 à 60 cm envisageables derrière les crêtes (et souvent plus par effet d'accumulation) au-dessus de 2400 m.
**Limites skiables** : Manteau neigeux skiable à partir de 1300 m samedi matin, sous-couche compacte à partir de 1500/1600 m.
**État de la neige** : Vendredi : le manteau neigeux est bien humidifié jusqu'en profondeur, avec un regel de quelques centimètres en surface, manteau en place sur lequel la neige fraîche vient se déposer avec une masse d'air qui se refroidit samedi.

## Aperçu météo pour le samedi 14 février

| | nuit | matin | après-midi | soir |
|---|---|---|---|---|
| | | | | |

Temps perturbé dès vendredi soir et tout samedi, bouché, souvent fortement neigeux dans un air qui se refroidit par vent fort de nord-ouest à nord.

| | | | | |
|---|---|---|---|---|
| **Pluie-Neige** | 1 300 m | 1 000 m | 1 000 m | 600 m |
| **Iso 0 °C** | 1 600 m | 1 300 m | 1 300 m | 900 m |
| **Vent 2000 m** | ↘ 60 km/h | ↓ 70 km/h | ↘ 70 km/h | ↓ 50 km/h |
| **Vent 3000 m** | ↘ 80 km/h | ↓ 100 km/h | ↓ 95 km/h | ↓ 85 km/h |

## Épaisseur de neige hors-piste

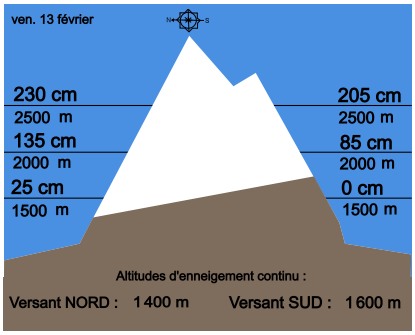


## Précipitations à 1800 m

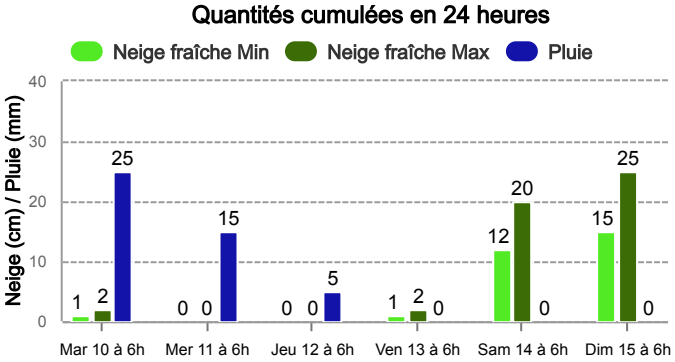


## Tendance du dimanche 15 février

3

**Indice de risque marqué**

Humidification de la neige récente en air plus doux et des pluies en soirée dimanche au-dessous de 1800 m en début d'épisode perturbé se poursuivant jusqu'à mardi matin.

Pour consulter la vigilance en cours, veuillez vous rendre sur le site https://vigilance.meteofrance.fr/fr

Météo-France - 73 avenue de Paris, 94165 Saint-Mandé cedex - Contact : contact@meteo.fr

Rédigé par Météo-France avec la contribution des observateurs du réseau nivo-météorologiques. Partenariat : ANMSM (Maires de Stations de Montagne), DSF (Domaines Skiables de France), ADSP (Directeurs de Pistes et de la Sécurité des Stations de Sports d'Hiver) et autres acteurs de la montagne.

Bulletin neige & avalanches par téléphone au

0 892 68 10 20 Service 0,35 € / min + prix appel

RÉPUBLIQUE FRANÇAISE
*Liberté Égalité Fraternité*

METEO FRANCE
À VOS CÔTÉS, DANS UN CLIMAT QUI CHANGE

# Bulletin d'estimation du risque d'avalanche

## (valable en dehors des pistes balisées et ouvertes)

# MASSIF : Luchonnais

Rédigé le vendredi 13 février 2026 à 17h

## Conditions nivo-météo des 7 derniers jours

| | sam. 07/02 | | | | dim. 08/02 | | | | lun. 09/02 | | | | mar. 10/02 | | | | mer. 11/02 | | | | jeu. 12/02 | | | | ven. 13/02 | | | |
|---|---|---|---|---|---|---|---|---|---|---|---|---|---|---|---|---|---|---|---|---|---|---|---|---|---|---|---|---|
| | 03h | 09h | 15h | 21h | 03h | 09h | 15h | 21h | 03h | 09h | 15h | 21h | 03h | 09h | 15h | 21h | 03h | 09h | 15h | 21h | 03h | 09h | 15h | 21h | 03h | 09h | 15h | 21h |
| Météo | | | | | | | | | | | | | | | | | | | | | | | | | | | | |
| Vent (km/h) | 40 | 40 | 40 | 50 | 40 | 35 | 50 | 40 | 50 | 50 | 55 | 80 | 75 | 90 | 100 | 100 | 90 | 110 | 110 | 120 | 120 | 120 | 90 | 70 | 85 | 75 | 75 | 110 |
| à 3000m | | | | | | | | | | | | | | | | | | | | | | | | | | | | |
| Vent (km/h) | 30 | 10 | 20 | 35 | 30 | 10 | 20 | 15 | 20 | 20 | 20 | 35 | 40 | 40 | 45 | 50 | 40 | 60 | 80 | 100 | 100 | 100 | 70 | 40 | 60 | 50 | 50 | 85 |
| à 2000m | | | | | | | | | | | | | | | | | | | | | | | | | | | | |

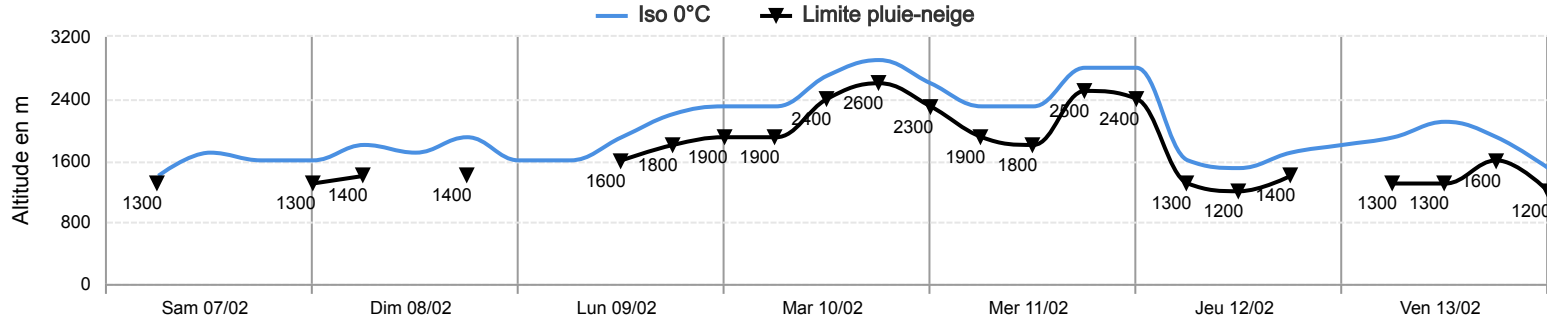


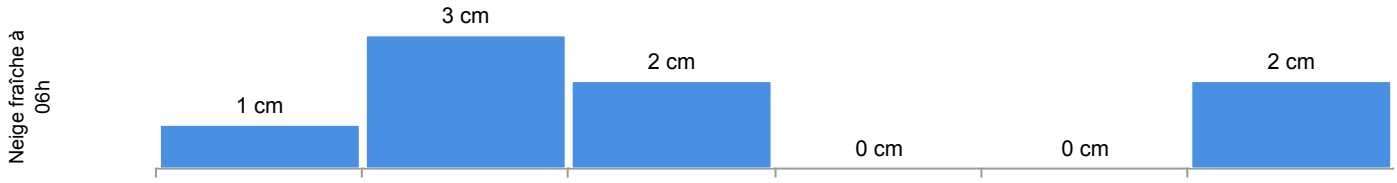


| Risque d'avalanche | sam. 07/02 | dim. 08/02 | lun. 09/02 | mar. 10/02 | mer. 11/02 | jeu. 12/02 | ven. 13/02 |
|---|---|---|---|---|---|---|---|
| | 2 | 2 | 2 | 3 | 3 | 3 | 2 |

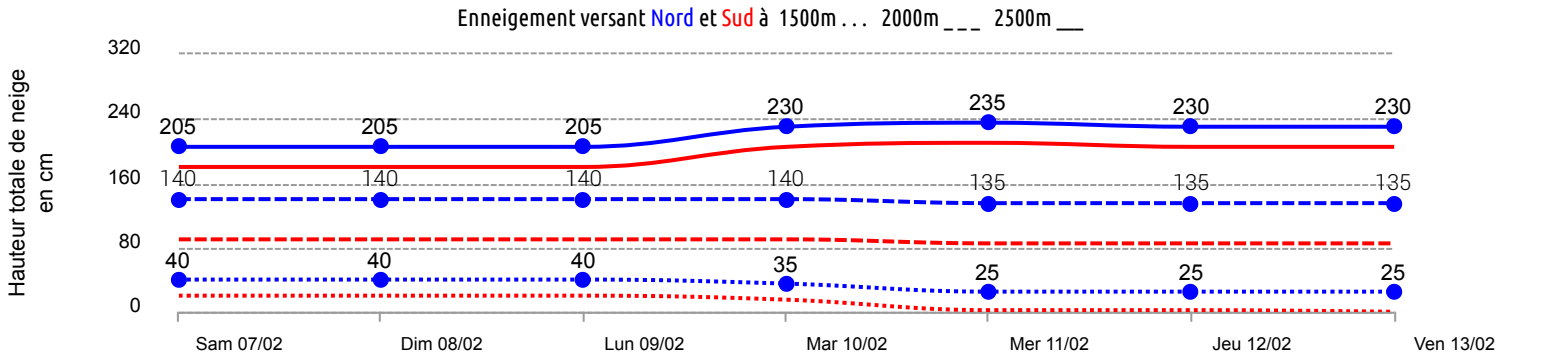


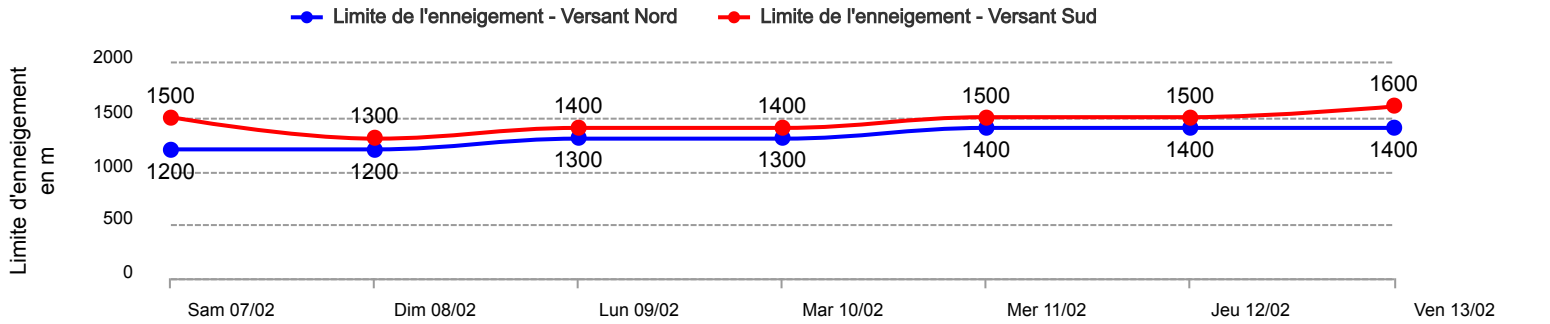


Pour consulter la vigilance en cours, veuillez vous rendre sur le site https://vigilance.meteofrance.fr/fr


Météo-France - 73 avenue de Paris, 94165 Saint-Mandé cedex - Contact : contact@meteo.fr



Rédigé par Météo-France avec la contribution des observateurs du réseau nivo-météorologiques. Partenariat : ANMSM (Maires de Stations de Montagne), DSF (Domaines Skiables de France), ADSP (Directeurs de Pistes et de la Sécurité des Stations de Sports d'Hiver) et autres acteurs de la montagne.



Bulletin neige & avalanches par téléphone au
0 892 68 10 20 Service 0,35 € / min + prix appel