RÉPUBLIQUE FRANÇAISE
Liberté Égalité Fraternité

METEO FRANCE
À VOS CÔTÉS, DANS UN CLIMAT QUI CHANGE

Bulletin d'estimation du risque d'avalanche
(valable en dehors des pistes balisées et ouvertes)

MASSIF : Queyras

Rédigé le vendredi 13 février 2026 à 17h

Estimation des risques pour le : SAMEDI 14 FÉVRIER

FORTE INSTABILITÉ PERSISTANTE - PLAQUES PARFOIS ÉPAISSES, FACILES À DÉCLENCHER

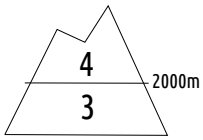

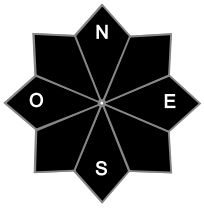

Au-dessus de 2000m indice de risque fort, plus bas indice marqué.

Départs spontanés : avalanches de plaque

Déclenchements provoqués : plaques dans de nombreuses pentes, faciles à déclencher, potentiellement épaisses

Indices de risque : 5 très fort - 4 fort - 3 marqué - 2 limité - 1 faible -- En noir : les pentes les plus dangereuses

Stabilité du manteau neigeux

Situation avalancheuse typique :

neige ventée

couche fragile persistante

Invitation à la prudence en montagne (émission d'un communiqué spécial avalanche)

Déclenchements provoqués : manteau neigeux restant instable. Surtout au-dessus de 1800 / 2000 m, dans de nombreuses orientations, plaques en place ou en formation avec les chutes de neige sur le Haut Guil et/ou le transport par le vent. Faciles à déclencher dans la neige fraiche/récente ventée. Elles engendrent des avalanches de taille moyenne à grande (taille 2 à 3), avec souvent de larges cassures. Dans les ubacs (pentes ouest, nord à est), des départs emportant la totalité du manteau neigeux en place restent possibles, en cas de rupture sur l'épaisse couche fragile persistante enfouie. Grandes avalanches (taille 3) attendues, une très grande (taille 4) non exclue dans un secteur à la topographie habituellement favorable.
Sous 1800/2000 m, quelques plaques aussi présentes, mais moins généralisées, car la neige récente s'est en partie humidifiée.

Départs spontanés : possibles avalanches de plaque de taille moyenne, voire grande. Activité surtout en lien avec le transport de la neige par le vent. Sur le Haut Guil, quelques départs ponctuels en pente raide, au fil des chutes de neige ventée. Taille petite, voire moyenne.

Qualité de la neige

L'enneigement est proche des normales dans les ubacs, voire excédentaire vers le Briançonnais, mais reste un peu déficitaire dans les adrets d'altitude, notamment dans le Haut Guil.
Hauteurs de neige observées : 161 cm en versant nord du col Izoard à 2300 m, 75 cm à la Nivôse du Col Agnel à 2630 m, 58 cm à Ristolas à 1670 m.

Limite d'enneigement skiable : dès 1000/1300 m en ubacs, plutôt 1400/1500 m en adrets.

État de la neige de surface : neige fraiche /récente souvent travaillée par le vent en altitude. Plus humide et lourde sous 1800/2000 m. Présence de corniches.

Aperçu météo pour le samedi 14 février

	nuit	matin	après-midi	soir

Neige fraiche (nuit + matinée) surtout sur le Haut Guil : 15/20 cm localement 30 cm, ailleurs 2/5 cm

Pluie-Neige	1 200 m	1 200 m		
Iso 0 °C	1 500 m	1 500 m	1 700 m	1 600 m
Vent 2000 m	↙ 30 km/h	↙ 30 km/h	↓ 10 km/h	↘ 10 km/h
Vent 3000 m	← 50 km/h	↙ 50 km/h	↓ 40 km/h	↓ 50 km/h

Épaisseur de neige hors-piste

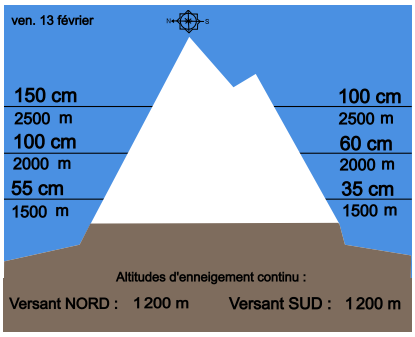

Précipitations à 1800 m

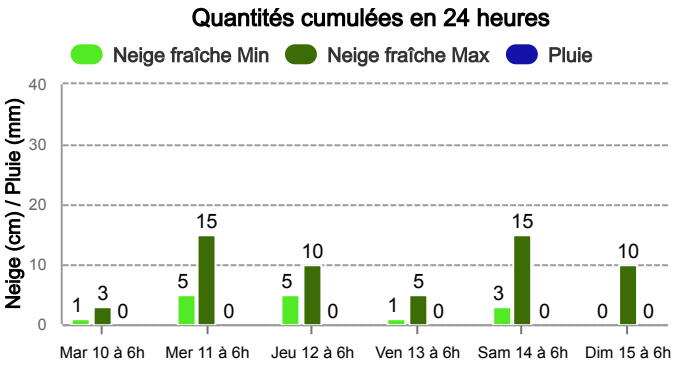

Tendance du dimanche 15 février

Indice de risque marqué

Risque marqué avec des plaques encore réactives, pouvant être volumineuses.

Pour consulter la vigilance en cours, veuillez vous rendre sur le site https://vigilance.meteofrance.fr/fr

Météo-France - 73 avenue de Paris, 94165 Saint-Mandé cedex - Contact : contact@meteo.fr

Rédigé par Météo-France avec la contribution des observateurs du réseau nivo-météorologiques. Partenariat : ANMSM (Maires de Stations de Montagne), DSF (Domaines Skiables de France), ADSP (Directeurs de Pistes et de la Sécurité des Stations de Sports d'Hiver) et autres acteurs de la montagne.

Bulletin neige & avalanches par téléphone au
0 892 68 10 20 Service 0,35 € / min + prix appel

RÉPUBLIQUE FRANÇAISE
Liberté Égalité Fraternité

METEO FRANCE
À VOS CÔTÉS, DANS UN CLIMAT QUI CHANGE

Bulletin d'estimation du risque d'avalanche
(valable en dehors des pistes balisées et ouvertes)

MASSIF : Queyras

Rédigé le vendredi 13 Février 2026 à 17h

Conditions nivo-météo des 7 derniers jours

	sam. 07/02				dim. 08/02				lun. 09/02				mar. 10/02				mer. 11/02				jeu. 12/02				ven. 13/02			
	03h	09h	15h	21h	03h	09h	15h	21h	03h	09h	15h	21h	03h	09h	15h	21h	03h	09h	15h	21h	03h	09h	15h	21h	03h	09h	15h	21h
Météo																												
Vent (km/h)	25	15	15	10	10	20	35	35	15	10	15	20	30	35	40	50	50	50	50	60	80	60	120	120	75	30	30	40
à 3000m																												
Vent (km/h)	10	10	15	5	5	15	30	30	10	10	15	10	10	20	25	25	25	25	30	30	30	30	50	50	35	15	20	30
à 2000m																												

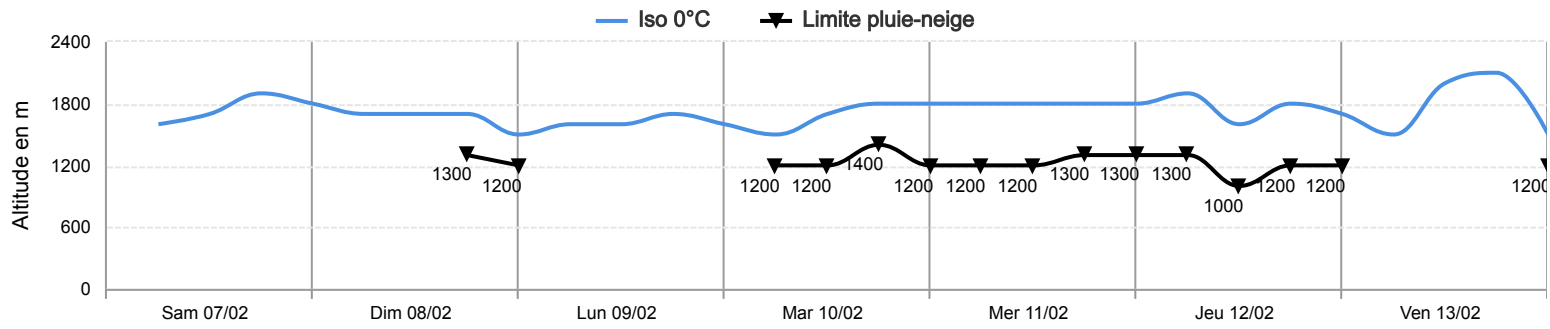

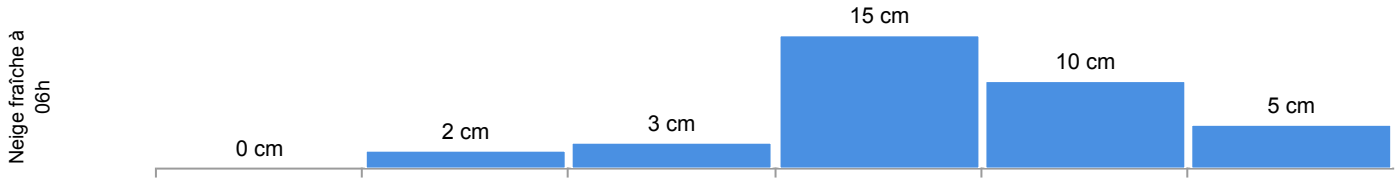

Risque d'avalanche	sam. 07/02	dim. 08/02	lun. 09/02	mar. 10/02	mer. 11/02	jeu. 12/02	ven. 13/02
	4	3	3	3	4	4	4

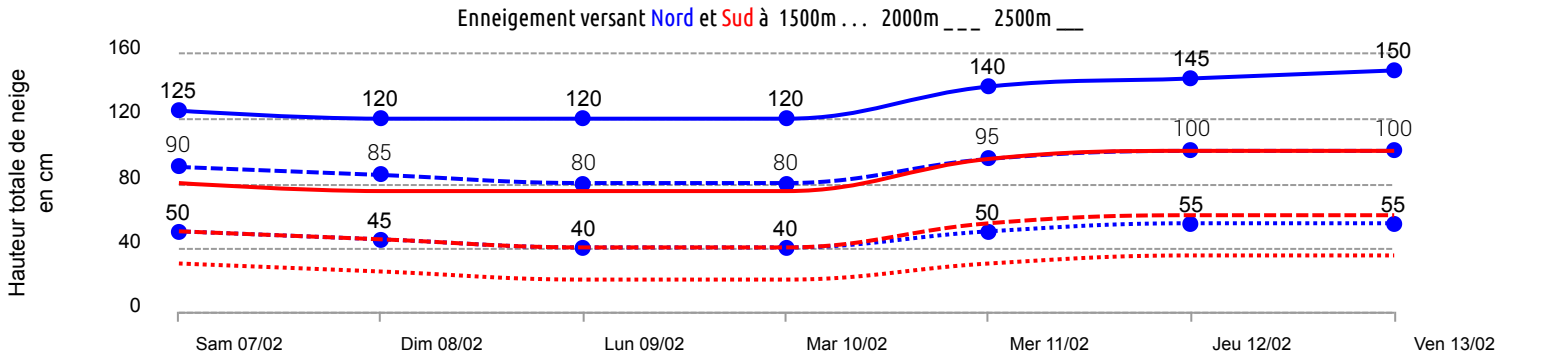

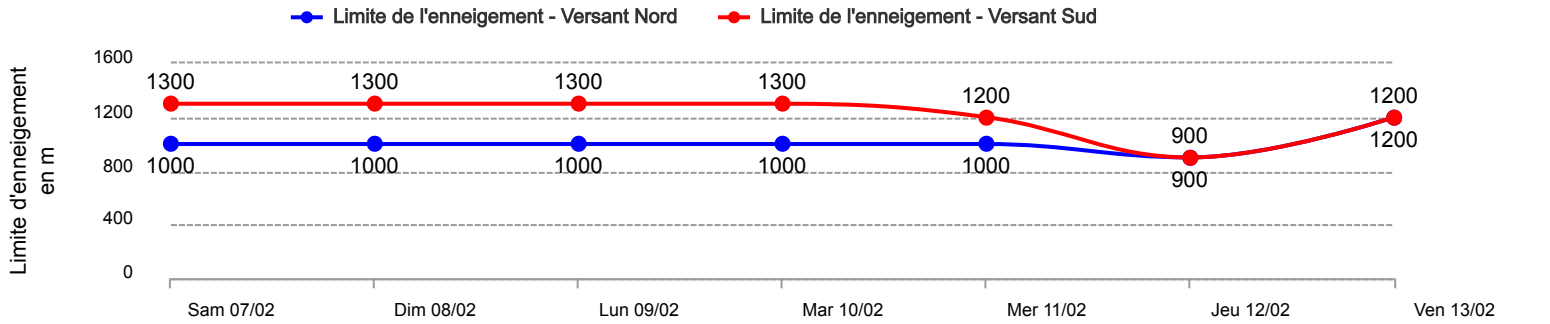

Pour consulter la vigilance en cours, veuillez vous rendre sur le site https://vigilance.meteofrance.fr/fr

Météo-France - 73 avenue de Paris, 94165 Saint-Mandé cedex - Contact : contact@meteo.fr

Bulletin neige & avalanches par téléphone au **0 892 68 10 20** Service 0,35 € / min + prix appel

Rédigé par Météo-France avec la contribution des observateurs du réseau nivo-météorologiques. Partenariat : ANMSM (Maires de Stations de Montagne), DSF (Domaines Skiables de France), ADSP (Directeurs de Pistes et de la Sécurité des Stations de Sports d'Hiver) et autres acteurs de la montagne.