Bulletin d'estimation du risque d'avalanche
(valable en dehors des pistes balisées et ouvertes)

MASSIF : Thabor

Rédigé le vendredi 13 février 2026 à 17h

Estimation des risques pour le : SAMEDI 14 FÉVRIER

FORTE INSTABILITÉ PERSISTANTE - PLAQUES POTENTIELLEMENT ÉPAISSES, FACILES À DÉCLENCHER

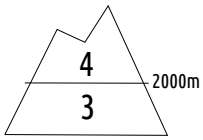

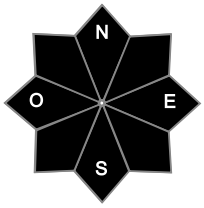

Au-dessus de 2000m indice de risque fort, plus bas indice marqué.

Départs spontanés : possibles avalanches de plaque

Déclenchements provoqués : plaques dans de nombreuses pentes, faciles à déclencher, potentiellement épaisses et larges.

Indices de risque : 5 très fort - 4 fort - 3 marqué - 2 limité - 1 faible -- En noir : les pentes les plus dangereuses

Stabilité du manteau neigeux

Situation avalancheuse typique : neige fraîche couche fragile persistante

Invitation à la prudence en montagne (émission d'un communiqué spécial avalanche)

Déclenchements provoqués : manteau neigeux restant instable. Au-dessus 1800/2000 m, plaques en place dans de nombreuses orientations, d'autres en formation en altitude avec un peu de neige fraîche et le transport par le vent. Faciles à déclencher par le passage d'un seul skieur, pouvant mobiliser de très importants volumes de neige dans les pentes les plus chargées. Un premier départ plus superficiel peut aussi favoriser une rupture en cascade. Cassures épaisses, sur de grandes largeurs et distances, notamment en cas de sollicitation de la couche fragile persistante enfouie.
Plus bas, le risque de déclencher une plaque est moins fort, car la neige récente est en partie humidifiée.

Départs spontanés : possibles avalanches de plaque de taille moyenne, voire grande. Activité surtout en lien avec le transport de la neige par le vent.

Qualité de la neige

L'enneigement est excédentaire pour un mois de février, avec les chutes de neige qui s'enchainent.
Hauteurs de neige observées vers 2500 m : 189 cm dans le vallon du Chardonnet, 103 cm à la Nivôse du Galibier, 111 cm à celle des Rochilles.

Limite d'enneigement skiable : la plupart des itinéraires sont skiables dès les fonds de vallées.

État de la neige de surface : neige fraiche/récente abondante souvent travaillée par le vent en altitude. Plus lourde, voire humide sous 1800/2000 m.

Aperçu météo pour le samedi 14 février

Cumuls de neige fraiche nuit + quelques averses en journée : 10/15 cm vers la Savoie, 3/5 cm sur le reste du massif.

	nuit	matin	après-midi	soir
Pluie-Neige	1 200 m	1 200 m	1 200 m	1 200 m
Iso 0 °C	1 400 m	1 400 m	1 600 m	1 600 m
Vent 2000 m	↙ 25 km/h	↙ 20 km/h	↘ 15 km/h	↓ 20 km/h
Vent 3000 m	← 55 km/h	← 40 km/h	↘ 55 km/h	↘ 55 km/h

Épaisseur de neige hors-piste

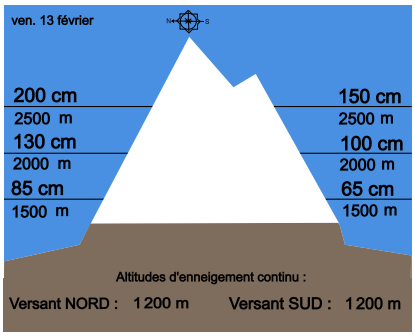

Précipitations à 1800 m

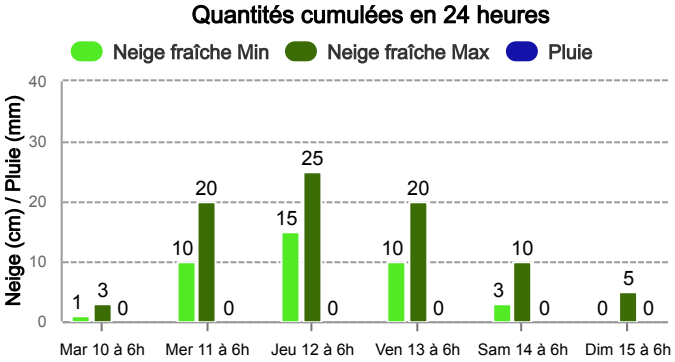

Tendance du dimanche 15 février

Indice de risque marqué

Risque marqué avec des plaques encore réactives, pouvant être volumineuses.

Pour consulter la vigilance en cours, veuillez vous rendre sur le site https://vigilance.meteofrance.fr/fr

Météo-France - 73 avenue de Paris, 94165 Saint-Mandé cedex - Contact : contact@meteo.fr

Rédigé par Météo-France avec la contribution des observateurs du réseau nivo-météorologiques. Partenariat : ANMSM (Maires de Stations de Montagne), DSF (Domaines Skiables de France), ADSP (Directeurs de Pistes et de la Sécurité des Stations de Sports d'Hiver) et autres acteurs de la montagne.

Bulletin neige & avalanches par téléphone au **0 892 68 10 20** Service 0,35 € / min + prix appel

Bulletin d'estimation du risque d'avalanche

(valable en dehors des pistes balisées et ouvertes)

MASSIF : Thabor

Rédigé le vendredi 13 février 2026 à 17h

Conditions nivo-météo des 7 derniers jours

	sam. 07/02				dim. 08/02				lun. 09/02				mar. 10/02				mer. 11/02				jeu. 12/02				ven. 13/02			
	03h	09h	15h	21h	03h	09h	15h	21h	03h	09h	15h	21h	03h	09h	15h	21h	03h	09h	15h	21h	03h	09h	15h	21h	03h	09h	15h	21h
Météo																												
Vent (km/h)	5	5	10	10	15	20	30	30	15	15	10	20	30	30	50	80	60	60	70	60	90	80	120	100	75	25	40	45
à 3000m																												
Vent (km/h)	5	5	5	5	10	15	20	20	10	10	10	10	10	15	20	20	25	30	35	25	40	45	65	65	45	15	25	20
à 2000m																												

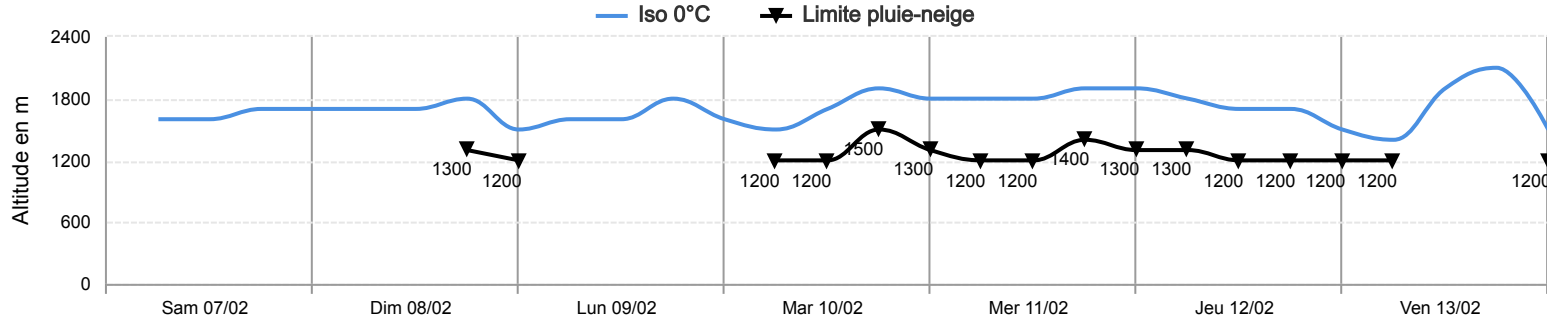

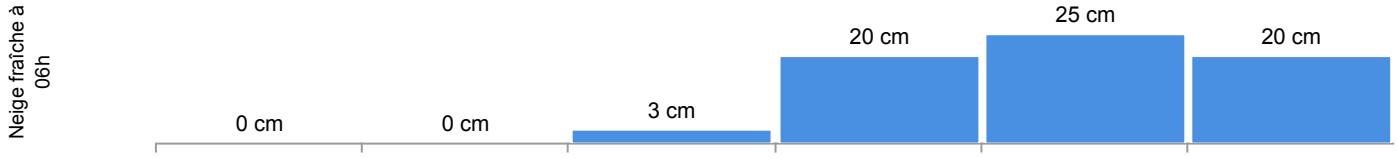

Risque d'avalanche	sam. 07/02	dim. 08/02	lun. 09/02	mar. 10/02	mer. 11/02	jeu. 12/02	ven. 13/02
	4	3	3	3	4	4	4

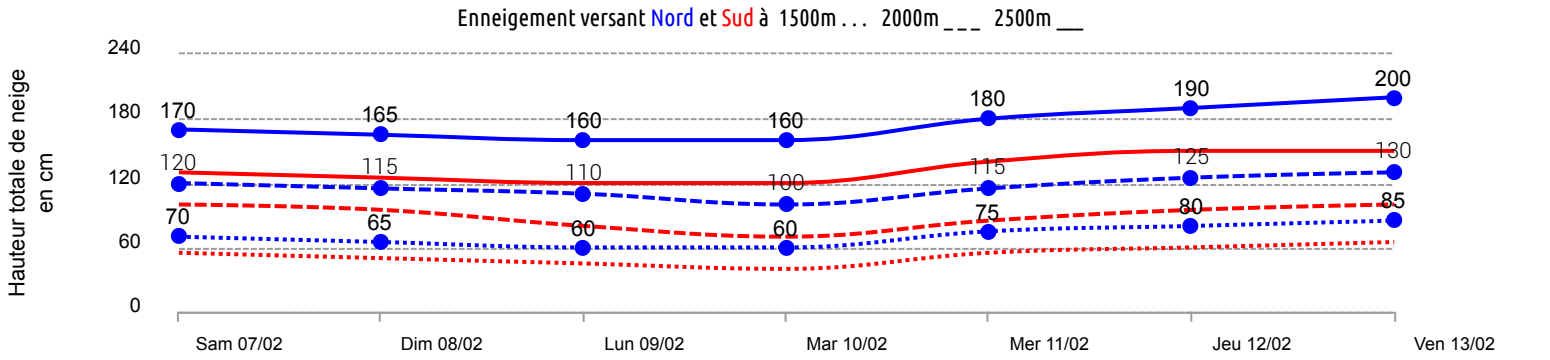

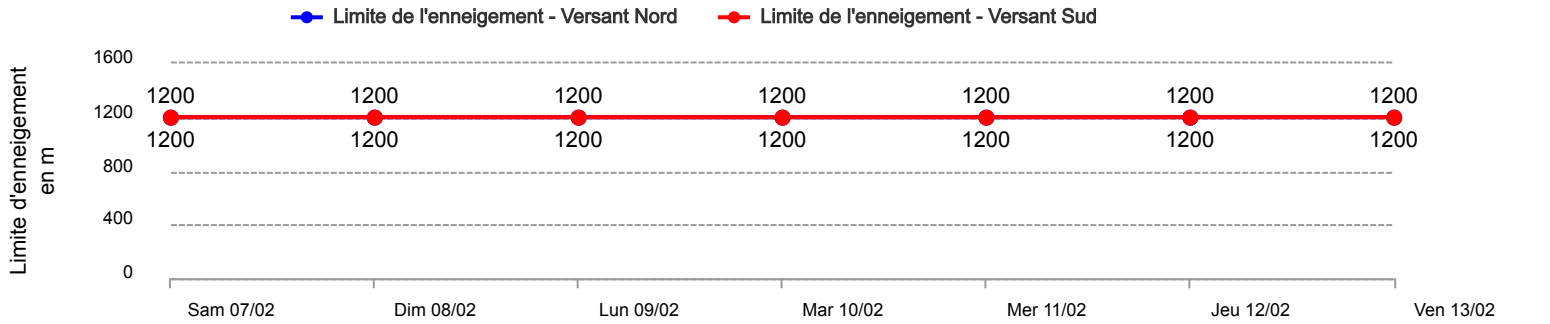

Pour consulter la vigilance en cours, veuillez vous rendre sur le site https://vigilance.meteofrance.fr/fr

Météo-France - 73 avenue de Paris, 94165 Saint-Mandé cedex - Contact : contact@meteo.fr

Rédigé par Météo-France avec la contribution des observateurs du réseau nivo-météorologiques. Partenariat : ANMSM (Maires de Stations de Montagne), DSF (Domaines Skiables de France), ADSP (Directeurs de Pistes et de la Sécurité des Stations de Sports d'Hiver) et autres acteurs de la montagne.

Bulletin neige & avalanches par téléphone au

0 892 68 10 20 Service 0,35 € / min + prix appel