Bulletin d'estimation du risque d'avalanche

(valable en dehors des pistes balisées et ouvertes)

MASSIF : Ubaye

Rédigé le vendredi 13 février 2026 à 17h

Estimation des risques pour le : SAMEDI 14 FÉVRIER

NOMBREUSES INSTABILITÉS EN ALTITUDE, FACILES À DÉCLENCHER ET PARFOIS TRÈS VOLUMINEUSES EN HAUTE-UBAYE

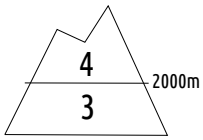

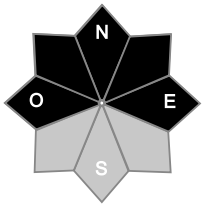

Au-dessus de 2000m indice de risque fort, plus bas indice marqué.

Départs spontanés : départs dans la neige fraiche ventée, parfois volumineux.

Déclenchements provoqués : nombreuses instabilités dans la neige récente ventée, parfois très volumineuses en Haute-Ubaye, en ubacs d'altitude.

Indices de risque : 5 très fort - 4 fort - 3 marqué - 2 limité - 1 faible -- En noir : les pentes les plus dangereuses

Stabilité du manteau neigeux

Situation avalancheuse typique : neige ventée couche fragile persistante

Communiqué spécial avalanches : invitation à la prudence en montagne

Déclenchements provoqués : nombreuses plaques en place dans la neige récente ventée, possible en toutes orientations principalement au-dessus de 1800/2000 m. Plaques souvent en neige durcie par le vent, mais pouvant être masqués par la couche de neige fraîche en surface. Elles sont encore déclenchables par un seul skieur, et de taille petite à moyenne (taille 1 à 2), parfois grande (taille 3) dans les zones de forte accumulation par le vent. En orientations ouest, nord et est d'altitude supérieure à 2000 m environ, on retrouve des couches fragiles persistantes enfouies encore sollicitables par un skieur notamment en Haute-Ubaye, générant des plaques plus volumineuses avec des cassures larges et épaisses. Avalanche de grande taille (taille 3) voir très grande taille non exclue (taille 4).

Départs spontanés : quelques départs ponctuels pendant les chutes de neige et départs linéaires avec le transport de neige fraiche par le vent. Avalanche de taille petite à moyenne (taille 1 à 2), rarement grande (taille 3) dans les zones de forte accumulation par le vent, ou en cas de déstabilisations d'une plaque plus ancienne, notamment en versant ouest nord et est d'altitude.

Qualité de la neige

Enneigement plutôt excédentaire pour un mois de février.
Données observées : 115 cm au-dessus de Larche à 2270 m en adret et 120/150 cm à 2000 en ubacs. En vallée, 11 cm à Barcelonnette à 1200 m.

Enneigement skiable dès 1300/1400 m en terrain favorable, mais peu de sous-couche sous 1600 m en général.

État de la neige en surface : On retrouve en surface 5 à 10 cm de neige fraîche, fortement travaillée/durcie par le vent. Elle repose sur une sous-couche généralement dure ou regelée, mais parfois en poudreuse dense en ubacs abrités du vent. Neige s'humidifiant en journée en dessous de 1800/2200 selon les orientations.

Aperçu météo pour le samedi 14 février

	nuit	matin	après-midi	soir
	Temps voilé à couvert, avec des chutes de neige le long de la frontière italienne, donnant localement 1 à 5 cm.			
Pluie-Neige	1 200 m			
Iso 0 °C	1 500 m	1 700 m	2 000 m	1 700 m
Vent 2000 m	← 50 km/h	↙ 45 km/h	↓ 30 km/h	↓ 25 km/h
Vent 3000 m	← 70 km/h	← 65 km/h	↓ 45 km/h	↓ 35 km/h

Épaisseur de neige hors-piste

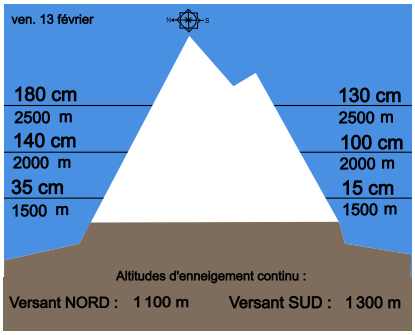

Précipitations à 1800 m

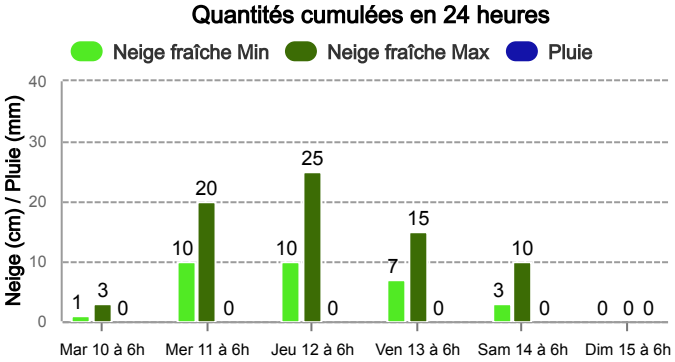

Tendance du dimanche 15 février

Indice de risque marqué

Risque marqué, avec des plaques en cours de stabilisation, mais restant fréquentes dans la neige récente, parfois volumineuses en versant nord.

Pour consulter la vigilance en cours, veuillez vous rendre sur le site https://vigilance.meteofrance.fr/fr

Météo-France - 73 avenue de Paris, 94165 Saint-Mandé cedex - Contact : contact@meteo.fr

Rédigé par Météo-France avec la contribution des observateurs du réseau nivo-météorologiques. Partenariat : ANMSM (Maires de Stations de Montagne), DSF (Domaines Skiables de France), ADSP (Directeurs de Pistes et de la Sécurité des Stations de Sports d'Hiver) et autres acteurs de la montagne.

Bulletin neige & avalanches par téléphone au **0 892 68 10 20** Service 0,35 € / min + prix appel

RÉPUBLIQUE FRANÇAISE
Liberté Égalité Fraternité

METEO FRANCE
À VOS CÔTÉS, DANS UN CLIMAT QUI CHANGE

Bulletin d'estimation du risque d'avalanche

(valable en dehors des pistes balisées et ouvertes)

MASSIF : Ubaye

Rédigé le vendredi 13 Février 2026 à 17h

Conditions nivo-météo des 7 derniers jours

	sam. 07/02				dim. 08/02				lun. 09/02				mar. 10/02				mer. 11/02				jeu. 12/02				ven. 13/02			
	03h	09h	15h	21h	03h	09h	15h	21h	03h	09h	15h	21h	03h	09h	15h	21h	03h	09h	15h	21h	03h	09h	15h	21h	03h	09h	15h	21h
Météo																												
Vent (km/h)	30	15	15	10	10	25	25	15	15	25	25	30	30	35	45	55	65	60	40	60	75	85	80	75	45	10	30	50
à 3000m	↘	←	↖	↘	↘	↖	↖	←	←	↗	→	→	→	→	→	→	→	→	→	→	→	→	→	→	→	→	↑	←
Vent (km/h)	10	10	10	10	10	15	20	15	10	10	15	10	10	15	20	20	25	35	30	25	35	70	60	55	35	5	20	40
à 2000m	↘	↖	→	←	↖	↖	←	←	←	↑	→	↑	↗	→	→	→	→	↘	→	→	→	↘	→	↘	↘	↗	↑	←

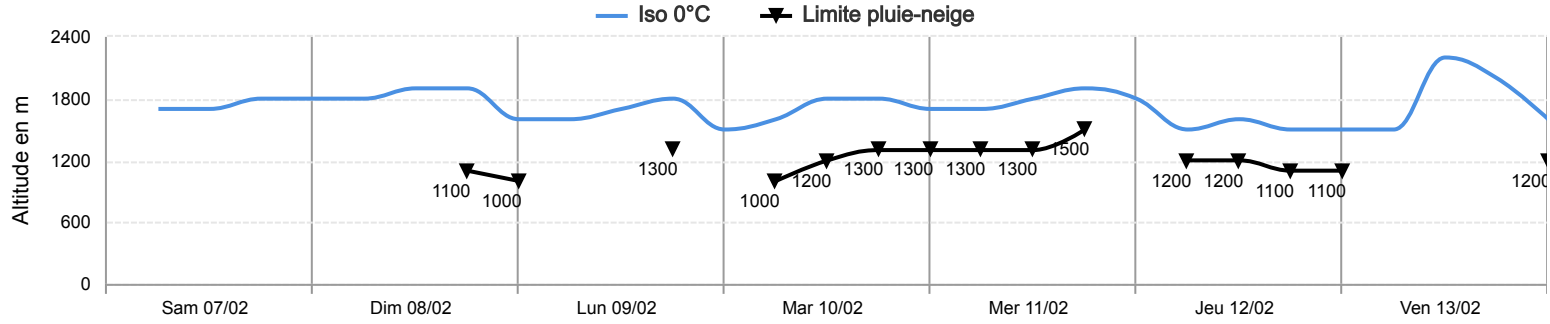

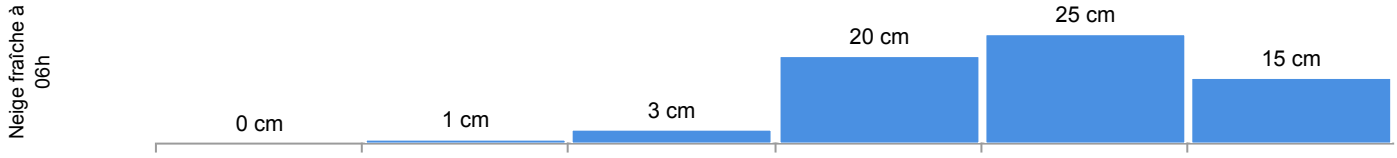

Risque d'avalanche	sam. 07/02	dim. 08/02	lun. 09/02	mar. 10/02	mer. 11/02	jeu. 12/02	ven. 13/02
	4	3	3	3	4	4	4

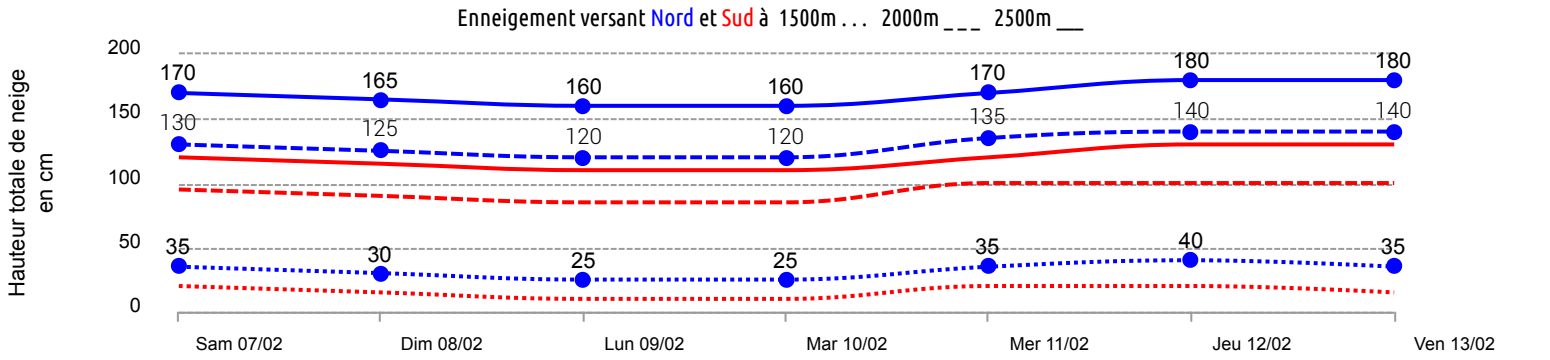

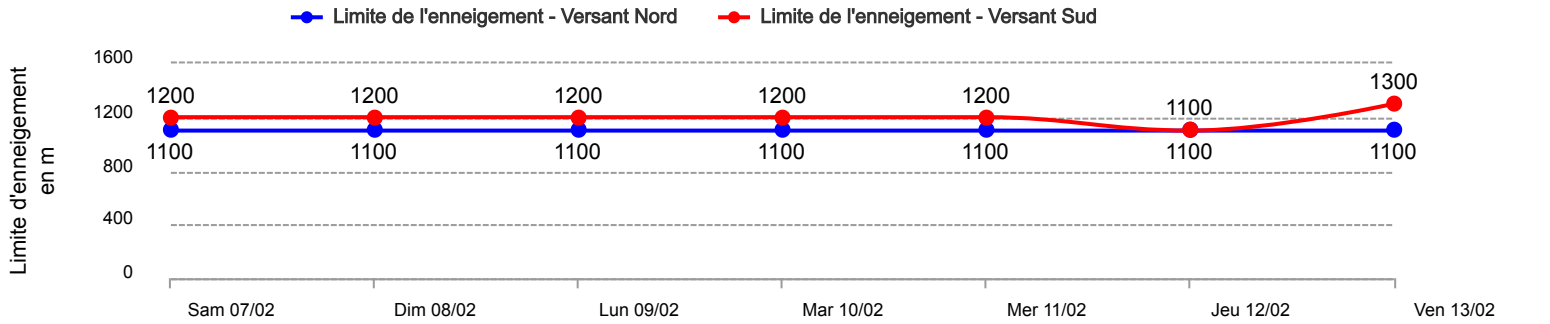

Pour consulter la vigilance en cours, veuillez vous rendre sur le site https://vigilance.meteofrance.fr/fr

Météo-France - 73 avenue de Paris, 94165 Saint-Mandé cedex - Contact : contact@meteo.fr

Rédigé par Météo-France avec la contribution des observateurs du réseau nivo-météorologiques. Partenariat : ANMSM (Maires de Stations de Montagne), DSF (Domaines Skiables de France), ADSP (Directeurs de Pistes et de la Sécurité des Stations de Sports d'Hiver) et autres acteurs de la montagne.

Bulletin neige & avalanches par téléphone au
0 892 68 10 20 Service 0,35 € / min + prix appel