GOBIERNO DE ESPAÑA
VICEPRESIDENCIA TERCERA DEL GOBIERNO
MINISTERIO PARA LA TRANSICIÓN ECOLÓGICA Y EL RETO DEMOGRÁFICO

Boletín de información nivológica y de peligro de aludes

Pirineo Catalán

aemet Agencia Estatal de Meteorología

sábado, 14 de febrero de 2026

Pronóstico hasta las 24 horas del domingo, día 15 de febrero

(Válido fuera de pistas de esquí balizadas y abiertas)

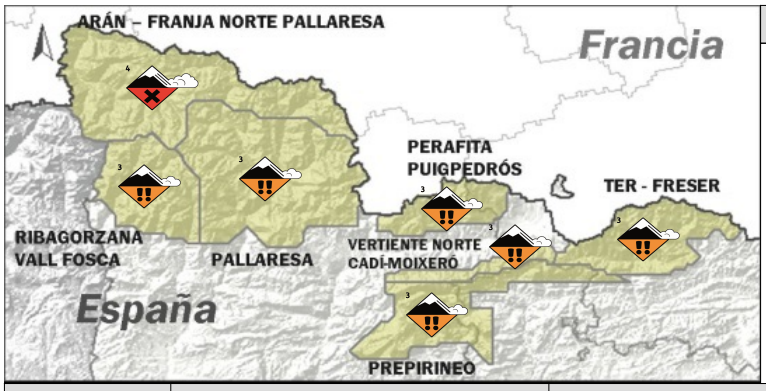

Problemas de aludes

Placas de viento

Nieve reciente

Macizo	Peligro	Problemas de aludes, cota, orientación, tamaño	Innivación observada (m)
Arán - Franja norte Pallaresa	4 Fuerte	Placas de viento: 2100, N O E S, 3 Nieve reciente: N O E S, 2	2026-02-14 N S Cotas bajas
Ribagorzana - Vall Fosca	3 Notable	Placas de viento: 2100, N O E S, 3	2026-02-14 N S Cotas bajas
Pallaresa	3 Notable	Placas de viento: 2100, N O E S, 3	2026-02-14 N S Cotas bajas
Perafita - Puigpedrós	3 Notable	Placas de viento: 2100, N O E S, 2	2026-02-14 N S Cotas bajas
Ter - Freser	3 Notable	Placas de viento: 2100, N O E S, 2	2026-02-14 N S Cotas bajas

AEMET. Se autoriza la reproducción de su contenido citando la fuente.

Boletín de información nivológica y de peligro de aludes

Pirineo Catalán

Vertiente norte Cadí - Moixeró	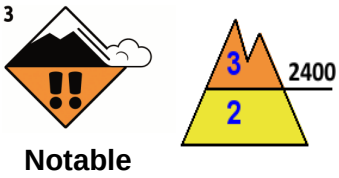	**Placas de viento**	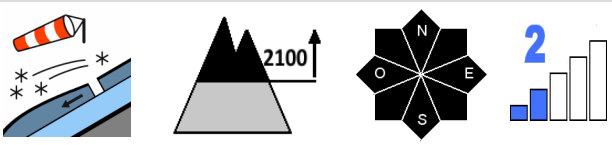	2026-02-14
Prepirineo	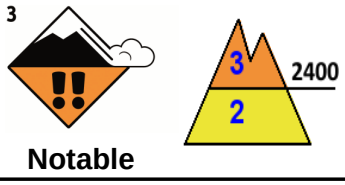	**Placas de viento**	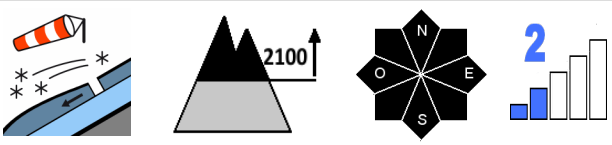	2026-02-14

Estado del manto y observaciones recientes

De nuevo se han producido precipitaciones, en forma sólida desde cotas bajas, que han depositado durante las últimas 24 horas cantidades superiores a los 30 cm localmente. La nieve es continua desde cotas bajas, con espesores que en la mayor parte de la cordillera se encuentran en máximos, muy por encima de lo que cabría esperar a estas alturas de la temporada, superándose los 150 a 200 cm por encima de 2.200 metros en numerosas áreas.

El perfil del manto consta de múltiples capas, la más externa de nieve reciente de grosor variable y algunas de ellas estratos de nieve encostrada, aunque predomina el grano fino y grano redondo. En la alta montaña la nieve se presenta más seca, venteada y menos evolucionada, y todavía podría haber estratos débiles en zonas de umbría.

Evolución del manto y peligro de aludes para el domingo, día 15

Situación de placas de viento en cotas altas, así como de nieve reciente.

Tras las nevadas que se han venido registrando, así como las que se prevén durante las próximas horas, el manto podrá purgarse y serán muy probables las salidas naturales de nieve reciente en pendientes con suficiente inclinación y sin orientación preferente, en general de tamaño pequeño o mediano, aunque no es descartable alguno de mayor magnitud en zonas donde los acumulados sean importantes.

Los fuertes vientos de componentes oeste y norte que han venido soplando han formado numerosas placas en diferentes áreas de cotas altas, aunque con preferencia en orientaciones este y sur, que en ocasiones pueden estar alejadas de crestas y cordales. Estas vendrán a sumarse a las que ya existían previamente, algunas de ellas asentadas sobre estratos débiles, y que han quedado enterradas tras estas nevadas, lo que dificulta aún más su localización. Todas estas estructuras permanecen frágiles y podrán fracturarse ante sobrecargas débiles, dando lugar a aludes que podrán ser de dimensiones grandes, suficiente como para enterrar a un grupo de personas, por lo que se recomienda extremar las precauciones si se va a transitar por la zona.

Predicción meteorológica para el domingo, día 15

Intervalos nubosos, aumentando a muy nuboso o cubierto. Se esperan precipitaciones débiles y ocasionales en el valle de Arán y Franja Norte Pallaresa, que tenderán a generalizarse e intensificarse al final del día, pudiendo afectar al resto del territorio. Cota de nieve: subiendo de cualquier altitud hasta unos 1.600 ó 1.800 metros. Temperaturas mínimas en ligero o

AEMET. Se autoriza la reproducción de su contenido citando la fuente.

moderado descenso, y máximas en ligero o moderado ascenso. Heladas débiles, moderadas o localmente fuertes en cotas altas. Vientos fuertes del norte y noroeste, con rachas muy fuertes, pudiendo ser huracanadas en cotas altas y zonas expuestas.

Datos en la atmósfera libre:

Altitud de la isoterma de 0 ºC: 2.300 m
Altitud de la isoterma de -10 ºC: 4.400 m

Viento a 1500 m: NW 40 km/h
Viento a 3000 m: NW 70 km/h

Evolución para el lunes día 16

Nivel de peligro sin grandes cambios, aunque tenderá aumentar el asociado a nieve húmeda.

Escala europea de peligro de aludes

Débil | Limitado | Notable | Fuerte | Muy Fuerte

Problemas de aludes

Nieve reciente | Placas de viento | Capas débiles persistentes | Nieve húmeda | Deslizamientos basales | Sin problema evidente

Nota1: Se recuerda que, siempre que haya nieve, la ausencia total de peligro no existe. Hay que tener presente que en circunstancias desfavorables, con aludes de tamaño 1 (alud pequeño o colada) y tamaño 2 (alud mediano), se pueden sufrir severos daños personales.

Nota2: Los BPA se elaboran en base a información meteorológica así como al estado del manto nivoso a través de sondeos puntuales. Se advierte a los usuarios de la variabilidad de esta información al extrapolarla a zonas extensas de montaña. Por ello, AEMET no se hace responsable de su uso para la toma de decisiones que conciernen a la seguridad personal, ni de los riesgos físicos o materiales de ellas derivadas.

AEMET. Se autoriza la reproducción de su contenido citando la fuente.