GOBIERNO DE ESPAÑA
VICEPRESIDENCIA TERCERA DEL GOBIERNO
MINISTERIO PARA LA TRANSICIÓN ECOLÓGICA Y EL RETO DEMOGRÁFICO

Boletín de información nivológica y de peligro de aludes

Pirineo Navarro y Aragonés

aemet Agencia Estatal de Meteorología

sábado, 14 de febrero de 2026

Pronóstico hasta las 24 horas del domingo, día 15 de febrero

(Válido fuera de pistas de esquí balizadas y abiertas)

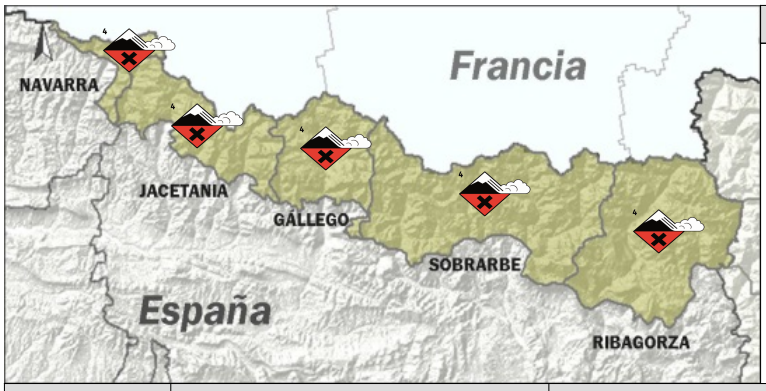

Problemas de aludes

Placas de viento

Nieve reciente

Macizo	Peligro	Problemas de aludes, cota, orientación, tamaño	Innivación observada (m)
Navarra	4 Fuerte	Placas de viento: 2100, N O E S, 3 Nieve reciente: N O E S, 2	2026-02-14 N S Cotas bajas
Jacetania	4 Fuerte	Placas de viento: 2100, N O E S, 3 Nieve reciente: N O E S, 2	2026-02-14 N S Cotas bajas
Gállego	4 Fuerte	Placas de viento: 2100, N O E S, 3 Nieve reciente: N O E S, 2	2026-02-14 N S Cotas bajas

AEMET. Se autoriza la reproducción de su contenido citando la fuente.

Boletín de información nivológica y de peligro de aludes

Pirineo Navarro y Aragonés

Sobrarbe	 **Fuerte**	**Placas de viento** 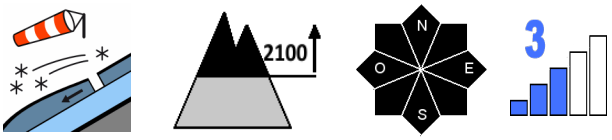 **Nieve reciente** 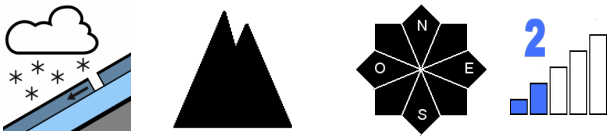	2026-02-14
Ribagorza	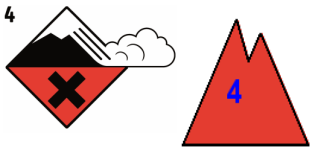 **Fuerte**	**Placas de viento** 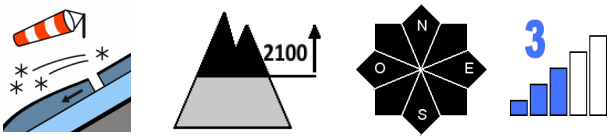 **Nieve reciente** 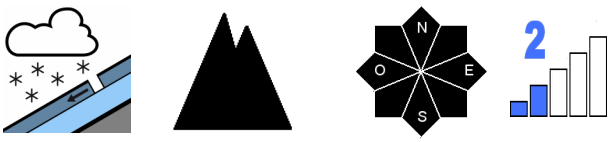	2026-02-14

Estado del manto y observaciones recientes

Nuevamente se han producido precipitaciones, en forma sólida desde cotas bajas, que han depositado durante las últimas 24 horas cantidades de nieve reciente superiores a los 30 cm en algunos de los puntos de observación. El manto es continuo desde fondos de valle, con espesores importantes y muy por encima del promedio habitual a estas alturas de la temporada, pues en torno a 2.100 metros se superan fácilmente los 180 a 200 cm, aún más en ventisqueros, hoyas y otras zonas propensas a la acumulación.

El perfil del manto consta de múltiples capas, la más externa de nieve reciente de grosor variable y algunas de ellas compuestas por estratos encostrados, aunque predomina el grano fino y grano redondo. En la alta montaña la nieve se presenta más seca, venteada y menos evolucionada, y todavía podrían hallarse estratos débiles en zonas de umbría.

Se han registrado algunos aludes de nieve reciente húmeda, de tamaño pequeño en general.

Evolución del manto y peligro de aludes para el domingo, día 15

Situación de placas de viento en cotas altas, así como de nieve reciente.

Tras las intensas nevadas que se han venido registrando, así como las que se prevén durante las próximas horas, el manto podrá purgarse y serán muy probables las salidas naturales de nieve reciente en pendientes con suficiente inclinación y sin orientación preferente, en general de tamaño pequeño o mediano, aunque no es descartable alguno de mayor magnitud en zonas donde los acumulados sean importantes.

Los fuertes vientos de componentes oeste y norte que han venido soplando en la cordillera han formado numerosas placas en diferentes áreas de cotas altas, aunque con preferencia en orientaciones este y sur, que en ocasiones pueden hallarse alejadas de crestas y cordales.

AEMET. Se autoriza la reproducción de su contenido citando la fuente.

Estas vendrán a sumarse a las que ya existían previamente, algunas de ellas asentadas sobre estratos débiles, y que han quedado enterradas tras estas nevadas, lo que dificulta aún más su localización. Todas estas estructuras permanecen frágiles y podrán fracturarse ante sobrecargas débiles, dando lugar a aludes que podrán ser de dimensiones grandes, suficiente como para enterrar a un grupo de personas, por lo que se recomienda extremar las precauciones si se va a transitar por la zona.

Predicción meteorológica para el domingo, día 15

Nuboso, aumentando a muy nuboso o cubierto. Se esperan precipitaciones débiles y ocasionales en el Pirineo navarro y divisoria con Francia del aragonés, que tenderán a generalizarse e intensificarse al final del día, pudiendo afectar al resto de las zonas. Cota de nieve: subiendo de cualquier altitud a unos 1.600 a 1.800 metros. Temperaturas mínimas sin cambios o en ligero descenso, y máximas en moderado ascenso. Heladas débiles, moderadas o localmente fuertes en cotas altas. Vientos fuertes del norte y noroeste, con rachas muy fuertes, pudiendo ser huracanadas en la alta montaña y zonas expuestas.

Datos en la atmósfera libre:

Altitud de la isoterma de 0 ºC: 2.200 m
Altitud de la isoterma de -10 ºC: 4.500 m

Viento a 1500 m: NW 50 km/h
Viento a 3000 m: NW 70 km/h

Evolución para el lunes día 16

Nivel de peligro sin grandes cambios, aunque tenderá aumentar el asociado a nieve húmeda.

(Información elaborada a partir de los datos recibidos de los refugios de Lizara, Panticosa, Bachimaña, Góriz, Pineta, Estós, Angel Orús, Cap de Llauset y Belagua, de las estaciones de esquí de Candanchú, Astún y Panticosa (lagos) y de la estación de esquí de fondo de Llanos del Hospital)

Escala europea de peligro de aludes

Débil | Limitado | Notable | Fuerte | Muy Fuerte

Problemas de aludes

Nieve reciente | Placas de viento | Capas débiles persistentes | Nieve húmeda | Deslizamientos basales | Sin problema evidente

Nota1: Se recuerda que, siempre que haya nieve, la ausencia total de peligro no existe. Hay que tener presente que en circunstancias desfavorables, con aludes de tamaño 1 (alud pequeño o colada) y tamaño 2 (alud mediano), se pueden sufrir severos daños personales.

Nota2: Los BPA se elaboran en base a información meteorológica así como al estado del manto nivoso a través de sondeos puntuales. Se advierte a los usuarios de la variabilidad de esta información al extrapolarla a zonas extensas de montaña. Por ello, AEMET no se hace responsable de su uso para la toma de decisiones que conciernen a la seguridad personal, ni de los riesgos físicos o materiales de ellas derivadas.

AEMET. Se autoriza la reproducción de su contenido citando la fuente.