Sonntag 15.02.2026

Veröffentlicht am 14.02.2026 um 17:00

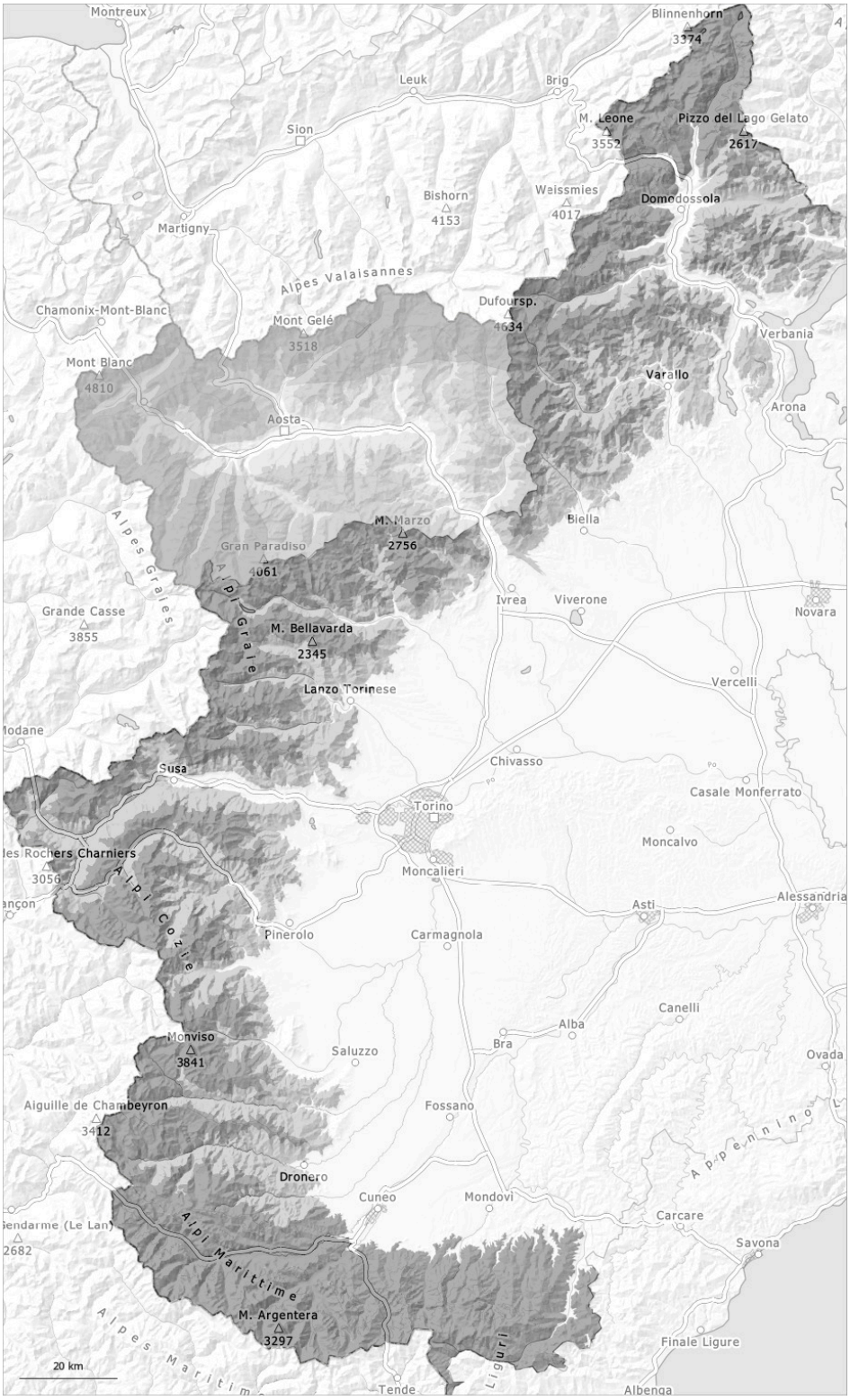

1	2	3	4	5
gering	mäßig	erheblich	groß	sehr groß

Gefahrenstufe 3 - Erheblich

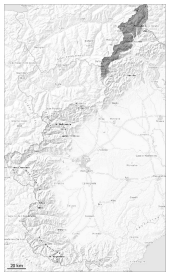

Tendenz: Lawinengefahr steigt
am Montag, den 16.02.2026

Triebschnee

Alte Triebschneeansammlungen werden teils überschneit und damit schwierig zu erkennen.

Die älteren Triebschneeansammlungen können schon von einzelnen Wintersportlern ausgelöst werden oder spontan abgehen. Die Gefahrenstellen liegen besonders in Rinnen, Mulden und hinter Geländekanten sowie an steilen Hängen. In der Höhe sind diese Gefahrenstellen häufiger.

Zudem können Lawinen auch im Altschnee anbrechen und groß werden.

Eine vorsichtige Routenwahl und Entlastungsabstände werden empfohlen.

Schneedecke

Gefahrenmuster gm.6: lockerer schnee und wind

Donnerstag: Der teilweise stürmische Wind hat den Neuschnee intensiv verfrachtet. Die verschiedenen Triebschneeansammlungen liegen vor allem an Schattenhängen auf weichen Schichten.

Gestern fiel etwas Schnee.

Mittlere und hohe Lagen: Im unteren Teil der Schneedecke sind vor allem an Schattenhängen grobkörnige Schwachschichten vorhanden.

Gefahrenstufe 3 - Erheblich

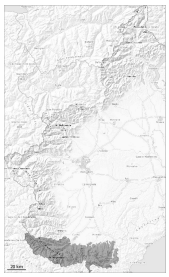

Tendenz: Lawinengefahr bleibt gleich
am Montag, den 16.02.2026

Triebschnee

Waldgrenze

Neuschnee

Der viele Neuschnee und insbesondere die verbreitet vorhandenen Triebschneeansammlungen können sehr leicht ausgelöst werden.

Gestern fiel Schnee oberhalb von rund 1000 m. Mit Neuschnee und mäßigem bis starkem Nordostwind entstanden vor allem an Südwest-, Süd- und Südosthängen teils dicke Triebschneeansammlungen.

Vor allem Sonnenhänge sowie Kammlagen, Rinnen und Mulden: Neu- und Triebschnee liegen auf einer harten Kruste.

Die frischen und schon etwas älteren Triebschneeansammlungen können an allen Expositionen und allgemein oberhalb der Waldgrenze von einzelnen Wintersportlern ausgelöst werden.

Eine vorsichtige Routenwahl und Entlastungsabstände werden empfohlen.

Schneedecke

Gefahrenmuster gm.6: lockerer schnee und wind

Vor allem Kamm- und Passlagen und hohe Lagen und Hochgebirge: In den letzten vier Tagen entstanden harte Triebschneeansammlungen.

Vor allem Sonnenhänge tiefe und mittlere Lagen: Die Altschneedecke ist hart, mit einer Schmelzharschkruste an der Oberfläche.

An den oben beschriebenen Stellen werden sich die neuen Triebschneeansammlungen schlecht mit dem Altschnee verbinden.

Gefahrenstufe 3 - Erheblich

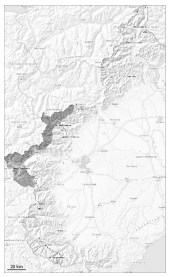

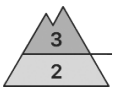

Waldgrenze

Tendenz: Lawinengefahr bleibt gleich
am Montag, den 16.02.2026

Triebschnee

Waldgrenze

Altschnee

Der Neuschnee und ganz besonders die Triebschneeansammlungen können oberhalb der Waldgrenze sehr leicht ausgelöst werden.

Die alten Triebschneeansammlungen sind teils überschneit und damit nur schwierig erkennbar. Diese können weiterhin schon von einzelnen Wintersportlern ausgelöst werden und groß werden. Dies vor allem in Rinnen, Mulden und hinter Geländekanten und an Triebschneehängen oberhalb der Waldgrenze.

Besonders gefährlich sind Triebschneehänge, wo Schwachstellen im Altschnee vorhanden sind. In der Altschneedecke sind vor allem an steilen Nordwest-, Nord- und Osthängen Schwachschichten vorhanden. Verschiedene Triebschneeschichten liegen stellenweise auf Oberflächenreif.
Stellenweise können Lawinen auch tiefere Schichten der Schneedecke mitreißen und sehr groß werden.

Schneedecke

Gefahrenmuster gm.6: lockerer schnee und wind

Gestern fiel Schnee oberhalb von rund 1400 m.

In den letzten Tagen entstanden verbreitet harte Triebschneeansammlungen. Der teilweise stürmische Wind hat den Neuschnee intensiv verfrachtet. In Gipfellagen liegen je nach Windeinfluss sehr unterschiedliche Schneehöhen.

Neu- und Triebschnee der letzten Tage liegen vor allem an windgeschützten Schattenhängen auf weichen Schichten.

In der Altschneedecke sind vor allem an steilen Nordwest-, Nord- und Nordosthängen Schwachschichten vorhanden.

Gefahrenstufe 3 - Erheblich

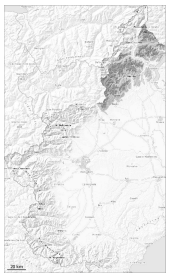

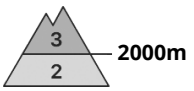

Tendenz: Lawinengefahr steigt
am Montag, den 16.02.2026

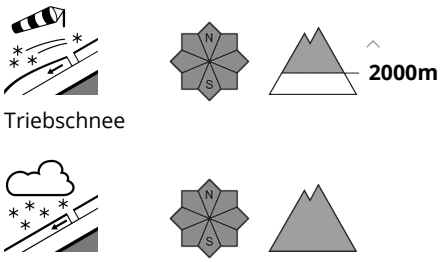

Triebschnee

Neuschnee

Frische und ältere Triebschneeansammlungen müssen vorsichtig beurteilt werden.

Gestern fiel Schnee oberhalb von rund 1400 m. Die alten Triebschneeansammlungen sind teils überschneit und damit nur schwierig erkennbar. Sie können teilweise von einzelnen Wintersportlern ausgelöst werden. Die Gefahrenstellen liegen besonders in Rinnen, Mulden und hinter Geländekanten sowie an Übergängen von wenig zu viel Schnee oberhalb von rund 2000 m. In der Höhe sind diese Gefahrenstellen häufiger.

In der Altschneedecke sind v.a. an steilen West-, Nord- und Osthängen Schwachschichten vorhanden. Sehr vereinzelt können Lawinen auch im Altschnee anbrechen und groß werden.

Schneedecke

Gefahrenmuster gm.6: lockerer schnee und wind

In der Altschneedecke sind v.a. an steilen West-, Nord- und Osthängen Schwachschichten vorhanden.

Gefahrenstufe 3 - Erheblich

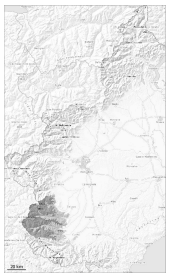

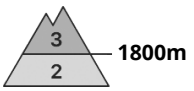

Tendenz: Lawinengefahr bleibt gleich
am Montag, den 16.02.2026

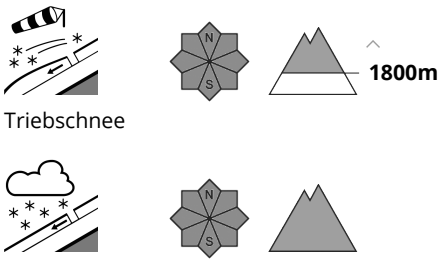

Triebschnee

Neuschnee

Neu- und Triebschnee können sehr leicht ausgelöst werden.

Gestern fiel Schnee oberhalb von rund 1000 m.
Mit Neuschnee und mäßigem Wind aus östlichen Richtungen entstanden teils dicke Triebschneeansammlungen.
Triebschneeansammlungen können schon von einzelnen Wintersportlern ausgelöst werden. Die Gefahrenstellen liegen vor allem in Rinnen, Mulden und hinter Geländekanten sowie an steilen Schattenhängen oberhalb von rund 2000 m.

Stellenweise können Lawinen auch im Altschnee anbrechen und groß werden.

Eine vorsichtige Routenwahl und Entlastungsabstände werden empfohlen.

Schneedecke

Gefahrenmuster gm.6: lockerer schnee und wind

In den letzten Tagen entstanden verbreitet harte Triebschneeansammlungen. Der teilweise stürmische Wind hat den Neuschnee intensiv verfrachtet. In Gipfellagen liegen je nach Windeinfluss sehr unterschiedliche Schneehöhen.

Mit Neuschnee und mäßigem Wind aus östlichen Richtungen entstehen teils dicke Triebschneeansammlungen. Die Triebschneeansammlungen liegen vor allem an windgeschützten Schattenhängen auf weichen Schichten.

In der Altschneedecke sind vor allem an steilen Nordwest-, Nord- und Nordosthängen Schwachschichten vorhanden.

Gefahrenstufe 3 - Erheblich

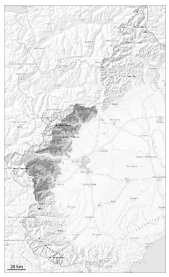

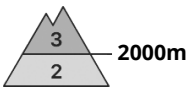

Tendenz: Lawinengefahr bleibt gleich
am Montag, den 16.02.2026

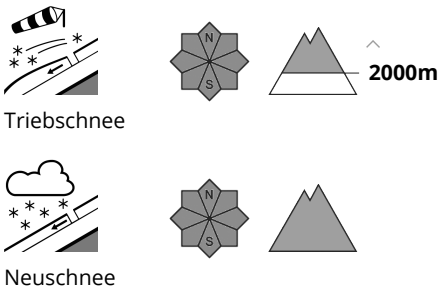

Neu- und Triebschnee können sehr leicht ausgelöst werden.

Gestern fiel Schnee oberhalb von rund 1000 m.
Mit Neuschnee und mäßigem Wind aus östlichen Richtungen entstanden teils dicke Triebschneeansammlungen.
Triebschneeansammlungen können schon von einzelnen Wintersportlern ausgelöst werden. Die Gefahrenstellen liegen vor allem in Rinnen, Mulden und hinter Geländekanten sowie an steilen Schattenhängen oberhalb von rund 2000 m.

Stellenweise können Lawinen auch im Altschnee anbrechen und groß werden.

Eine vorsichtige Routenwahl und Entlastungsabstände werden empfohlen.

Schneedecke

Gefahrenmuster gm.6: lockerer schnee und wind

In den letzten Tagen entstanden verbreitet harte Triebschneeansammlungen. Der teilweise stürmische Wind hat den Neuschnee intensiv verfrachtet. In Gipfellagen liegen je nach Windeinfluss sehr unterschiedliche Schneehöhen.

Mit Neuschnee und mäßigem Wind aus östlichen Richtungen entstehen teils dicke Triebschneeansammlungen. Die Triebschneeansammlungen liegen vor allem an windgeschützten Schattenhängen auf weichen Schichten.

In der Altschneedecke sind vor allem an steilen Nordwest-, Nord- und Nordosthängen Schwachschichten vorhanden.