Sonntag 15.02.2026

Veröffentlicht am 14.02.2026 um 17:00

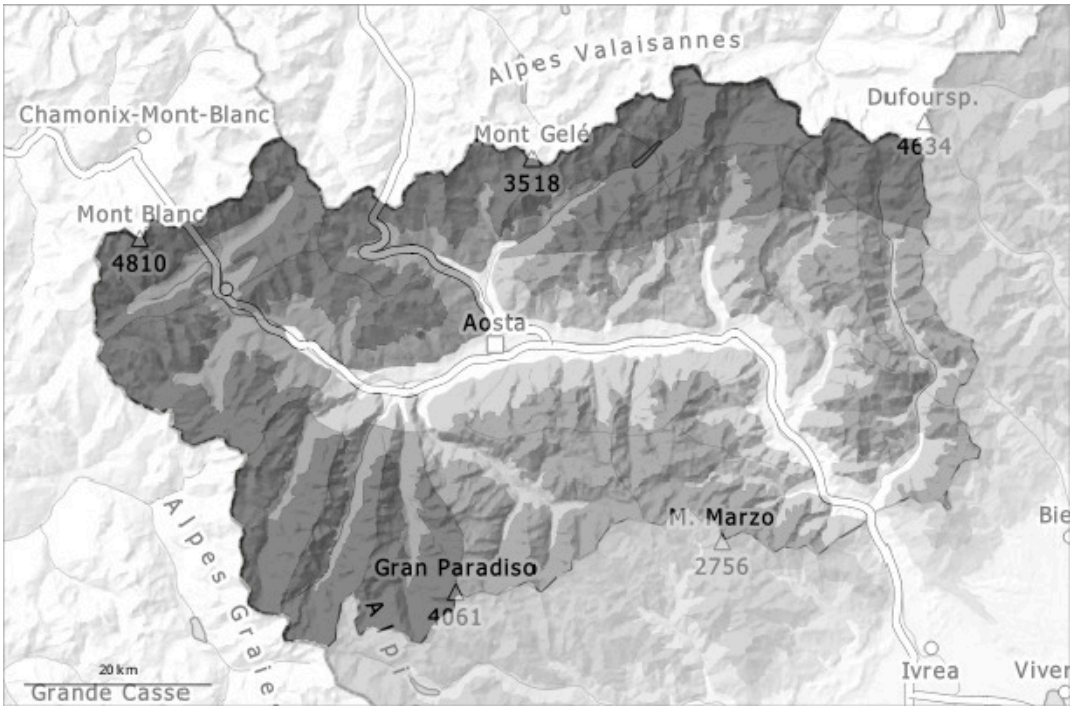

1	2	3	4	5
gering	mäßig	erheblich	groß	sehr groß

Gefahrenstufe 4 - Groß

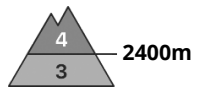

Tendenz: Lawinengefahr steigt
am Montag, den 16.02.2026

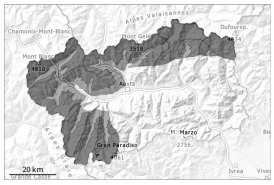

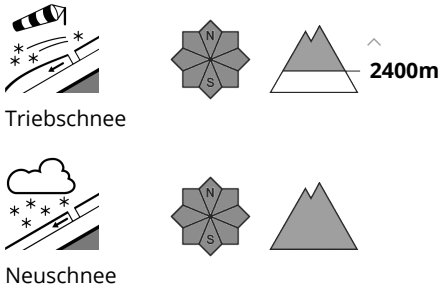

Allmählicher Anstieg der Gefahr von trockenen Lawinen mit dem starken Wind.

Mit dem starken Nordwestwind nehmen Anzahl und Größe der Gefahrenstellen zu. Hoch gelegene Einzugsgebiete werden mit dem Wind weiter aufgefüllt.
In den Hauptniederschlagsgebieten sind die Gefahrenstellen häufiger und größer, vor allem entlang der Grenze zu Frankreich und entlang der Grenze zur Schweiz.
Frische und ältere Triebschneeansammlungen können leicht ausgelöst werden oder spontan abgleiten. Vorsicht an steilen Hängen und in Rinnen, Mulden und hinter Geländekanten.
Besonders an sehr steilen Hängen und an Triebschneehängen sind weiterhin mittlere und vereinzelt große spontane Lawinen möglich. Die Lawinen können dort in tiefen Schichten ausgelöst werden und sehr groß werden. Für Touren und Variantenabfahrten abseits gesicherter Pisten sind die Verhältnisse heikel.

Schneedecke

Gefahrenmuster gm.6: lockerer schnee und wind | gm.1: bodennahe schwachschicht

Seit Mittwoch fielen oberhalb von rund 1800 m 70 bis 110 cm Schnee, lokal auch mehr.
Am Samstag fielen 5 bis 10 cm Schnee.
Die Wetterbedingungen führten zu einem ungünstigen Aufbau der Schneedecke. Der viele Neuschnee und die oft mächtigen Triebschneeansammlungen sind teils noch störanfällig. In Kamm- und Passlagen liegen je nach Windeinfluss sehr unterschiedliche Schneehöhen.
Seit Mittwoch sind viele große und vereinzelt sehr große spontane trockene Lawinen abgegangen.

Tendenz

Wind und Neuschnee. Die meteorologischen Bedingungen verursachen eine Zunahme der Lawinengefahr, vor allem in den Hauptniederschlagsgebieten.

Gefahrenstufe 3 - Erheblich

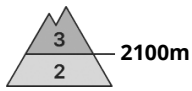

Tendenz: Lawinengefahr steigt
am Montag, den 16.02.2026

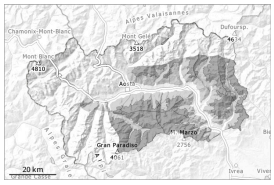

Triebschnee

2100m

Altschnee

2000m

Gefährlich sind Triebschneehänge, wo Schwachstellen im Altschnee vorhanden sind.

Mit dem starken Nordwestwind nehmen die Gefahrenstellen zu.
Frische und ältere Triebschneeansammlungen können von einzelnen Wintersportlern ausgelöst werden.
V.a. an extrem steilen Hängen und in Kammlagen sind aus noch nicht entladenen Einzugsgebieten weiterhin mittlere spontane Lawinen möglich. Diese sind meist oberflächlich.
Die Lawinen können stellenweise im Altschnee ausgelöst werden und recht groß werden.
Fernauslösungen sind möglich. Schwachschichten im Altschnee erfordern Vorsicht. Wummgeräusche und Risse beim Betreten der Schneedecke sind Alarmzeichen.

Schneedecke

Gefahrenmuster gm.6: lockerer schnee und wind | gm.1: bodennahe schwachschicht

Seit Dienstag fielen oberhalb von rund 1800 m 10 bis 30 cm Schnee, lokal auch mehr.
Am Samstag fielen 5 bis 10 cm Schnee.
Die Wetterbedingungen führten zu einem ungünstigen Aufbau der Schneedecke. Der starke Wind hat den Neuschnee intensiv verfrachtet.
In der Altschneedecke sind v.a. an West-, Nord- und Osthängen kantig aufgebaute Schwachschichten vorhanden.

Tendenz

Wind und Neuschnee. Die meteorologischen Bedingungen verursachen eine Zunahme der Lawinengefahr, vor allem in den Hauptniederschlagsgebieten.