ICGC Institut Cartogràfic i Geològic de Catalunya

Servei Meteorològic de Catalunya meteo.cat

Boletín de peligro de aludes para el Pirineo de Catalunya
Del 14/02/2026 al 16/02/2026

(Válido fuera pistas de esquí y zonas no controladas)

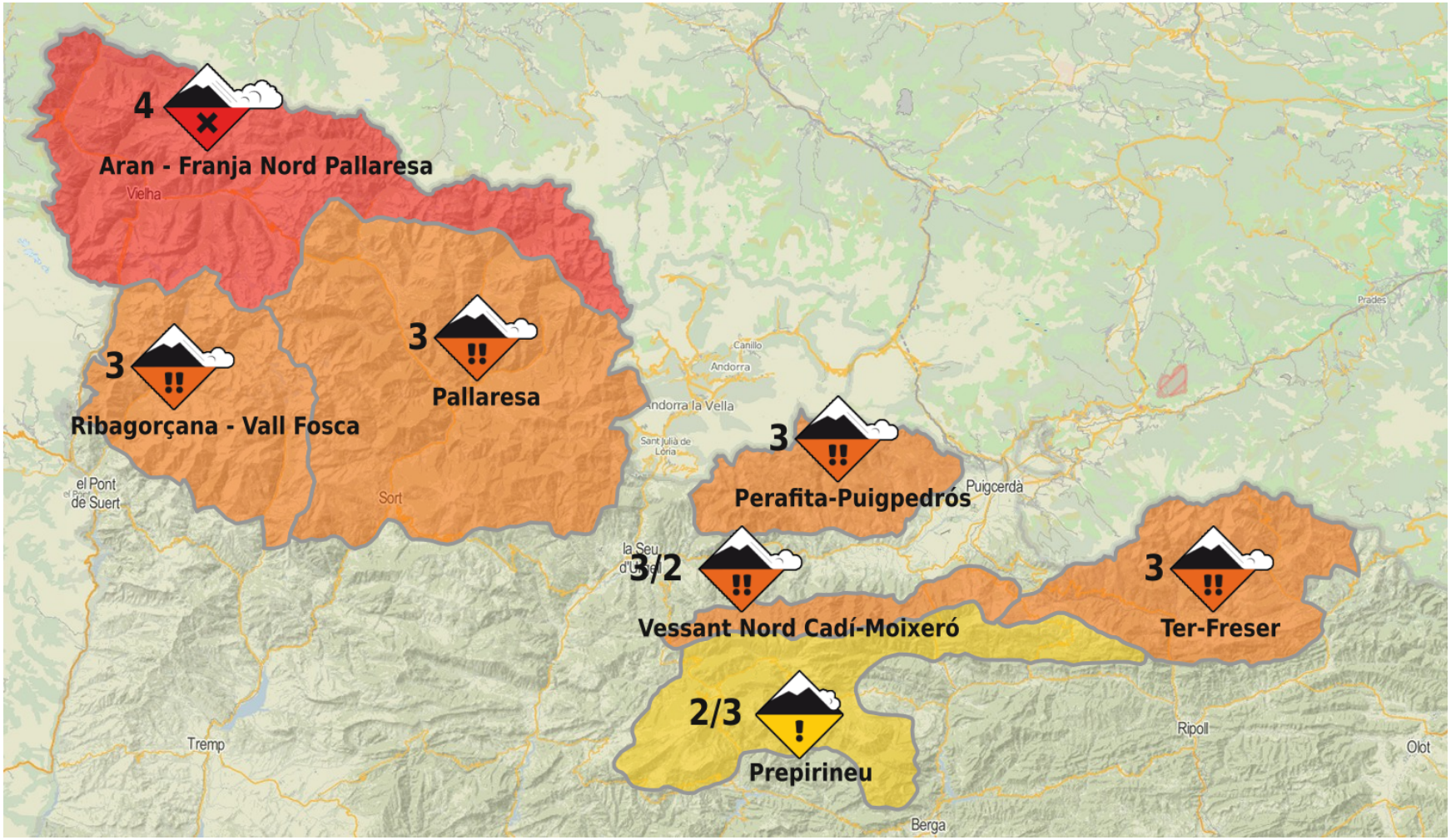

5 MUY FUERTE	4 FUERTE	3 NOTABLE	2 LIMITADO	1 DÉBIL

ICGC Institut Cartogràfic i Geològic de Catalunya

Servei Meteorològic de Catalunya

Boletín de peligro de aludes Aran - Franja Nord Pallaresa Del 14/02/2026 al 16/02/2026

(Válido fuera pistas de esquí y zonas no controladas)

FUERTE (4).

Situación primaria

Nieve venteada

Distribución

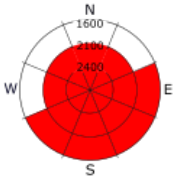

Tamaño

Origen

Tendencia

Situación secundaria

Nieve reciente

Distribución

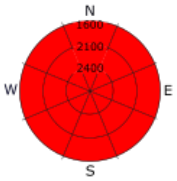

Tamaño

Origen

Tendencia

Estado del manto nivoso

La nevada acumulaba hasta 50 cm (sábado, 12h), con fuerte viento del N. En todo el episodio podrán acumularse hasta 70-80 cm. Los problemas predominantes serán las placas de viento y nieve reciente. El domingo, las placas serán muy frágiles y podrán caer de forma natural o al paso de un esquiador y generar aludes de gran tamaño (con capacidad de enterrar a un grupo de personas). Localmente, no se descarta algún alud de tamaño muy grande (que llegue a fondo de valle). Se podrán desencadenar a distancia debido a niveles débiles bajo la nieve venteada (nieve granulada y facetas). Las placas caerán a cualquier orientación, sobre todo, a S, E y N, incluso por debajo del límite del bosque. Además, se esperan también aludes de nieve reciente, en terreno con fuerte inclinación, que podrán llegar hasta tamaño medio o grande (con capacidad para enterrar a uno o más montañeros). Las condiciones serán peligrosas y se recomienda no circular por terreno avalanchoso.

Distribución del manto nivoso

Hay nieve en el suelo a 1.400 m en Norte. El manto es esquiable por encima de unos 1.500 m en umbrías. Los espesores a unos 2.200 m son superiores a los normales y rondan los 120-140 cm en el norte de Arán y los 160-200 cm en la Franja Norte Pallaresa y en el sur de Aran.

Tendencia para las próximas 48-72h

Se esperan nuevas nevadas y viento, con cota de nieve a 1800-2000m. Las placas se mantendrán reactivas y la nieve reciente se humedecerá. Peligro ESTACIONARIO.

El próximo boletín será emitido el día 2026-02-16

5 MUY FUERTE	4 FUERTE	3 NOTABLE	2 LIMITADO	1 DÉBIL

EAWS EUROPEAN AVALANCHE WARNING SERVICES

ICGC Institut Cartogràfic i Geològic de Catalunya

meteo.cat Servei Meteorològic de Catalunya

Boletín de peligro de aludes Ribagorçana - Vall Fosca Del 14/02/2026 al 16/02/2026

(Válido fuera pistas de esquí y zonas no controladas)

NOTABLE (3).

Situación primaria

Nieve venteada

Distribución

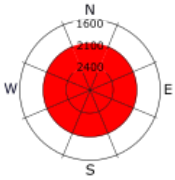

Tamaño

Origen

Tendencia

Estado del manto nivoso

La nevada con el fuerte viento del noroeste ha transportado la nieve a las laderas a sotavento. Para el domingo, el problema predominante será el de las placas de viento. Encontraremos nuevas placas, muy frágiles y podrán caer de forma natural o al paso de un esquiador y generar aludes de tamaño medio (con capacidad de enterrar a una persona). Los lugares donde se formarán serán en cualquier orientación, sobre todo, en Sur, Este y en Norte, por encima del límite del bosque, bajo collados y cordales y en terreno con convexidades. La ventisca continuará soplando a lo largo de todo el sábado y el domingo por la mañana, sobre todo en cota alta, con transporte eficiente de la nieve. Las placas de viento se mantendrán muy frágiles. En las vertientes muy inclinadas, en las zonas protegidas del viento, podrán caer purgas de nieve reciente, de pequeño tamaño y también medio. Se recomienda mucha prudencia y experiencia si debe circularse por zonas no controladas.

Distribución del manto nivoso

Hay nieve en el suelo a 1.500 m. El manto es esquiable por encima de unos 1500-1600 m. Los grosores alcanzan los 130-160 cm. Estos valores son muy superiores a los normales en la época.

Tendencia para las próximas 48-72h

Se esperan nuevas nevadas y viento, con cota de nieve a 1800-2000m. Las placas se mantendrán reactivas y la nieve reciente se humedecerá. Peligro ESTACIONARIO.

El próximo boletín será emitido el día 2026-02-16

5 MUY FUERTE	4 FUERTE	3 NOTABLE	2 LIMITADO	1 DÉBIL

EAWS EUROPEAN AVALANCHE WARNING SERVICES

ICGC Institut Cartogràfic i Geològic de Catalunya

meteo.cat Servei Meteorològic de Catalunya

Boletín de peligro de aludes Pallaresa
Del 14/02/2026 al 16/02/2026

(Válido fuera pistas de esquí y zonas no controladas)

NOTABLE (3).

Situación primaria

Nieve venteada

Distribución

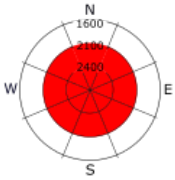

Tamaño

Origen

Tendencia

Estado del manto nivoso

La última nevada ha ido acompañada de fuerte viento del noroeste. Para el domingo, el problema predominante será el de las placas de viento. Encontraremos nuevas placas a sotavento del viento predominante, muy frágiles y podrán caer de forma natural o al paso de un esquiador y generar aludes de tamaño medio (con capacidad de enterrar a una persona). Los lugares donde se formarán serán en cualquier orientación, sobre todo, en Sur, Este y en Norte, por encima del límite del bosque, bajo collados y cordales y en terreno con convexidades. La ventisca continuará soplando a lo largo de todo el sábado y el domingo por la mañana, sobre todo en cota alta, con transporte eficiente de la nieve. Las placas de viento se mantendrán muy frágiles. En las vertientes muy inclinadas, en las zonas protegidas del viento, podrán caer purgas de nieve reciente, de pequeño tamaño y también medio. Se recomienda mucha prudencia y experiencia si debe circularse por zonas no controladas.

Distribución del manto nivoso

Hay nieve en el suelo a 1.500 m. El manto es esquiable por encima de unos 1500-1600 m. Los grosores alcanzan los 130-160 cm. Estos valores son muy superiores a los normales en la época.

Tendencia para las próximas 48-72h

Se esperan nuevas nevadas y viento, con cota de nieve a 1800-2000m. Las placas se mantendrán reactivas y la nieve reciente se humedecerá. Peligro ESTACIONARIO.

El próximo boletín será emitido el día 2026-02-16

5 MUY FUERTE	4 FUERTE	3 NOTABLE	2 LIMITADO	1 DÉBIL

EAWS EUROPEAN AVALANCHE WARNING SERVICES

ICGC Institut Cartogràfic i Geològic de Catalunya

Servei Meteorològic de Catalunya

Boletín de peligro de aludes Perafita-Puigpedrós Del 14/02/2026 al 16/02/2026

(Válido fuera pistas de esquí y zonas no controladas)

NOTABLE (3).

Situación primaria

Nieve venteada

Distribución

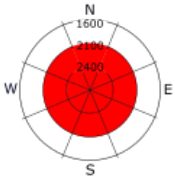

Tamaño

Origen

Tendencia

Estado del manto nivoso

La última nevada ha ido acompañada de fuerte viento del noroeste. Para el domingo, el problema predominante será el de las placas de viento. Encontraremos nuevas placas a sotavento del viento predominante, muy frágiles y podrán caer de forma natural o al paso de un esquiador y generar aludes de tamaño medio (con capacidad de enterrar a una persona). Los lugares donde se formarán serán en cualquier orientación, sobre todo, en Sur, Este y en Norte, por encima del límite del bosque, bajo collados y cordales y en terreno con convexidades. Se recomienda mucha prudencia y experiencia si debe circularse por zonas no controladas. La ventisca continuará soplando a lo largo de todo el sábado y el domingo por la mañana, sobre todo en cota alta, con transporte eficiente de la nieve. Las placas de viento se mantendrán muy frágiles.

Distribución del manto nivoso

Hay nieve en el suelo por encima de 1.400-1500 m. Sin embargo, el manto es esquiable por encima de 1.500-1.600 m. Los grosores alcanzan los 130-150 cm a 2.200 m. Son grosores muy por encima de los habituales por la época.

Tendencia para las próximas 48-72h

Se esperan nuevas nevadas y viento, con cota de nieve a 1800-2000m. Las placas se mantendrán reactivas y la nieve reciente se humedecerá. Peligro ESTACIONARIO.

El próximo boletín será emitido el día 2026-02-16

5 MUY FUERTE	4 FUERTE	3 NOTABLE	2 LIMITADO	1 DÉBIL

EAWS EUROPEAN AVALANCHE WARNING SERVICES

ICGC Institut Cartogràfic i Geològic de Catalunya

Servei Meteorològic de Catalunya

Boletín de peligro de aludes
Vessant Nord Cadí-Moixeró
Del 14/02/2026 al 16/02/2026

(Válido fuera pistas de esquí y zonas no controladas)

NOTABLE (3), por encima del límite del bosque. LIMITADO (2), en el resto.

Situación primaria

Nieve venteada

Distribución

Tamaño

Origen

Tendencia

Estado del manto nivoso

En las últimas horas ha nevado unos 10 cm (hasta la mañana del sábado) con viento moderado del Sur y posteriormente del Noroeste. En cota alta se habrán formado placas, a sotavento del viento predominante. El problema principal será, por tanto, el de las placas de viento, que las encontraremos en vertientes Este, Norte y Sur. Si se rompen las placas, al paso de un montañero, podrán generar aludes de pequeño tamaño, sin capacidad para enterrar a una persona y allí donde haya más acumulación, podrá caer algún alud de tamaño medio (que podría enterrar a un montañero), sobre todo en terreno trampa. Habrá que ir con copto en lo alto de las Canales del Cadí, donde podremos encontrar alguna nueva placa de reciente formación. Se recomienda mucha prudencia y experiencia si se debe circular por zonas no controladas, especialmente debajo de collados, cordales oa la salida de las Canales.

Distribución del manto nivoso

Hay nieve desde 1.300 m. Norte y desde 1.400 a 1500 m. Sur, esquiable por encima de unos 1.500 m. Los grosores están alrededor de 150-170 cm a 2.200 m. Estos valores son muy excedentarios para la época del año.

Tendencia para las próximas 48-72h

Se esperan nuevas nevadas y viento, con cota de nieve a 1800-2000m. Las placas se mantendrán reactivas y la nieve reciente se humedecerá. Peligro ESTACIONARIO.

El próximo boletín será emitido el día 2026-02-16

5 MUY FUERTE	4 FUERTE	3 NOTABLE	2 LIMITADO	1 DÉBIL

EAWS EUROPEAN AVALANCHE WARNING SERVICES

ICGC Institut Cartogràfic i Geològic de Catalunya

meteo.cat Servei Meteorològic de Catalunya

Boletín de peligro de aludes Prepirineu
Del 14/02/2026 al 16/02/2026

(Válido fuera pistas de esquí y zonas no controladas)

NOTABLE (3), por encima del límite del bosque. LIMITADO (2), en el resto.

Situación primaria

Nieve venteada

Distribución

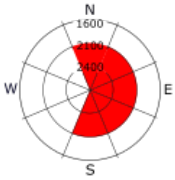

Tamaño

Origen

Tendencia

Estado del manto nivoso

En las últimas horas ha nevado (10 cm) con viento fuerte del Oeste y del Noroeste. En cota alta se han formado placas, a sotavento del viento predominante. El problema principal será, por tanto, el de las placas de viento, que las encontraremos por encima del límite del bosque, en laderas orientadas a Este, Nordeste, Sur y Sudeste. Si se rompen las placas, al paso de un montañero, podrán generar aludes de pequeño tamaño, sin capacidad para enterrar a una persona y allí donde haya más acumulación, podrá caer algún alud de tamaño medio (que podría enterrar a un montañero), sobre todo en terreno trampa. Se recomienda mucha prudencia y experiencia si debe circularse por zonas no controladas.

Distribución del manto nivoso

Hay nieve desde 1400-1500 m. El manto es esquiable a partir de 1600 m. Los grosores están alrededor de 110-130 cm a unos 2.200 my son superiores a los habituales.

Tendencia para las próximas 48-72h

Se esperan nuevas nevadas y viento, con cota de nieve a 1800-2000m. Las placas se mantendrán reactivas y la nieve reciente se humedecerá. Peligro ESTACIONARIO.

El próximo boletín será emitido el día 2026-02-16

5 MUY FUERTE	4 FUERTE	3 NOTABLE	2 LIMITADO	1 DÉBIL

EAWS EUROPEAN AVALANCHE WARNING SERVICES

ICGC Institut Cartogràfic i Geològic de Catalunya

Servei Meteorològic de Catalunya meteo.cat

Boletín de peligro de aludes Ter-Freser Del 14/02/2026 al 16/02/2026

(Válido fuera pistas de esquí y zonas no controladas)

NOTABLE (3).

Situación primaria

Nieve venteada

Distribución

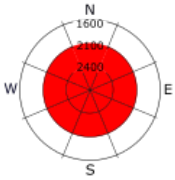

Tamaño

Origen

Tendencia

Estado del manto nivoso

El fuerte viento del noroeste ha transportado la nieve seca de la última nevada, generando nuevas placas. Para el domingo continuaremos con el problema de las placas de viento. Las encontraremos a sotavento del viento predominante del Norte y serán muy frágiles. Podrán caer de forma natural o al paso de un esquiador y generar aludes de hasta tamaño medio (con capacidad de enterrar a una persona). Los lugares donde se formarán serán en cualquier orientación, pero sobre todo, en Sur y Este, por encima del límite del bosque, bajo collados y cordales y en terreno con convexidades. Las condiciones serán delicadas, con ventisca en altura. Se recomienda mucha prudencia y experiencia si debe circularse por zonas no controladas.

Distribución del manto nivoso

El manto nivoso presenta grosores muy excedentarios para la época del año. En lugares no afectados por el viento, los espesores oscilan entre 100-140 cm a unos 2.000 m, siendo esquiable a partir de unos 1.500 m.

Tendencia para las próximas 48-72h

Se esperan nuevas nevadas y viento, con cota de nieve a 1800-2000m. Las placas se mantendrán reactivas y la nieve reciente se humedecerá. Peligro ESTACIONARIO.

El próximo boletín será emitido el día 2026-02-16

5 MUY FUERTE	4 FUERTE	3 NOTABLE	2 LIMITADO	1 DÉBIL

EAWS EUROPEAN AVALANCHE WARNING SERVICES