# BUTLLETÍ DEL PERILL D'ALLAUS DEL PRINCIPAT D'ANDORRA

Servei meteorològic nacional
Principat d'Andorra

Elaborat el 14/02/2026 16:00
Propera actualització 15/02/2026 a les 16h

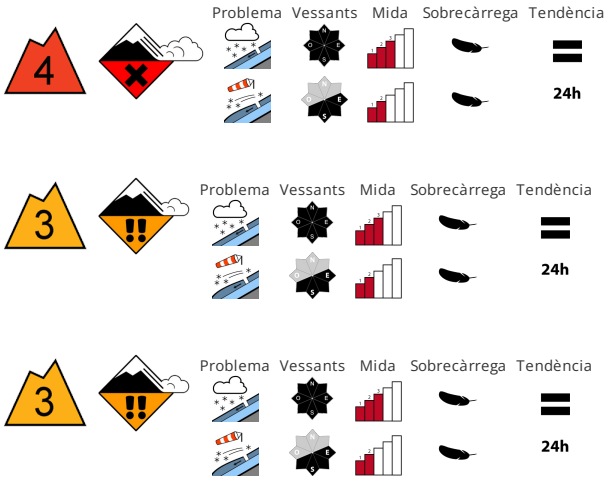


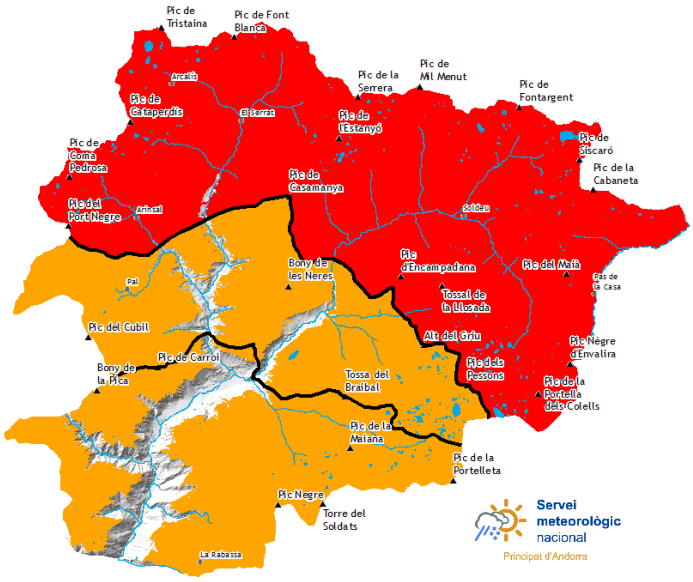


## ESTABILITAT DEL MANTELL NIVAL

La neu recent i les plaques de vent del dissabte representen la principal font de perill. El vent amb ratxes fortes transportarà intensament la neu recent. Especialment als sectors més afectats per les precipitacions són d'esperar allaus naturals de mida mitjana i, localment, gran. La neu recent i les plaques de vent poden desencadenar-se de manera natural. Alguns indrets perillosos per allaus de neu seca es troben també a l'entrada de cubetes i canals. Els indrets perillosos són i difícils de reconèixer. Les condicions són perilloses per les excursions i les activitats forapista. Es recomana una selecció acurada de la ruta i mantenir la distància entre els components.

## QUALITAT DE LA NEU

El dissabte el vent serà en molts sectors de fort a molt fort. Fins al diumenge caurà neu fins a cotes baixes sobretot als al nord. Amb la neu recent i el vent les plaques de vent augmentaran de mida. La neu recent ha de ser avaluada amb cautela. El diumenge serà suau. Amb les temperatures suaus i la radiació solar, el mantell de neu s'assentarà.

## GRUIXOS DEL MANTELL NIVAL FORA DE PISTA

| Zona nord | | Gruix neu | | |
|---|---|---|---|---|
| **Mantell Nival** | | 1500m | 2000m | 2500m |
| N | 1300 m | 50 cm | 150 cm | 200 cm |
| S | 1400 m | 30 cm | 100 cm | 150 cm |

| Zona centre | | Gruix neu | | |
|---|---|---|---|---|
| **Mantell Nival** | | 1500m | 2000m | 2500m |
| N | 1300 m | 30 cm | 150 cm | 200 cm |
| S | 1400 m | 10 cm | 100 cm | 150 cm |

| Zona sud | | Gruix neu | | |
|---|---|---|---|---|
| **Mantell Nival** | | 1500m | 2000m | 2500m |
| N | 1300 m | 30 cm | 120 cm | 150 cm |
| S | 1400 m | 10 cm | 60 cm | 100 cm |

Govern d'Andorra

EAWS EUROPEAN AVALANCHE WARNING SERVICES

Aquest butlletí ha estat elaborat seguint les normes i recomanacions de l'**European Avalanche Warning Services**, del qual el **Servei meteorològic Nacional** n'és membre

## Informació detallada per espais naturals protegits

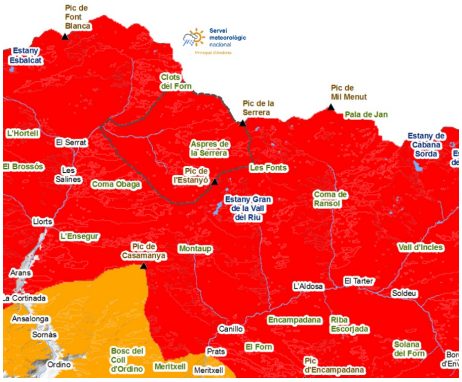


### SORTENY

Les nevades del dissabte seran conseqüents i poden deixar gruixos de neu nova superiors als 50 cm, modelats pel vent. Les activitats fora de les pistes controlades requereixen experiència i molta cura en l´elecció del territori.

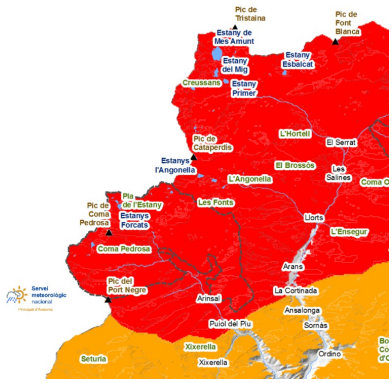


### COMAPEDROSA

Com en tot el territori, les activitats a la muntanya són desaconsellables fins que la neu recent s´hagi estabilitzat. S´esperen nombroses allaus naturals.

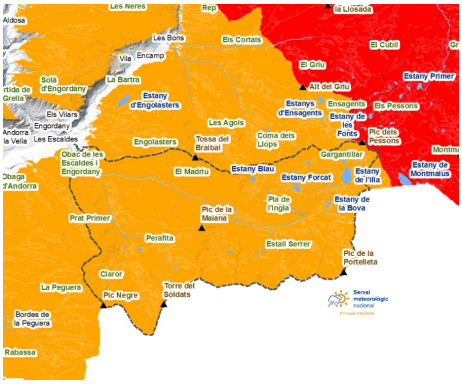


### MADRIU-PERAFITA-CLAROR

A la part alta del Madriu també hi ha nevat, tot i que les nevades al sud del país han estat menys intenses, també esperem la formació de plaques de vent. La neu recent s´assentarà sobre una neu més dura en les cotes baixes.

# BUTLLETÍ DEL PERILL D'ALLAUS DEL PRINCIPAT D'ANDORRA

Servei meteorològic nacional
Principat d'Andorra

## Gruixos de neu nova dels darrers dies (de les últimes 24h mesurat a les 06:00h UTC)

| | 10/02/2026 | 11/02/2026 | 12/02/2026 | 13/02/2026 |
|---|---|---|---|---|
| **FEDA (Central)** | 0 cm | 0 cm | 0 cm | 0 cm |
| **Engolasters - FEDA** | 0 cm | 0 cm | 0 cm | 10 cm |
| **Bony de les Neres** | 0 cm | 0 cm | 0 cm | 14 cm |
| **Sorteny** | 0 cm | 17 cm | 0 cm | 36 cm |
| **Les Fonts d'Arinsal** | 12 cm | 9 cm | 0 cm | 18 cm |
| **Perafita** | 0 cm | 0 cm | 0 cm | 0 cm |
| **Tossa Espiolets** | 0 cm | 0 cm | 0 cm | 8 cm |
| **Grau Roig - FEDA** | 0 cm | 9 cm | 0 cm | 10 cm |
| **Fontverd** | 0 cm | 0 cm | 0 cm | 8 cm |
| **Ransol - FEDA** | 0 cm | 0 cm | 0 cm | 13 cm |
| **Setúria** | 0 cm | 0 cm | 0 cm | 8 cm |
| **Caborreu** | 0 cm | 9 cm | 0 cm | 8 cm |
| **Envalira Antenes** | 0 cm | 0 cm | 0 cm | 6 cm |
| **Vall del Riu FEDA** | 7 cm | 0 cm | 1 cm | 7 cm |