BUTLLETÍ DEL PERILL D'ALLAUS DEL PRINCIPAT D'ANDORRA

Elaborado el 14/02/2026 16:00
Proxima actualización 15/02/2026 a las 16h

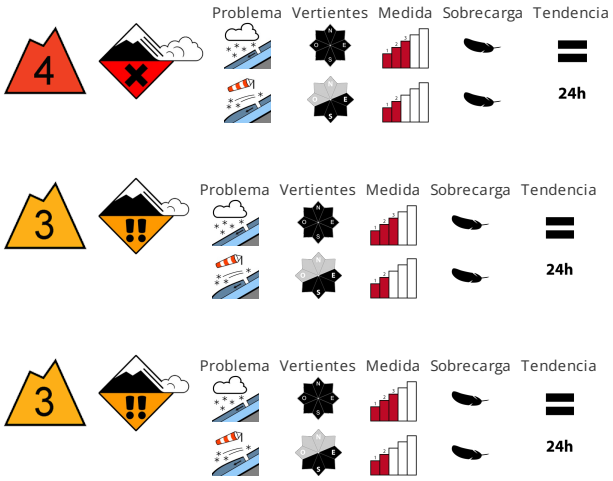

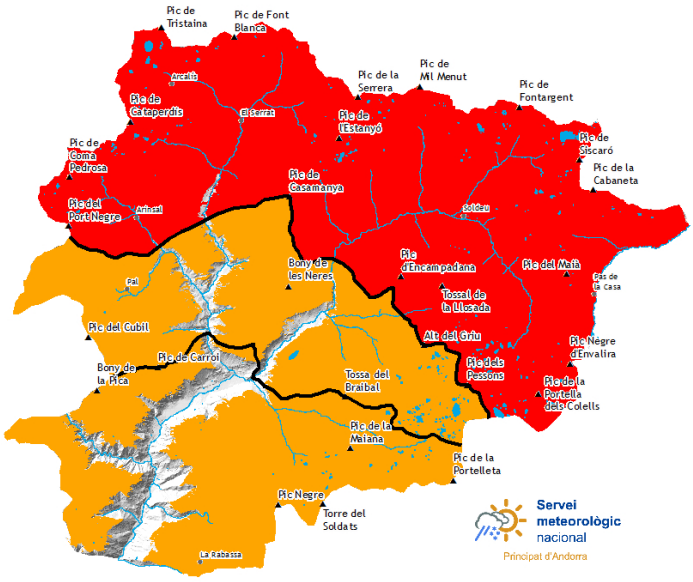

CALIDAD DE LA NIEVE

La nieve reciente y la nieve venteada del sábado representan la principal fuente de peligro. El viento con rachas fuertes transportará intensamente la nieve reciente. Especialmente en los sectores más afectados por las precipitaciones son son probables aludes naturales de tamaño mediano y, locamente, grande. La nieve reciente y las placas de viento pueden desencadenarse de manera natural. Algunos lugares peligrosos por aludes de nieve seca se encuentran también en la entrada de cubetas y canales. Los lugares peligrosos son y resultan difíciles de reconocer. Las condiciones son peligrosas para las excursiones y las actividades fuera pista. Se recomienda una elección cuidadosa de la ruta y mantener la distancia de seguridad entre los miembros del grupo.

ESTABILIDAD DEL MANTO NIVOSO

El sábado el viento soplará en muchos sectores de fuerte a muy fuerte. Hasta el domingo caerá nieve hasta cotas bajas sobre todo en los norte. Con la nieve reciente y el viento las placas de viento aumentarán de tamaño. La nieve reciente debe ser evaluada con cautela. El domingo será suave. Con las temperaturas suaves y la radiación solar, el manto de nieve se asentará.

ESPESORES DEL MANTO NIVOSO FUERA DE PISTA

Zona norte		Espesor nieve		
Manto Nival		1500m	2000m	2500m
N	1300 m	50 cm	150 cm	200 cm
S	1400 m	30 cm	100 cm	150 cm

zona centro		Espesor nieve		
Manto Nival		1500m	2000m	2500m
N	1300 m	30 cm	150 cm	200 cm
S	1400 m	10 cm	100 cm	150 cm

Zona sur		Espesor nieve		
Manto Nival		1500m	2000m	2500m
N	1300 m	30 cm	120 cm	150 cm
S	1400 m	10 cm	60 cm	100 cm

Govern d'Andorra

EAWS EUROPEAN AVALANCHE WARNING SERVICES

Aquest butlletí ha estat elaborat seguint les normes i recomanacions de l'**European Avalanche Warning Services**, del qual el **Servei meteorològic Nacional** n'és membre

BUTLLETÍ DEL PERILL D'ALLAUS DEL PRINCIPAT D'ANDORRA

Servei meteorològic nacional
Principat d'Andorra

Información detallada por espacios naturales protegidos

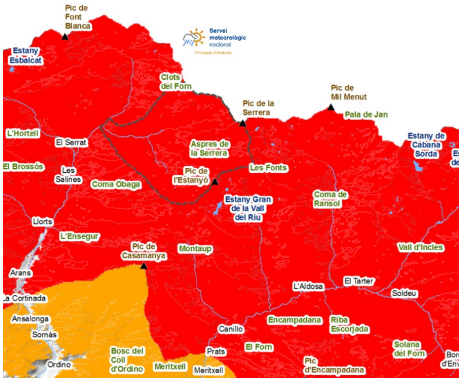

SORTENY

Las nevadas del sábado serán consecuentes y pueden dejar espesores de nieve nueva superiores a los 50 cm, moldeados por el viento. Las actividades fuera de las pistas controladas requieren experiencia y mucho cuidado en la elección del territorio.

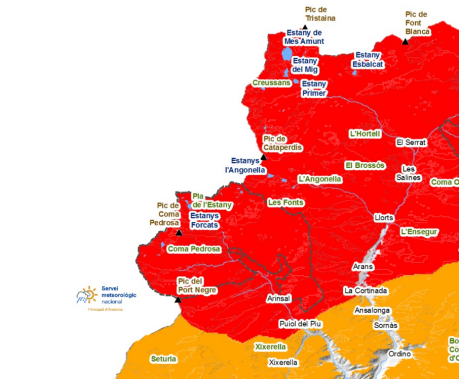

COMAPEDROSA

Como en todo el territorio, las actividades en la montaña son desaconsejables hasta que la reciente nieve se haya estabilizado. Se esperan numerosos aludes naturales.

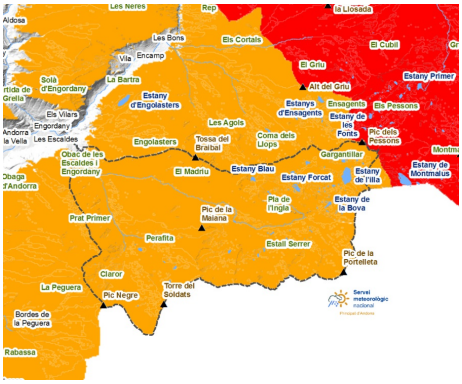

MADRIU-PERAFITA-CLAROR

En la parte alta del Madriu también ha nevado, aunque las nevadas en el sur del país han sido menos intensas, también esperamos la formación de placas de viento. La nieve reciente se asentará sobre una nieve más dura en las cotas bajas.

Govern d'Andorra

EAWS
EUROPEAN AVALANCHE WARNING SERVICES

Aquest butlletí ha estat elaborat seguint les normes i recomanacions de l'**European Avalanche Warning Services**, del qual el **Servei meteorològic Nacional** n'és membre

BUTLLETÍ DEL PERILL D'ALLAUS DEL PRINCIPAT D'ANDORRA

Servei meteorològic nacional
Principat d'Andorra

Espesores de nieve nueva de los últimos días (de las ultimas 24h mesurado a las 06:00h UTC)

	10/02/2026	11/02/2026	12/02/2026	13/02/2026
FEDA (Central)	0 cm	0 cm	0 cm	0 cm
Engolasters - FEDA	0 cm	0 cm	0 cm	10 cm
Bony de les Neres	0 cm	0 cm	0 cm	14 cm
Sorteny	0 cm	17 cm	0 cm	36 cm
Les Fonts d'Arinsal	12 cm	9 cm	0 cm	18 cm
Perafita	0 cm	0 cm	0 cm	0 cm
Tossa Espiolets	0 cm	0 cm	0 cm	8 cm
Grau Roig - FEDA	0 cm	9 cm	0 cm	10 cm
Fontverd	0 cm	0 cm	0 cm	8 cm
Ransol - FEDA	0 cm	0 cm	0 cm	13 cm
Setúria	0 cm	0 cm	0 cm	8 cm
Caborreu	0 cm	9 cm	0 cm	8 cm
Envalira Antenes	0 cm	0 cm	0 cm	6 cm
Vall del Riu FEDA	7 cm	0 cm	1 cm	7 cm