BUTLLETÍ DEL PERILL D'ALLAUS DEL PRINCIPAT D'ANDORRA

Servei meteorològic nacional
Principat d'Andorra

Préparé le 14/02/2026 16:01
Prochaine mise à jour le 15/02/2026 à 16h

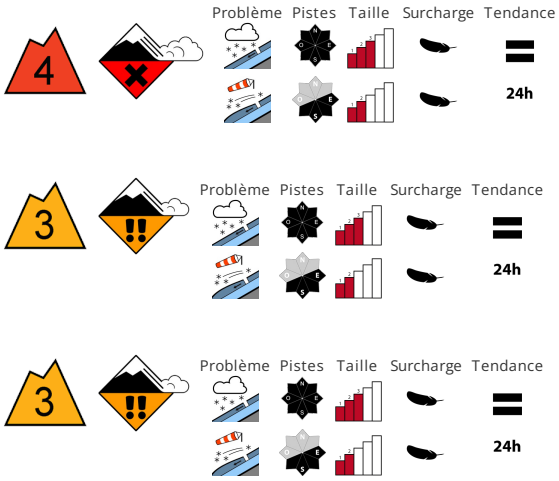

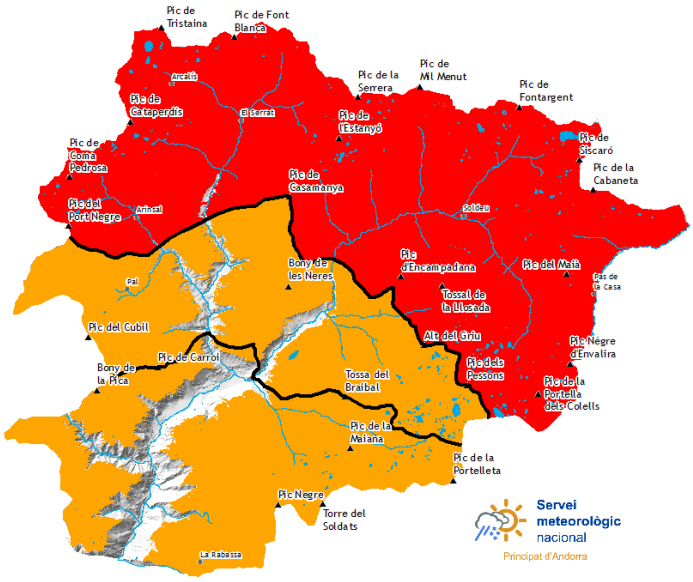

STABILITÉ DU MANTEAU NEIGEUX

La neige fraîche et la neige soufflée de samedi constituent le danger principal. Le vent parfois fort transporte intensivement la neige fraîche.. Des avalanches spontanées de moyenne et rarement grande taille sont à attendre spécialement dans les régions concernées par les précipitations principales. La neige fraîche et les accumulations de neige soufflée peuvent glisser spontanément. Quelques endroits dangereux pour les avalanches sèches se situent aussi aux transitions vers les combes et couloirs. Les endroits dangereux sont et difficilement identifiables.. Pour des randonnées et descentes hors-piste les conditions sont dangereuses. Un choix prudent d'itinéraire et des distances de délestage sont recommandés..

QUALITÈ DE LA NEIGE

Samedi le vent souffle en général fortement à tempétueusement. Jusqu'à dimanche il tombera de la neige jusqu'à basse altitude surtout au nord. Les accumulations de neige soufflée se développent avec la neige fraîche et le vent. La neige fraîche doit être évaluée avec précaution. Dimanche il fait doux. Avec les températures douces et le rayonnement solaire le manteau neigeux se tasse.

EPAISSEUR DE NEIGE HORS PISTE

Zone nord		Epaisseur de neige			Zone centre		Epaisseur de neige			Zone sud		Epaisseur de neige		
Nival manteau		1500m	2000m	2500m	**Nival manteau**		1500m	2000m	2500m	**Nival manteau**		1500m	2000m	2500m
N	1300 m	50 cm	150 cm	200 cm	N	1300 m	30 cm	150 cm	200 cm	N	1300 m	30 cm	120 cm	150 cm
S	1400 m	30 cm	100 cm	150 cm	S	1400 m	10 cm	100 cm	150 cm	S	1400 m	10 cm	60 cm	100 cm

Govern d'Andorra

EAWS EUROPEAN AVALANCHE WARNING SERVICES

Aquest butlletí ha estat elaborat seguint les normes i recomanacions de l'**European Avalanche Warning Services**, del qual el **Servei meteorològic Nacional** n'és membre

BUTLLETÍ DEL PERILL D'ALLAUS DEL PRINCIPAT D'ANDORRA

Servei meteorològic nacional
Principat d'Andorra

Des informations détaillées par espace naturel protégé

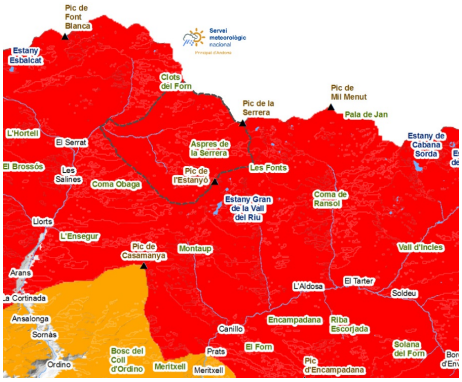

SORTENY

Les chutes de neige de samedi seront conséquentes et pourraient laisser des épaisseurs de neige fraîche supérieures à 50 cm, façonnées par le vent. Les activités hors pistes contrôlées nécessitent de l'expérience et un grand soin dans le choix du territoire. , , ,

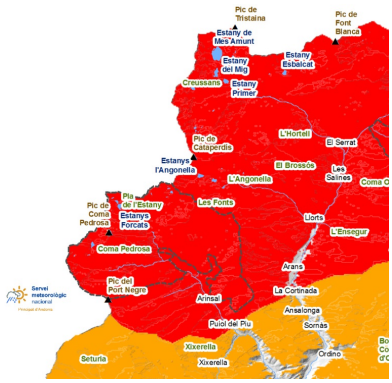

COMAPEDROSA

Comme sur l'ensemble du territoire, les activités de montagne sont déconseillées tant que la neige récente n'est pas stabilisée. De nombreuses avalanches naturelles sont attendues. , , ,

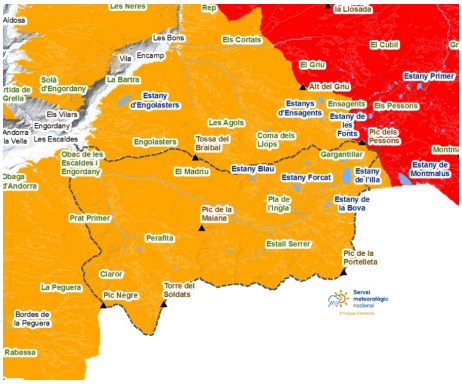

MADRIU-PERAFITA-CLAROR

Il y a aussi de la neige dans la partie supérieure du Madriu, même si les chutes de neige dans le sud du pays ont été moins intenses, on s'attend également à la formation de plaques de vent. La neige récente se déposera sur la neige plus dure à basse altitude. , , ,

BUTLLETÍ DEL PERILL D'ALLAUS DEL PRINCIPAT D'ANDORRA

Servei meteorològic nacional
Principat d'Andorra

Couche de neige fraiche des derniers jours (De 24 h mesurée à 06:00 h UTC)

	10/02/2026	11/02/2026	12/02/2026	13/02/2026
FEDA (Central)	0 cm	0 cm	0 cm	0 cm
Engolasters - FEDA	0 cm	0 cm	0 cm	10 cm
Bony de les Neres	0 cm	0 cm	0 cm	14 cm
Sorteny	0 cm	17 cm	0 cm	36 cm
Les Fonts d'Arinsal	12 cm	9 cm	0 cm	18 cm
Perafita	0 cm	0 cm	0 cm	0 cm
Tossa Espiolets	0 cm	0 cm	0 cm	8 cm
Grau Roig - FEDA	0 cm	9 cm	0 cm	10 cm
Fontverd	0 cm	0 cm	0 cm	8 cm
Ransol - FEDA	0 cm	0 cm	0 cm	13 cm
Setúria	0 cm	0 cm	0 cm	8 cm
Caborreu	0 cm	9 cm	0 cm	8 cm
Envalira Antenes	0 cm	0 cm	0 cm	6 cm
Vall del Riu FEDA	7 cm	0 cm	1 cm	7 cm