MINISTERO DELLA DIFESA

meteomont Servizio Nazionale di previsione neve e valanghe

EAWS EUROPEAN AVALANCHE WARNING SERVICES

CARABINIERI

In collaborazione con: arpav

DOLOMITI SETTENTRIONALI

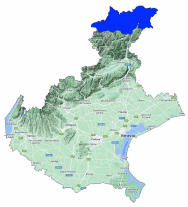

Bollettino Valanghe N. 344/2026 del 13/02/2026 ore 14.00
Validità 48 ore prossima emissione 14/02/2026

A cura del Servizio METEOMONT dell'ARMA dei CARABINIERI
In collaborazione con Servizio Meteorologico dell'Aeronautica militare

SITUAZIONE alle 14:00 del 13/02/2026

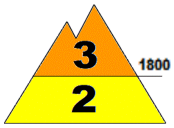

SITUAZIONE TIPO: nessuna situazione tipo evidente.



SITUAZIONE TIPO: situazione primaverile.

Quota neve (mslm)	Nord	Sud
	1000 - 1200	1500

Altezza Neve (cm)	Neve al suolo	Neve Fresca	Quota (mslm)
	46	03	2388
	78	00	2241

VALANGHE OSSERVATE: Nessuna valanga.

PREVISIONI 14/02/2026

GRADO DI PERICOLO: MARCATO 3

SITUAZIONE TIPO: nessuna situazione tipo evidente.

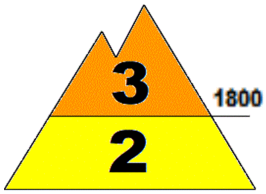

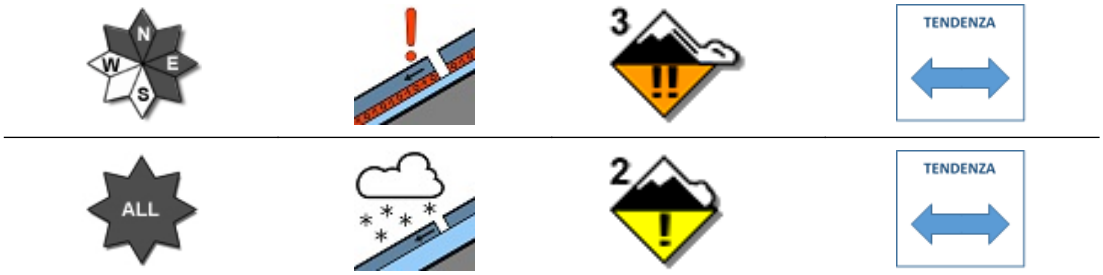

SITUAZIONE TIPO: neve a debole coesione e vento.

MANTO NEVOSO: La stabilità del manto nevoso è scarsa su molti punti (aree) per versanti da nord ovest a sud est compresi al di sopra di 1800 mslm, possibili valanghe di dimensioni medie.
La stabilità del manto nevoso è scarsa su alcuni punti (aree) per tutte le esposizioni al di sotto di 1800 mslm, possibili valanghe di dimensioni medie.

AVVERTENZE

A seguito dell'attività eolica registrata sono da evitare le zone di accumulo, conche, canaloni, cambi di pendenza e pendii sotto vento in genere.

SCALA EUROPEA DEL GRADO DI PERICOLO VALANGHE

LEGENDA PROBLEMA

Bollettino realizzato su scala sinottica-regionale (standard EAWS). La sua valutazione non può escludere in alcun modo la necessità di una seria e capace valutazione locale del pericolo (singolo pendio) che può essere anche sensibilmente diverso. Le previsioni meteorologiche sono relative all'orario UTC (per l'Italia +1 in inverno e +2 in estate).

DOLOMITI SETTENTRIONALI

PREVISIONE METEO

Quota		14/02/2026 h6:00	14/02/2026 h12:00	14/02/2026 h18:00
1000	Venti	02 Nodi da Est	01 Nodi da Est	01 Nodi da Nord
	Temperature	-04 °C	-01 °C	-01 °C
	Temp.percepita	-4 °C	-1 °C	-1 °C
2000	Venti	03 Nodi da Est	03 Nodi da Est	03 Nodi da Nord
	Temperature	-04 °C	-02 °C	-02 °C
	Temp.percepita	-6 °C	-4 °C	-4 °C
3000	Venti	12 Nodi da Sud	07 Nodi da S-Est	04 Nodi da N-Est
	Temperature	-09 °C	-09 °C	-08 °C
	Temp.percepita	-17 °C	-15 °C	-12 °C
Zero termico		1000-1200 m.	1700-1900 m.	1600-1800 m.
Fenomeno				
Stato del cielo				

LEGENDA FENOMENI

Assenza Fenomeni · Nebbia · Foschia · Pioggia debole · Pioggia moderata · Pioggia forte · Temporali

Nevicata debole · Nevicata moderata · Nevicata forte

STATO DEL CIELO

Sereno · Poco nuvoloso · Nuvoloso · Molto nuvoloso · Coperto

Parametri meteonivometrici registrati presso i campi di rilevamento il 13/02/2026.

Località	Comune	Quota (m.s.l.m.)	Altezza neve (cm)	Neve caduta nelle 24 ore (cm)	Temp. Min (°C)	Temp. Max (°C)	Condizioni del tempo
MISURINA	Auronzo di Cadore (BL)	1759	59	0	-9	+14	Assenza di precipitazioni
MONTE AGUDO	Auronzo di Cadore (BL)	1530	62	0	-4	+3	Assenza di precipitazioni
MONTE FALORIA	Cortina d'Ampezzo (BL)	2119	74	0	-5	+11	Assenza di precipitazioni
COL DELLA TENDA	Comelico Superiore (BL)	1930	83	0	-4	+8	Assenza di precipitazioni
COL DE VARDA *	Auronzo di Cadore (BL)	2241	78	0	N.P.	N.P.	Assenza di precipitazioni
CRODA NEGRA *	Cortina d'Ampezzo (BL)	2388	46	3	N.P.	N.P.	Assenza di precipitazioni

(*) Rilievi fuori campo

L'INFORMAZIONE E' PREVENZIONE - LEGGI L'ATTUALE GRADO DI PERICOLO VALANGHE!

IL CAPO DEL CENTRO NAZIONALE METEOMONT
(Ten. Col. RFI Emanuela Gini)
FIRMA AUTOGRAFA OMESSA AI SENSI
DELL'ART.3 DEL D.LGS N.39/1993

Bollettino realizzato su scala sinottica-regionale (standard EAWS). La sua valutazione non può escludere in alcun modo la necessità di una seria e capace valutazione locale del pericolo (singolo pendio) che può essere anche sensibilmente diverso. Le previsioni meteorologiche sono relative all'orario UTC (per l'Italia +1 in inverno e +2 in estate).