MINISTERO DELLA DIFESA

meteomont
Servizio Nazionale di previsione neve e valanghe

EAWS EUROPEAN AVALANCHE WARNING SERVICES

CARABINIERI

AERONAUTICA MILITARE SERVIZIO METEOROLOGICO

ALPI OROBICHE

Bollettino Valanghe N. 345/2026 del 14/02/2026 ore 14.00
Validità 48 ore prossima emissione 15/02/2026

A cura del Servizio METEOMONT dell'ARMA dei CARABINIERI
In collaborazione con Servizio Meteorologico dell'Aeronautica militare

SITUAZIONE alle 14:00 del 14/02/2026

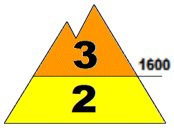

SITUAZIONE TIPO: strato debole persistente basale.



SITUAZIONE TIPO: pioggia su neve.

Quota neve (mslm)	Nord	Sud
	1200	1200 - 1600

Altezza Neve (cm)	Neve al suolo	Neve Fresca	Quota (mslm)
	125	9	2080
	040	5	1350

VALANGHE OSSERVATE: Nessuna valanga.

PREVISIONI 15/02/2026

GRADO DI PERICOLO: MARCATO 3

SITUAZIONE TIPO: strato debole persistente basale.

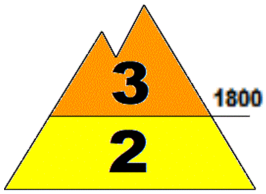



SITUAZIONE TIPO: situazione primaverile.

MANTO NEVOSO: La stabilità del manto nevoso è scarsa su alcuni punti (aree) per tutte le esposizioni al di sopra di 1800 mslm, possibili valanghe di dimensioni medie.
La stabilità del manto nevoso è molto scarsa su alcuni punti (aree) per versanti da ovest a est al di sotto di 1800 mslm, possibili valanghe di dimensioni piccole.

AVVERTENZE

A seguito dell'attività eolica prevista sono da evitare le zone di accumulo, conche, canaloni, cambi di pendenza e pendii sotto vento in genere.

SCALA EUROPEA DEL GRADO DI PERICOLO VALANGHE

LEGENDA PROBLEMA

Bollettino realizzato su scala sinottica-regionale (standard EAWS). La sua valutazione non può escludere in alcun modo la necessità di una seria e capace valutazione locale del pericolo (singolo pendio) che può essere anche sensibilmente diverso. Le previsioni meteorologiche sono relative all'orario UTC (per l'Italia +1 in inverno e +2 in estate).

ALPI OROBICHE

PREVISIONE METEO

Quota		15/02/2026 h6:00	15/02/2026 h12:00	15/02/2026 h18:00
1000	Venti	05 Nodi da Nord	03 Nodi da Nord	01 Nodi da Ovest
	Temperature	-03 °C	-03 °C	-02 °C
	Temp.percepita	-7 °C	-5 °C	-2 °C
2000	Venti	09 Nodi da Nord	05 Nodi da Nord	02 Nodi da S-Ovest
	Temperature	-04 °C	-03 °C	-04 °C
	Temp.percepita	-10 °C	-7 °C	-4 °C
3000	Venti	05 nodi da N-Ovest	04 nodi da N-Ovest	07 nodi da Ovest
	Temperature	-07 °C	-07 °C	-08 °C
	Temp.percepita	-11 °C	-11 °C	-14 °C
Zero termico		1100-1300 m.	1300-1500 m.	1200-1400 m.
Fenomeno		—	—	—
Stato del cielo				

LEGENDA FENOMENI

— Assenza Fenomeni · Nebbia · Foschia · Pioggia debole · Pioggia moderata · Pioggia forte · Temporali

Nevicata debole · Nevicata moderata · Nevicata forte

STATO DEL CIELO

Sereno · Poco nuvoloso · Nuvoloso · Molto nuvoloso · Coperto

Parametri meteonivometrici registrati presso i campi di rilevamento il 14/02/2026.

Località	Comune	Quota (m.s.l.m.)	Altezza neve (cm)	Neve caduta nelle 24 ore (cm)	Temp. Min (°C)	Temp. Max (°C)	Condizioni del tempo
QUARTA BAITA	Foppolo (BG)	1760	65	2	-1	+8	Assenza di precipitazioni
CIMA BIANCA	Colere (BG)	2080	125	9	-4	+2	Nevicata debole continua
LIZZOLA *	Valbondione (BG)	1341	40	5	N.P.	N.P.	Nevicata debole intermittente

(*) Rilievi fuori campo

L'INFORMAZIONE E' PREVENZIONE - LEGGI L'ATTUALE GRADO DI PERICOLO VALANGHE!

IL CAPO DEL CENTRO NAZIONALE METEOMONT
(Ten. Col. RFI Emanuela Gini)
FIRMA AUTOGRAFA OMESSA AI SENSI
DELL'ART.3 DEL D.LGS N.39/1993