MINISTERO DELLA DIFESA

meteomont Servizio Nazionale di previsione neve e valanghe

EAWS EUROPEAN AVALANCHE WARNING SERVICES

CARABINIERI

# PREALPI LOMBARDE

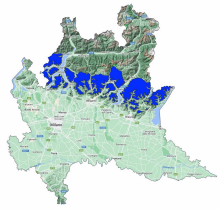

Bollettino Valanghe N. 344/2026 del 14/02/2026 ore 14.00
Validità 48 ore prossima emissione 15/02/2026

**A cura del Servizio METEOMONT dell'ARMA dei CARABINIERI**
**In collaborazione con Servizio Meteorologico dell'Aeronautica militare**

## SITUAZIONE alle 14:00 del 14/02/2026

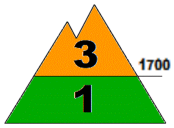


**SITUAZIONE TIPO: strato debole persistente basale.**




**SITUAZIONE TIPO: pioggia su neve.**

| | Nord | Sud |
|---|---|---|
| *Quota neve (mslm)* | *1100 - 1500* | *1400 - 1500* |

| | Neve al suolo | Neve Fresca | Quota (mslm) |
|---|---|---|---|
| *Altezza Neve (cm)* | *45* | *5* | *1750* |
| | *15* | *0* | *1156* |

**VALANGHE OSSERVATE: Nessuna valanga.**

## PREVISIONI 15/02/2026

## GRADO DI PERICOLO: MARCATO 3

### SITUAZIONE TIPO: strato debole persistente basale.

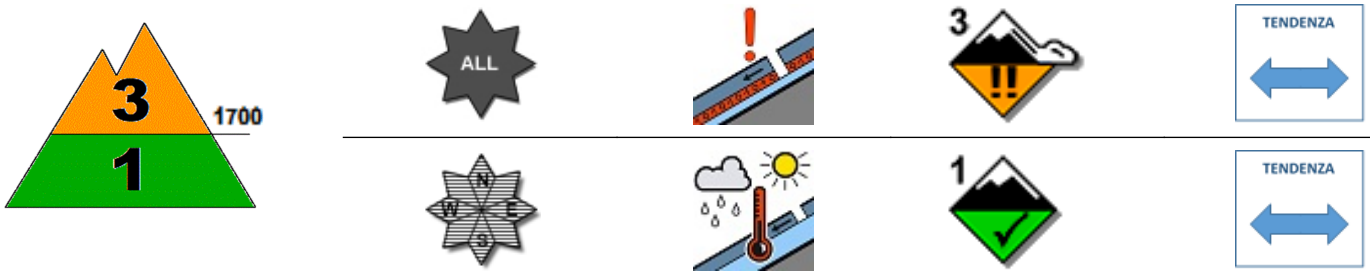


### SITUAZIONE TIPO: situazione primaverile.

**MANTO NEVOSO: La stabilità del manto nevoso è scarsa su alcuni punti (aree) per tutte le esposizioni al di sopra di 1700 mslm, possibili valanghe di dimensioni medie.**
**La stabilità del manto nevoso è molto scarsa su pochi punti (aree) per isolati pendii al di sotto di 1700 mslm, possibili valanghe di dimensioni piccole.**

## AVVERTENZE

A seguito dell'attività eolica prevista sono da evitare le zone di accumulo, conche, canaloni, cambi di pendenza e pendii sotto vento in genere.

## SCALA EUROPEA DEL GRADO DI PERICOLO VALANGHE

5 - MOLTO FORTE | 4 - FORTE | 3 - MARCATO | 2 - MODERATO | 1 - DEBOLE | NO NEVE | NO NEVE | NO INFO

## LEGENDA PROBLEMA

NEVE FRESCA | LASTRONI DA VENTO | STRATI DEBOLI PERSISTENTI | NEVE BAGNATA | SLITTAMENTO | CORNICI | NESSUN PROBLEMA VALANGHIVO EVIDENTE | NO_INFO

**Bollettino realizzato su scala sinottica-regionale (standard EAWS). La sua valutazione non può escludere in alcun modo la necessità di una seria e capace valutazione locale del pericolo (singolo pendio) che può essere anche sensibilmente diverso. Le previsioni meteorologiche sono relative all'orario UTC (per l'Italia +1 in inverno e +2 in estate).**

# PREALPI LOMBARDE

## PREVISIONE METEO

| Quota | | 15/02/2026 h6:00 | 15/02/2026 h12:00 | 15/02/2026 h18:00 |
|---|---|---|---|---|
| 1000 | Venti | 04 Nodi da Nord | 02 Nodi da Nord | 01 Nodi da S-Ovest |
| | Temperature | -03 °C | -02 °C | -02 °C |
| | Temp.percepita | -6 °C | -2 °C | -2 °C |
| 2000 | Venti | 08 Nodi da Nord | 03 Nodi da Nord | 01 Nodi da S-Ovest |
| | Temperature | -03 °C | -02 °C | -03 °C |
| | Temp.percepita | -8 °C | -4 °C | -3 °C |
| 3000 | Venti | 00 Calma | 07 Nodi da Nord | 11 nodi da Ovest |
| | Temperature | -09 °C | -07 °C | -08 °C |
| | Temp.percepita | -9 °C | -13 °C | -15 °C |
| Zero termico | | 1100-1300 m. | 1300-1500 m. | 1200-1400 m. |
| Fenomeno | | — | — | — |
| Stato del cielo | | | | |

## LEGENDA FENOMENI

— Assenza Fenomeni · Nebbia · Foschia · Pioggia debole · Pioggia moderata · Pioggia forte · Temporali

Nevicata debole · Nevicata moderata · Nevicata forte

## STATO DEL CIELO

Sereno · Poco nuvoloso · Nuvoloso · Molto nuvoloso · Coperto

## Parametri meteonivometrici registrati presso i campi di rilevamento il 14/02/2026.

| Località | Comune | Quota (m.s.l.m.) | Altezza neve (cm) | Neve caduta nelle 24 ore (cm) | Temp. Min (°C) | Temp. Max (°C) | Condizioni del tempo |
|---|---|---|---|---|---|---|---|
| RIFUGIO BRUNO | Alta Valle Intelvi (CO) | 1156 | 15 | 0 | +2 | +13 | Pioggia mista a neve |
| PIANI DI BOBBIO | Barzio (LC) | 1724 | 67 | 6 | -1 | +3 | Nevicata debole continua |
| PASSO MANIVA | Collio (BS) | 1751 | 45 | 5 | -3 | +6 | Nevicata debole continua |

**(*) Rilievi fuori campo**

**L'INFORMAZIONE E' PREVENZIONE - LEGGI L'ATTUALE GRADO DI PERICOLO VALANGHE!**

**IL CAPO DEL CENTRO NAZIONALE METEOMONT**
**(Ten. Col. RFI Emanuela Gini)**
**FIRMA AUTOGRAFA OMESSA AI SENSI**
**DELL'ART.3 DEL D.LGS N.39/1993**

**Bollettino realizzato su scala sinottica-regionale (standard EAWS). La sua valutazione non può escludere in alcun modo la necessità di una seria e capace valutazione locale del pericolo (singolo pendio) che può essere anche sensibilmente diverso. Le previsioni meteorologiche sono relative all'orario UTC (per l'Italia +1 in inverno e +2 in estate).**