TERMINILLO MONTI REATINI E LAGA OVEST

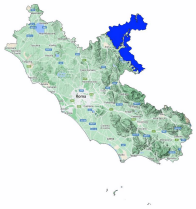

Bollettino Valanghe N. 286/2026 del 13/02/2026 ore 14.00
Validità 48 ore prossima emissione 14/02/2026

A cura del Servizio METEOMONT dell'ARMA dei CARABINIERI
In collaborazione con Servizio Meteorologico dell'Aeronautica militare

SITUAZIONE alle 14:00 del 13/02/2026

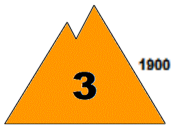

SITUAZIONE TIPO: neve pallottolare sepolta.

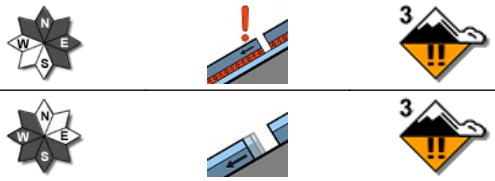

SITUAZIONE TIPO: neve da slittamento.

Quota neve (mslm)	Nord	Sud
	1500	1600

Altezza Neve (cm)	Neve al suolo	Neve Fresca	Quota (mslm)
	059	000	1770
	059	000	1770

VALANGHE OSSERVATE: Alcune valanghe di medie dimensioni, Valanghe di slittamento.

PREVISIONI 14/02/2026

GRADO DI PERICOLO: MARCATO 3

SITUAZIONE TIPO: neve pallottolare sepolta.

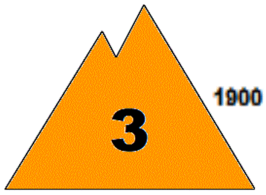



SITUAZIONE TIPO: pioggia su neve.

MANTO NEVOSO: La stabilità del manto nevoso è scarsa su molti punti (aree) per versanti da nord ovest a sud est compresi al di sopra di 1900 mslm, possibili valanghe di dimensioni medie.
La stabilità del manto nevoso è molto scarsa su molti punti (aree) per tutte le esposizioni al di sotto di 1900 mslm, possibili valanghe di dimensioni medie.

AVVERTENZE

Viste le condizioni del manto nevoso, le attività al di fuori delle piste battute e segnalate richiedono ottime capacità di valutazione del pericolo locale.

SCALA EUROPEA DEL GRADO DI PERICOLO VALANGHE

LEGENDA PROBLEMA

Bollettino realizzato su scala sinottica-regionale (standard EAWS). La sua valutazione non può escludere in alcun modo la necessità di una seria e capace valutazione locale del pericolo (singolo pendio) che può essere anche sensibilmente diverso. Le previsioni meteorologiche sono relative all'orario UTC (per l'Italia +1 in inverno e +2 in estate).

MINISTERO DELLA DIFESA

meteomont
Servizio Nazionale di previsione neve e valanghe

EAWS EUROPEAN AVALANCHE WARNING SERVICES

CARABINIERI

TERMINILLO MONTI REATINI E LAGA OVEST

PREVISIONE METEO

Quota		14/02/2026 h6:00	14/02/2026 h12:00	14/02/2026 h18:00
1000	Venti	10 Nodi da Sud	07 Nodi da Sud	03 Nodi da Sud
	Temperature	+02 °C	+03 °C	+03 °C
	Temp.percepita	-2 °C	-0 °C	2 °C
2000	Venti	23 Nodi da Sud	17 Nodi da Sud	07 Nodi da Sud
	Temperature	-01 °C	-01 °C	-01 °C
	Temp.percepita	-9 °C	-8 °C	-5 °C
3000	Venti	21 Nodi da Sud	16 Nodi da S-Ovest	05 Nodi da Sud
	Temperature	-07 °C	-06 °C	-06 °C
	Temp.percepita	-17 °C	-14 °C	-10 °C
Zero termico		1700-1900 m.	1800-2000 m.	1800-2000 m.
Fenomeno				—
Stato del cielo				

LEGENDA FENOMENI

— Assenza Fenomeni · Nebbia · Foschia · Pioggia debole · Pioggia moderata · Pioggia forte · Temporali

Nevicata debole · Nevicata moderata · Nevicata forte

STATO DEL CIELO

Sereno · Poco nuvoloso · Nuvoloso · Molto nuvoloso · Coperto

Parametri meteonivometrici registrati presso i campi di rilevamento il 13/02/2026.

Località	Comune	Quota (m.s.l.m.)	Altezza neve (cm)	Neve caduta nelle 24 ore (cm)	Temp. Min (°C)	Temp. Max (°C)	Condizioni del tempo
PESCHIERE	Amatrice (RI)	1270	0	0	+1	+5	Assenza di precipitazioni
M. CAIDURO	Cittareale (RI)	1300	0	0	+2	+4	Assenza di precipitazioni
VALLONINA	Leonessa (RI)	1350	10	0	-2	+4	Assenza di precipitazioni
GIRO DELL'ANELLO - VILLA CHIGI *	Rieti (RI)	1766	59	N.P.	-1	+2	Assenza di precipitazioni

(*) Rilievi fuori campo

L'INFORMAZIONE E' PREVENZIONE - LEGGI L'ATTUALE GRADO DI PERICOLO VALANGHE!

IL CAPO DEL CENTRO NAZIONALE METEOMONT
(Ten. Col. RFI Emanuela Gini)
FIRMA AUTOGRAFA OMESSA AI SENSI
DELL'ART.3 DEL D.LGS N.39/1993

Bollettino realizzato su scala sinottica-regionale (standard EAWS). La sua valutazione non può escludere in alcun modo la necessità di una seria e capace valutazione locale del pericolo (singolo pendio) che può essere anche sensibilmente diverso. Le previsioni meteorologiche sono relative all'orario UTC (per l'Italia +1 in inverno e +2 in estate).