Bulletin d'estimation du risque d'avalanche
(valable en dehors des pistes balisées et ouvertes)

MASSIF : Bauges

Rédigé le samedi 14 février 2026 à 16h

Estimation des risques pour le : DIMANCHE 15 FÉVRIER

STABILISATION À GRANDE ÉCHELLE. NOUVELLES PLAQUES À VENT.

3

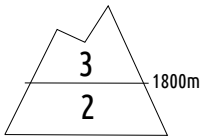

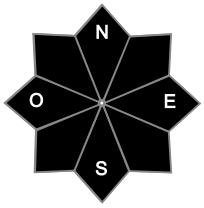

Au-dessus de 1800m indice de risque marqué, plus bas indice limité.

Départs spontanés : Rares ruptures de plaques sous la Bise

Déclenchements provoqués : Encore des plaques dans la neige récente + travaillée par la Bise.

Indices de risque : 5 très fort - 4 fort - 3 marqué - 2 limité - 1 faible -- En noir : les pentes les plus dangereuses

Stabilité du manteau neigeux

Situation avalancheuse typique : neige ventée

Déclenchements provoqués :
* Des **plaques à vent** continuent de se former dans la neige fraîche. Selon les secteurs, ces plaques sont d'aspects friables ou dures. Elles se situent dans les zones travaillées par la Bise (vent de NE), notamment sur les sommets les plus hauts au-dessus de 1800/2000m. Taille 2 à 3.
Observables : Zones d'accumulation, fissures devant les skis, neige travaillée par le vent, ...

Départs spontanés :
* Ruptures de plaques ou de corniches possibles sous la Bise, notamment dans les pentes raides et les couloirs chargés. Taille 2, très rarement 3 possible.
* Rares plaques de fond sous 2200m. Départs possibles à toute heure du jour et de la nuit sur un fond lisse (herbes/vires). Taille 2.

Qualité de la neige

Enneigement : Les chutes de neige ont permis d'épaissir le manteau et de donner un bon enneigement pour la saison. On peut chausser les skis vers 1200 m. Au-delà de 1400/1500 m, on retrouve les sous-couches. Nombreuses congères et grosses corniches.

Qualité de la neige ce samedi :
- épaisse couche de neige récente (60/80 cm). Elle est restée froide en ubacs. En adrets, cette neige est légèrement matée, voire croutée sous 1800m. Neige travaillée par la Bise durant la nuit de samedi à dimanche, surtout au-dessus de 2000/2200 m.
- Sous 1800 m, on retrouve un fond lourd humide en cours de regel.

Aperçu météo pour le dimanche 15 février

nuit	matin	après-midi	soir

Fins nuages bas autour de 2000m. Rapidement, le soleil domine. En fin d'après-midi, le ciel se recouvre avant la neige de la nuit.

	nuit	matin	après-midi	soir
Pluie-Neige	600 m		1 000 m	1 200 m
Iso 0 °C	1 100 m	1 600 m	1 500 m	1 800 m
Vent 1500 m	↓ 35 km/h	↓ 20 km/h	↘ 20 km/h	↗ 25 km/h
Vent 2000 m	↓ 45 km/h	↘ 35 km/h	↘ 35 km/h	→ 45 km/h

Épaisseur de neige hors-piste

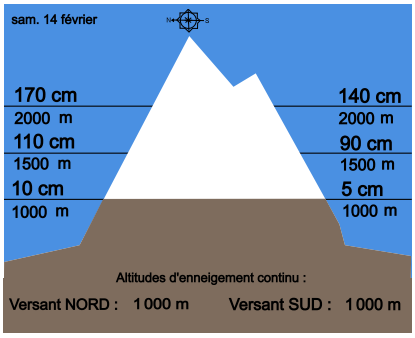

Précipitations à 1800 m

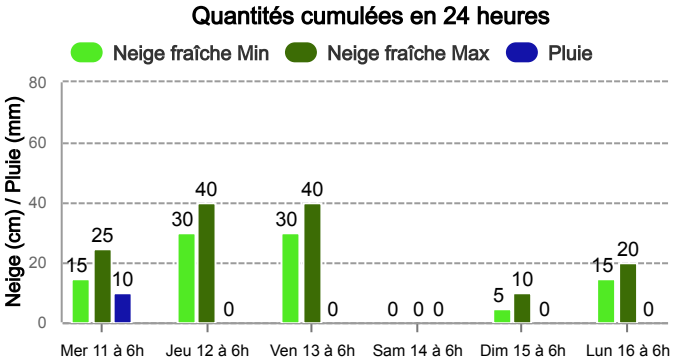

Tendance du lundi 16 février

3 **Indice de risque marqué**

À partir de la nuit de dimanche à lundi et jusqu'à lundi, on attend 50/70 cm de neige fraîche. Cette neige est ventée et ainsi les plaques sont présentes dans tout le massif, et peuvent, dans les accumulations, faire des cassures de plus d'1m.

Pour consulter la vigilance en cours, veuillez vous rendre sur le site https://vigilance.meteofrance.fr/fr

Météo-France - 73 avenue de Paris, 94165 Saint-Mandé cedex - Contact : contact@meteo.fr

Rédigé par Météo-France avec la contribution des observateurs du réseau nivo-météorologiques. Partenariat : ANMSM (Maires de Stations de Montagne), DSF (Domaines Skiables de France), ADSP (Directeurs de Pistes et de la Sécurité des Stations de Sports d'Hiver) et autres acteurs de la montagne.

Bulletin neige & avalanches par téléphone au
0 892 68 10 20 Service 0,35 € / min + prix appel

Bulletin d'estimation du risque d'avalanche

(valable en dehors des pistes balisées et ouvertes)

MASSIF : Bauges

Rédigé le samedi 14 février 2026 à 16h

Conditions nivo-météo des 7 derniers jours

	dim. 08/02				lun. 09/02				mar. 10/02				mer. 11/02				jeu. 12/02				ven. 13/02				sam. 14/02			
	03h	09h	15h	21h	03h	09h	15h	21h	03h	09h	15h	21h	03h	09h	15h	21h	03h	09h	15h	21h	03h	09h	15h	21h	03h	09h	15h	21h
Météo																												
Vent (km/h)	10	10	15	10	10	15	25	45	45	55	40	50	65	50	45	65	60	60	50	60	50	40	40	30	30	30	35	35
à 2000m																												
Vent (km/h)	5	5	10	5	5	10	15	35	35	40	30	40	50	40	35	55	50	40	40	50	40	30	20	20	20	20	25	25
à 1500m																												

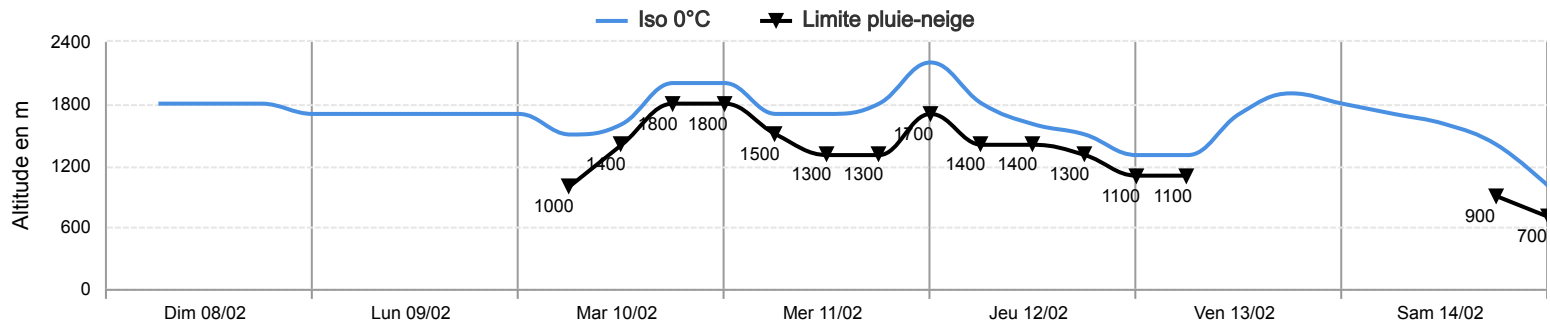

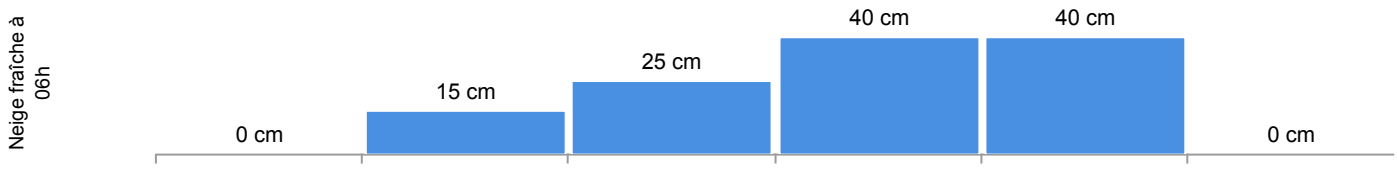

Risque d'avalanche	dim. 08/02	lun. 09/02	mar. 10/02	mer. 11/02	jeu. 12/02	ven. 13/02	sam. 14/02
	2	2	3	4	4	3	3

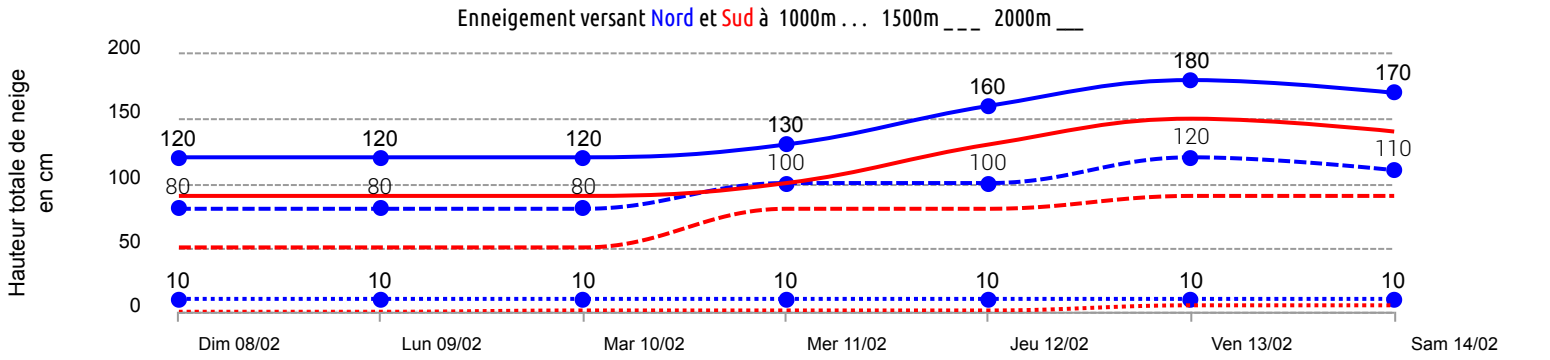

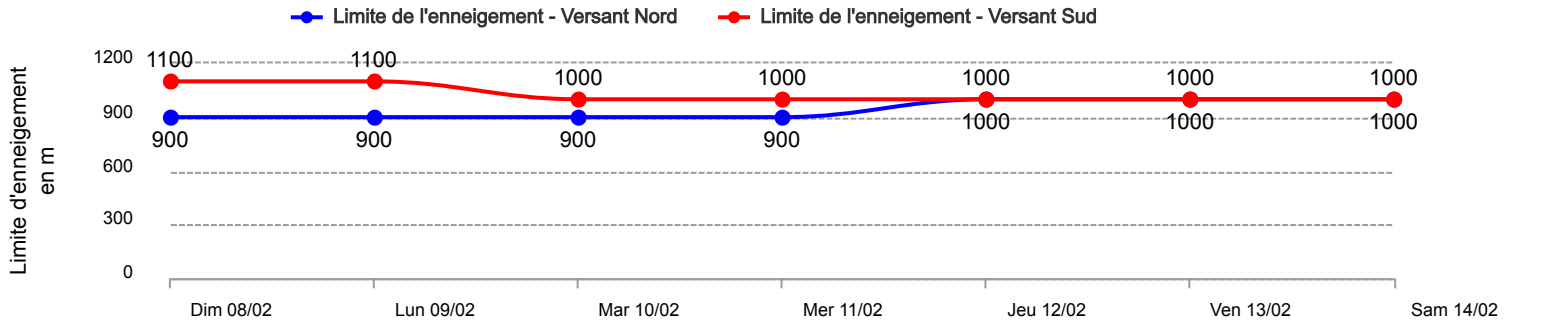

Pour consulter la vigilance en cours, veuillez vous rendre sur le site https://vigilance.meteofrance.fr/fr

Météo-France - 73 avenue de Paris, 94165 Saint-Mandé cedex - Contact : contact@meteo.fr

Rédigé par Météo-France avec la contribution des observateurs du réseau nivo-météorologiques. Partenariat : ANMSM (Maires de Stations de Montagne), DSF (Domaines Skiables de France), ADSP (Directeurs de Pistes et de la Sécurité des Stations de Sports d'Hiver) et autres acteurs de la montagne.

Bulletin neige & avalanches par téléphone au 0 892 68 10 20 Service 0,35 € / min + prix appel