Bulletin d'estimation du risque d'avalanche
(valable en dehors des pistes balisées et ouvertes)

MASSIF : Beaufortain

Rédigé le samedi 14 février 2026 à 16h

Estimation des risques pour le : DIMANCHE 15 FÉVRIER

MANTEAU INSTABLE : RISQUE ACCIDENTEL MARQUÉ (3/4) - POSSIBLES GRANDES AVALANCHES

3

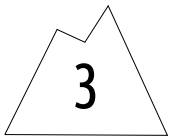

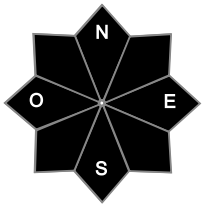

Indice de risque marqué.

Départs spontanés : départs linéaires possibles sous le vent.

Déclenchements provoqués : plaques réactives, localement épaisses

Indices de risque : 5 très fort - 4 fort - 3 marqué - 2 limité - 1 faible -- En noir : les pentes les plus dangereuses

Stabilité du manteau neigeux

Situation avalancheuse typique : neige ventée couche fragile persistante

Déclenchements provoqués :
- **Quelques plaques**, formées par les récentes **variations de vent**, sont hébergées dans la neige récente. Elles sont particulièrement **réactives sous le vent de Nord à Nord-Ouest**, et de manière générale **plus sensibles en montant en altitude**. Avalanches de taille 2 (moyenne) majoritaires, taille 3 (grande) si la topographie le permet.
Facteur aggravant : possible déclenchement en cascade si un premier départ sollicite **une couche fragile persistante** enfouie plus profondément (plutôt dans les pentes Ouest, Nord et Est). Ces avalanches peuvent alors mobiliser de grands volumes (taille 3, grande avalanche possible).

Départs spontanés : quelques départs linéaires possibles sous le vent de Nord à Nord-Ouest, plutôt d'ampleur limitée (taille 1 à 2) mais un départ en cascade plus grand reste possible (taille 3).

Qualité de la neige

Enneigement : le bilan des chutes de neige est largement positif dès 1500 m d'altitude, les hauteurs sont à nouveau excédentaires au-delà. Il est tombé en moyenne 100/130 cm de neige au-dessus de 2000 m depuis mardi.

Limite skiable : en nord, skiable sur l'herbe ou sur pistes forestières dès 1000 m, dans les sous-bois dès 1200 m. En sud, skiable dès 1200 m en prairies pas trop raides, 1600 m en Sud raide.

Qualité de la neige : très gros cumuls de neige ventée en haute montagne, avec plus d'1 m dans les zones d'accumulations tandis que les croupes sont moins chargées.
La neige s'est humidifiée en sud/sud-est jusque vers 2000/2200 m et quelle que soit l'orientation sous 1600 m , ces zones pourront être croutées et désagréables à skier.

Aperçu météo pour le dimanche 15 février

	nuit	matin	après-midi	soir
Pluie-Neige	500 m			1 000 m
Iso 0 °C	1 000 m	1 200 m	1 600 m	1 700 m
Vent 2000 m	↘ 25 km/h	→ 15 km/h	→ 15 km/h	→ 25 km/h
Vent 3000 m	↓ 40 km/h	↓ 35 km/h	→ 35 km/h	↘ 55 km/h

Court créneau météo le matin, entre la grisaille résiduelle et la couverture nuageuse de la perturbation très active arrivant en fin de journée.

Épaisseur de neige hors-piste

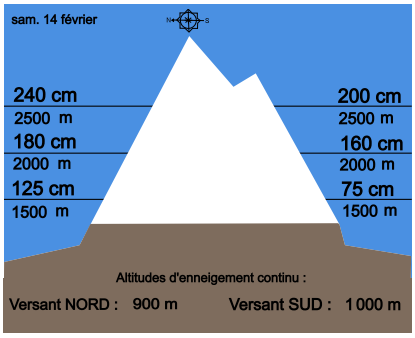

Précipitations à 1800 m

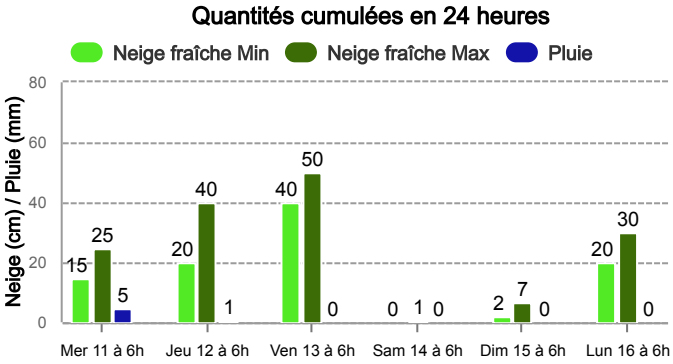

Tendance du lundi 16 février

Indice de risque fort

Risque devenant fort. Fortes chutes de neige. Nombreux départs spontanés attendues. Avalanches spontanées de grande ampleur possibles.

Pour consulter la vigilance en cours, veuillez vous rendre sur le site https://vigilance.meteofrance.fr/fr

Météo-France - 73 avenue de Paris, 94165 Saint-Mandé cedex - Contact : contact@meteo.fr

Rédigé par Météo-France avec la contribution des observateurs du réseau nivo-météorologiques. Partenariat : ANMSM (Maires de Stations de Montagne), DSF (Domaines Skiables de France), ADSP (Directeurs de Pistes et de la Sécurité des Stations de Sports d'Hiver) et autres acteurs de la montagne.

Bulletin neige & avalanches par téléphone au 0 892 68 10 20 Service 0,35 € / min + prix appel

RÉPUBLIQUE FRANÇAISE
Liberté Égalité Fraternité

METEO FRANCE
À VOS CÔTÉS, DANS UN CLIMAT QUI CHANGE

Bulletin d'estimation du risque d'avalanche

(valable en dehors des pistes balisées et ouvertes)

MASSIF : Beaufortain

Rédigé le samedi 14 février 2026 à 16h

Conditions nivo-météo des 7 derniers jours

	dim. 08/02				lun. 09/02				mar. 10/02				mer. 11/02				jeu. 12/02				ven. 13/02				sam. 14/02			
	03h	09h	15h	21h	03h	09h	15h	21h	03h	09h	15h	21h	03h	09h	15h	21h	03h	09h	15h	21h	03h	09h	15h	21h	03h	09h	15h	21h
Météo																												
Vent (km/h)	15	20	20	20	20	15	20	25	30	35	45	55	70	55	45	75	90	90	85	70	50	40	40	50	35	15	40	40
à 3000m																												
Vent (km/h)	10	15	10	10	10	10	10	10	15	20	25	35	50	40	25	50	70	75	65	40	25	15	30	40	30	10	25	25
à 2000m																												

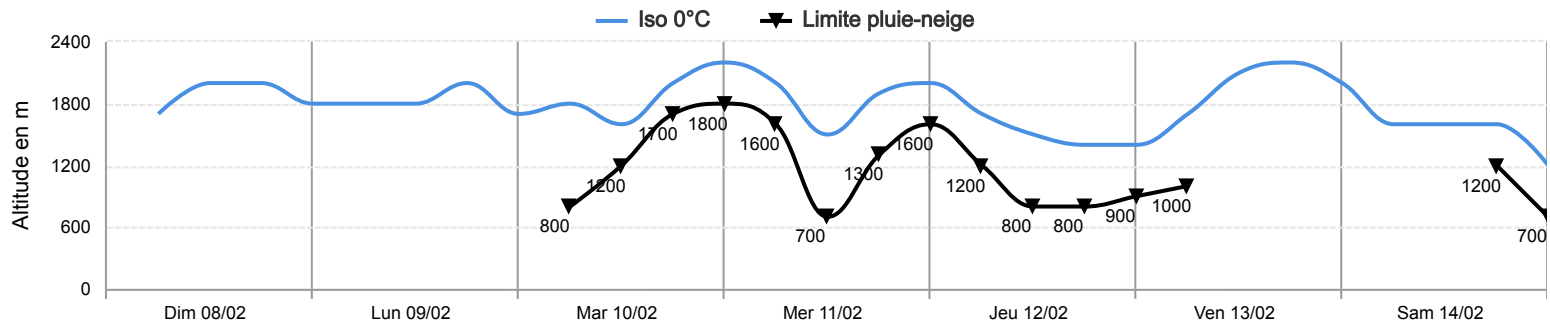

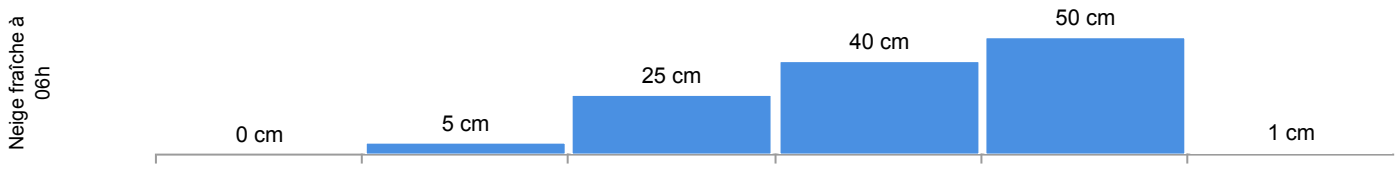

Risque d'avalanche	dim. 08/02	lun. 09/02	mar. 10/02	mer. 11/02	jeu. 12/02	ven. 13/02	sam. 14/02
	2	2	3	4	5	4	4

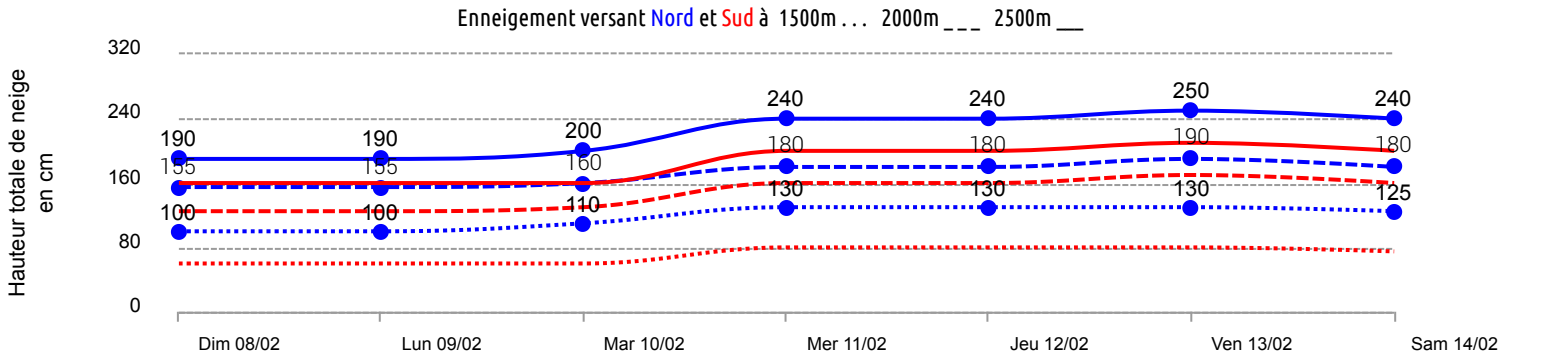

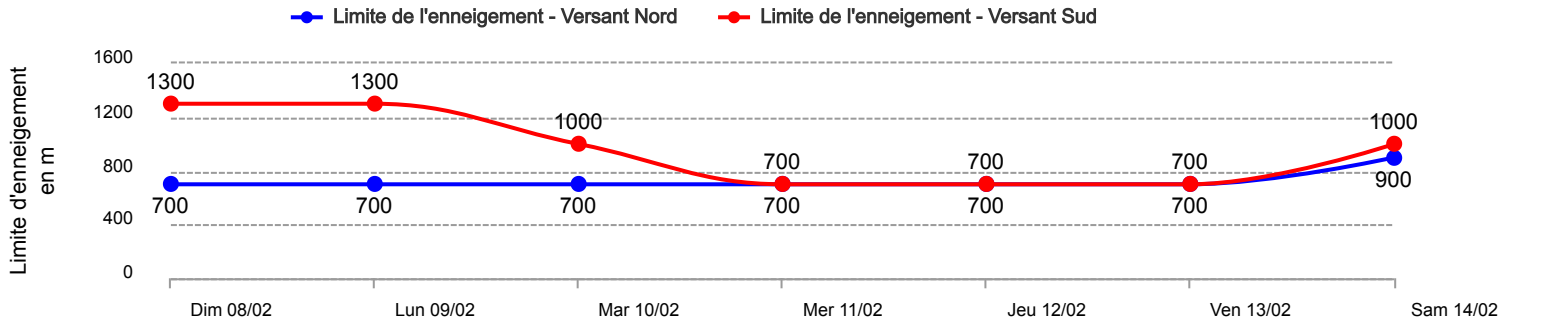

Pour consulter la vigilance en cours, veuillez vous rendre sur le site https://vigilance.meteofrance.fr/fr

Météo-France - 73 avenue de Paris, 94165 Saint-Mandé cedex - Contact : contact@meteo.fr

Rédigé par Météo-France avec la contribution des observateurs du réseau nivo-météorologiques. Partenariat : ANMSM (Maires de Stations de Montagne), DSF (Domaines Skiables de France), ADSP (Directeurs de Pistes et de la Sécurité des Stations de Sports d'Hiver) et autres acteurs de la montagne.

Bulletin neige & avalanches par téléphone au

0 892 68 10 20 Service 0,35 € / min + prix appel