Bulletin d'estimation du risque d'avalanche

(valable en dehors des pistes balisées et ouvertes)

MASSIF : Capcir Puymorens

Rédigé le samedi 14 février 2026 à 16h

Estimation des risques pour le : DIMANCHE 15 FÉVRIER

INSTABILITE GENERALISEE : NOMBREUX DÉPARTS SPONTANÉS, DÉCLENCHEMENTS FACILES DANS LA NEIGE FRAÎCHE.

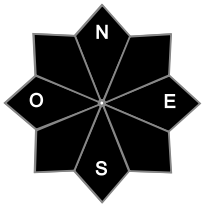

Indice de risque fort.

Départs spontanés : Nombreux départs ponctuels ou linéaires, avalanches de grande taille possibles.

Déclenchements provoqués : Forte instabilité temporaire dans la neige fraîche et ventée, cassures importantes avec propagation : Risque accidentel maximal

Indices de risque : 5 très fort - 4 fort - 3 marqué - 2 limité - 1 faible -- En noir : les pentes les plus dangereuses

Stabilité du manteau neigeux

Situation avalancheuse typique : neige fraîche neige humide

Épisode de neige abondante et de vent soutenu terminant ce samedi soir avec des cumuls de neige fraiche en 36h de 40 à 70 cm à 1800m. Arrivée de la pluie dimanche soir.

Déclenchements provoqués : Risque Temporaire mais Maximal.
En tous versants, des déclenchements d'avalanche sont facilement déclenchables au passage d'un simple skieur ou randonneur. De nombreuses structures de plaques se forment dans la neige récente au fil des chutes de neige et même après avec le maintient d'un fort transport de neige par le vent, parfois loin des crêtes. Elles sont souvent **difficilement identifiables** en gardant un aspect poudreux ou en étant recouvertes d'une couche de neige fraîche. Les avalanches sont souvent moyennes à grandes (taille 2 à 3) avec des cassures dépassant fréquemment les 30 à 40 cm, notamment dans les pentes d'un large secteur EST d'altitude, favorables aux accumulations. Dans certaines configurations, des cassures de 50 à 80 cm sont envisageables avec propagation entrainant exceptionnellement une avalanche de taille 4 , surtout au dessus de 2200 à 2400m.
Observables : quantité de neige fraiche critique (>50 cm), fissures sous les skis, "Whoumf", couverture de neige hétérogène en surface.

Départs spontanés :
Première problématique : Neige Fraîche
Les cumuls de neige fraiche sont critiques, dépassant les 50 cm en moins de 36h à 1800m : des **départs ponctuels sont fréquents** dans les pentes raides pouvant devenir linéaires par effet de cascade en tous versants. Ces avalanches pourront alors emporter l'ensemble des chutes de neige en cours et seront de taille moyenne à grande (taille 2 à 3) et parfois très grande (T4) dans certaines configurations. Avec le retour du soleil dimanche matin, les départs seront plus fréquents dans les pentes Est à Sud-Est.

Seconde problématique : Neige humide
L'arrivée dimanche soir d'une nouvelle perturbation pluvieuse active avec une limite pluie-neige à 1800 puis 2000m va faciliter le départ de nombreuses avalanches de neige humide en moyenne montagne pouvant parfois toucher le réseau secondaire (entre 1200 et 1700m). Ces nouvelles chutes de neige pourront aussi favoriser une reprise de l'activité spontanée en altitude (au dessus de 2200m) en avalanche de neige poudreuse.

Qualité de la neige

Enneigement :
Enneigement très bon sur nos massifs, au-dessus des normales et nettement supérieur à celui des cinq dernières années. L'enneigement débute vers 1200m dimanche matin et devient conséquent dès 1400 à 1500m. La barre des 2m de neige est souvent atteinte dès 2000m d'altitude.

Qualité de la neige :
Dimanche matin, la montagne retrouve un aspect bien blanc dès 1100 m d'altitude. On trouvera quelques cm dès 900m et déjà 30 à 40 cm de neige fraîche dès 1500 m. Cette couche de neige fraîche va devenir de plus en plus épaisse en prenant de l'altitude pouvant atteindre 1m au dessus de 2500m.
On trouve donc une neige poudreuse dans les vallons et secteurs abrités du vent.
Ce vent de nord-ouest puis de nord reste fort et va travailler cette neige avec une couverture très hétérogène en se rapprochant des cols et crêtes. Des accumulations conséquentes sur les versants Est principalement sont probables avec la formation de grosses corniches. Les plus hauts sommets peuvent se retrouver décapés par le vent violent.

Aperçu météo pour le dimanche 15 février

	nuit	matin	après-midi	soir

Fin de la neige samedi soir, arrivée de la pluie dimanche soir !

Pluie-Neige	800 m			
Iso 0 °C	1 400 m	2 200 m	2 400 m	2 800 m
Vent 2000 m	↘ 80 km/h	↘ 45 km/h	↘ 50 km/h	↘ 60 km/h
Vent 3000 m	↓ 105 km/h	↘ 80 km/h	↘ 70 km/h	↘ 70 km/h

Pour consulter la vigilance en cours, veuillez vous rendre sur le site https://vigilance.meteofrance.fr/fr

Météo-France - 73 avenue de Paris, 94165 Saint-Mandé cedex - Contact : contact@meteo.fr

Rédigé par Météo-France avec la contribution des observateurs du réseau nivo-météorologiques. Partenariat : ANMSM (Maires de Stations de Montagne), DSF (Domaines Skiables de France), ADSP (Directeurs de Pistes et de la Sécurité des Stations de Sports d'Hiver) et autres acteurs de la montagne.

Bulletin neige & avalanches par téléphone au 0 892 68 10 20 Service 0,35 € / min + prix appel

RÉPUBLIQUE FRANÇAISE
Liberté Égalité Fraternité

METEO FRANCE
À VOS CÔTÉS, DANS UN CLIMAT QUI CHANGE

Bulletin d'estimation du risque d'avalanche

(valable en dehors des pistes balisées et ouvertes)

MASSIF : Capcir Puymorens

Rédigé le samedi 14 février 2026 à 16h

Épaisseur de neige hors-piste

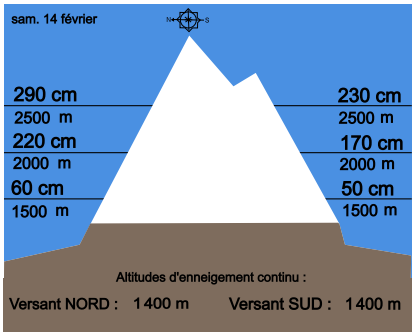

Précipitations à 1800 m

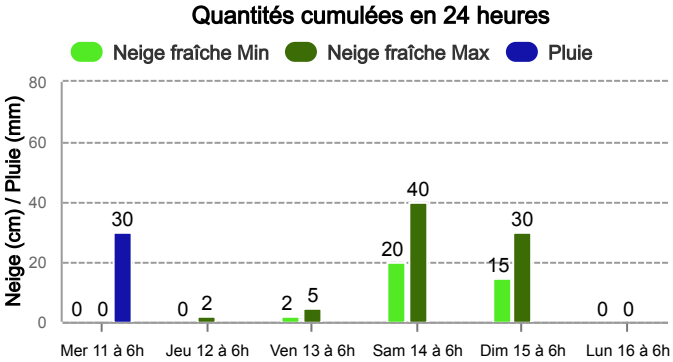

Tendance du lundi 16 février

Indice de risque fort

Augmentation du risque spontané avec les pluies attendues en altitude. Baisse du risque accidentel.

Pour consulter la vigilance en cours, veuillez vous rendre sur le site https://vigilance.meteofrance.fr/fr

Météo-France - 73 avenue de Paris, 94165 Saint-Mandé cedex - Contact : contact@meteo.fr

Rédigé par Météo-France avec la contribution des observateurs du réseau nivo-météorologiques. Partenariat : ANMSM (Maires de Stations de Montagne), DSF (Domaines Skiables de France), ADSP (Directeurs de Pistes et de la Sécurité des Stations de Sports d'Hiver) et autres acteurs de la montagne.

Bulletin neige & avalanches par téléphone au

0 892 68 10 20 Service 0,35 € / min + prix appel

RÉPUBLIQUE FRANÇAISE
Liberté Égalité Fraternité

METEO FRANCE
À VOS CÔTÉS, DANS UN CLIMAT QUI CHANGE

Bulletin d'estimation du risque d'avalanche

(valable en dehors des pistes balisées et ouvertes)

MASSIF : Capcir Puymorens

Rédigé le samedi 14 février 2026 à 16h

Conditions nivo-météo des 7 derniers jours

	dim. 08/02				lun. 09/02				mar. 10/02				mer. 11/02				jeu. 12/02				ven. 13/02				sam. 14/02			
	03h	09h	15h	21h	03h	09h	15h	21h	03h	09h	15h	21h	03h	09h	15h	21h	03h	09h	15h	21h	03h	09h	15h	21h	03h	09h	15h	21h
Météo																												
Vent (km/h)	55	30	55	50	55	40	60	65	70	70	80	85	65	60	55	65	90	110	105	85	55	60	50	90	80	100	110	90
à 3000m																												
Vent (km/h)	45	20	35	35	35	20	30	35	35	40	50	60	50	50	35	45	55	85	80	60	50	50	40	75	75	85	100	80
à 2000m																												

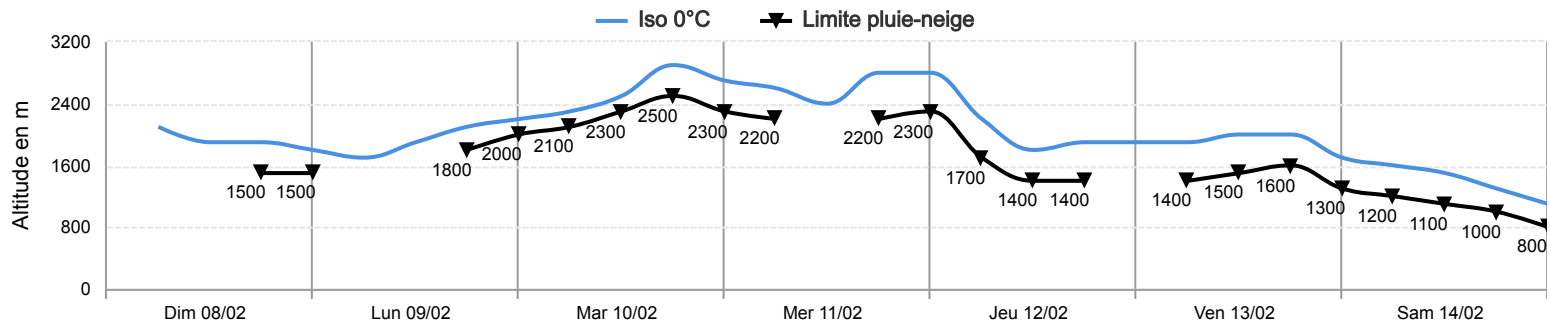

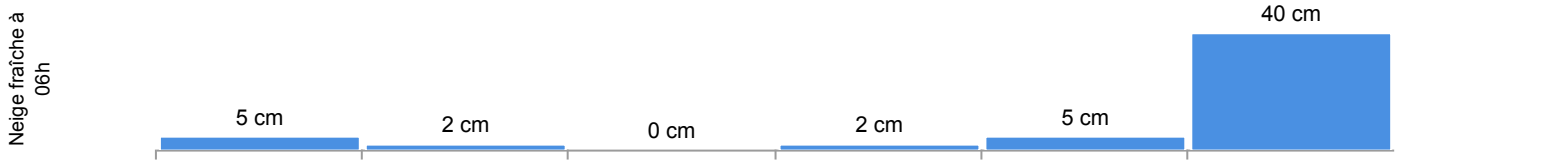

Risque d'avalanche	dim. 08/02	lun. 09/02	mar. 10/02	mer. 11/02	jeu. 12/02	ven. 13/02	sam. 14/02
	2	2	4	4	3	2	3

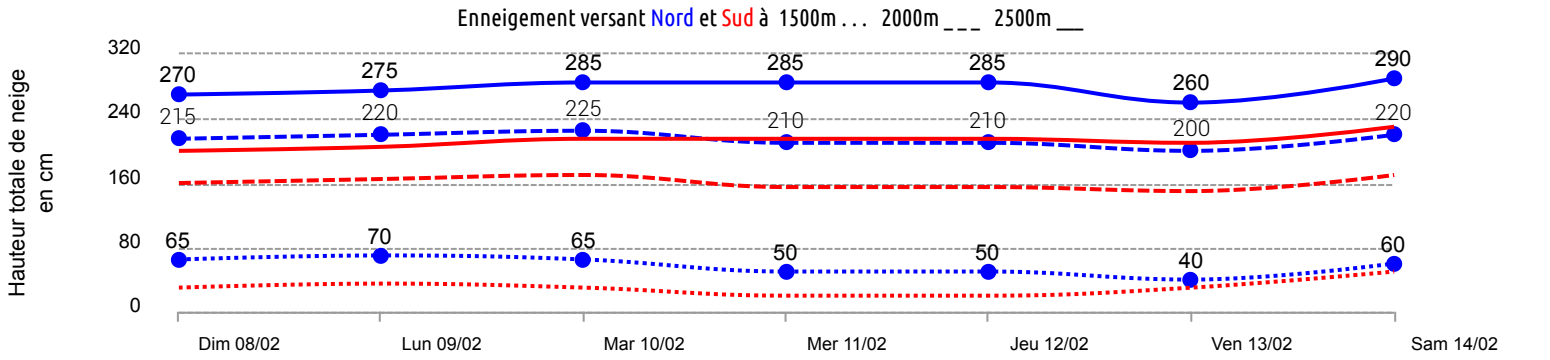

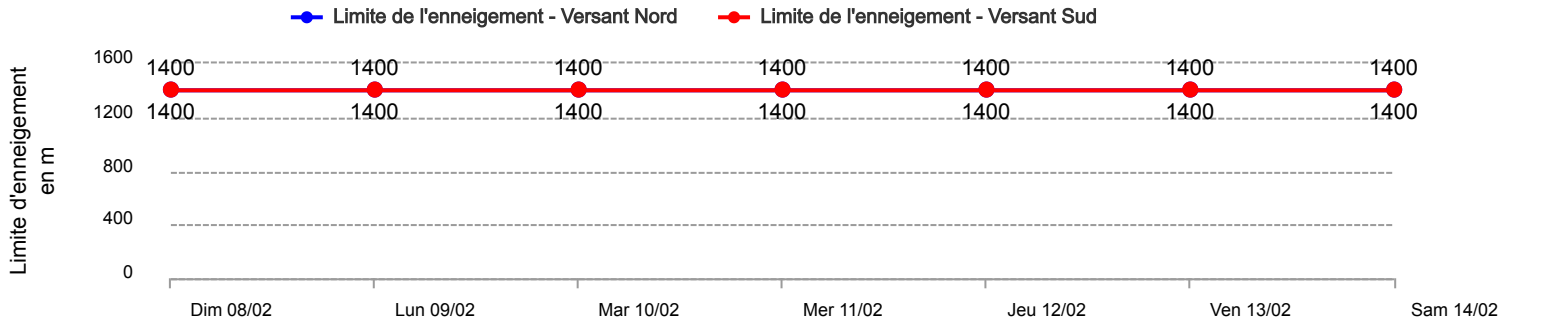

Pour consulter la vigilance en cours, veuillez vous rendre sur le site https://vigilance.meteofrance.fr/fr

Météo-France - 73 avenue de Paris, 94165 Saint-Mandé cedex - Contact : contact@meteo.fr

Rédigé par Météo-France avec la contribution des observateurs du réseau nivo-météorologiques. Partenariat : ANMSM (Maires de Stations de Montagne), DSF (Domaines Skiables de France), ADSP (Directeurs de Pistes et de la Sécurité des Stations de Sports d'Hiver) et autres acteurs de la montagne.

Bulletin neige & avalanches par téléphone au

0 892 68 10 20 Service 0,35 € / min + prix appel