Bulletin d'estimation du risque d'avalanche
(valable en dehors des pistes balisées et ouvertes)

MASSIF : Cerdagne Canigou

Rédigé le samedi 14 février 2026 à 16h

Estimation des risques pour le : DIMANCHE 15 FÉVRIER

STRUCTURES DE PLAQUES EN ALTITUDE

3

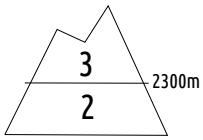

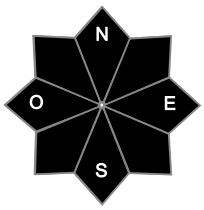

Vaste Est

Au-dessus de 2300m indice de risque marqué, plus bas indice limité.

Départs spontanés : En altitude, peu probable ou par surcharge de neige par le vent

Déclenchements provoqués : Plaques à vent en altitude

Indices de risque : 5 très fort - 4 fort - 3 marqué - 2 limité - 1 faible -- En noir : les pentes les plus dangereuses

Stabilité du manteau neigeux

Situation avalancheuse typique : neige ventée avalanches de fond

Déclenchements provoqués : Structures de plaques friables.
En altitude, au dessus de 2200 à 2400m en général, des structures de plaques souvent dures mais parfois friables se forment sous le vent de nord-ouest. Malgré le peu de neige fraîche présente (5 à 10cm), des accumulations de 30 à 50 cm peuvent se former et céder au passage d'un skieur. Elles sont surtout dans un large secteur Est (du nord au sud en passant par l'est) et pourront mener à des avalanches de taille 1 à 2 (petites à moyennes).
Observable : zone d'accumulations dures sous le vent, neige travaillée par le vent en surface.

Départs spontanés :
En altitude, peu probable ou par surcharge de neige par le vent dans les pentes d'un large secteur Nord-Est à Sud-Est d'altitude.
En dessous de 1800m environ, des avalanches de fond peuvent encore se produire plutôt dans les pentes raides et bien ensoleillées. Elle pourront générer des avalanches de taille petite à moyenne (taille 1 à 2)
Observable : Large fissure d'apparition récente en pentes herbeuses / dalles rocheuses.

Qualité de la neige

Enneigement :
Après plusieurs hivers déficitaires, l'enneigement sur le massif en cette mi-Février demeure largement au-dessus des normales et nettement supérieur à celui des cinq dernières années.
Malgré le fort redoux du début de semaine, la limite de skiabilité se situe encore au plus bas vers 1300/1400 m dans les meilleures configurations. On peut skier plus confortablement vers 1500/1600m

État de la neige :
Au petit matin, on observe souvent un bon regel nocturne avec une neige dure, souvent portante. Quelques combes pourront receler un peu de neige fraîche à l'abri de la tramontane. Au fil de la journée, les pentes ensoleillées se transforment et on trouve souvent une agréable neige de printemps pouvant devenir lourde et parfois pourrie à basse altitude l'après-midi.
En altitude, on trouvera une neige souvent dure et travaillée par le vent, pas forcément agréable à skier car trés irrégulière.

Aperçu météo pour le dimanche 15 février

nuit	matin	après-midi	soir

Belle journée si on reste à l'abri du vent !

Pluie-Neige				
Iso 0 °C	1 600 m	2 400 m	2 500 m	2 600 m
Vent 2000 m	↘ 60 km/h	↘ 40 km/h	↘ 35 km/h	↘ 40 km/h
Vent 3000 m	↘ 95 km/h	↓ 60 km/h	↘ 65 km/h	→ 65 km/h

Épaisseur de neige hors-piste

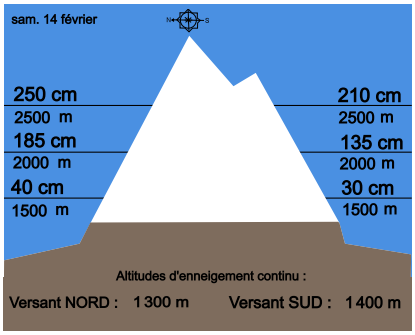

Précipitations à 1800 m

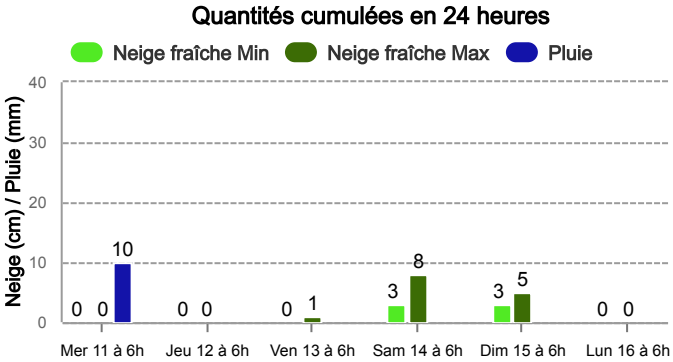

Tendance du lundi 16 février

3

Indice de risque marqué

Maintient d'un risque accidentel en altitude.

Pour consulter la vigilance en cours, veuillez vous rendre sur le site https://vigilance.meteofrance.fr/fr

Météo-France - 73 avenue de Paris, 94165 Saint-Mandé cedex - Contact : contact@meteo.fr

Rédigé par Météo-France avec la contribution des observateurs du réseau nivo-météorologiques. Partenariat : ANMSM (Maires de Stations de Montagne), DSF (Domaines Skiables de France), ADSP (Directeurs de Pistes et de la Sécurité des Stations de Sports d'Hiver) et autres acteurs de la montagne.

Bulletin neige & avalanches par téléphone au 0 892 68 10 20 Service 0,35 € / min + prix appel

RÉPUBLIQUE FRANÇAISE
Liberté Égalité Fraternité

METEO FRANCE
À VOS CÔTÉS, DANS UN CLIMAT QUI CHANGE

Bulletin d'estimation du risque d'avalanche
(valable en dehors des pistes balisées et ouvertes)
MASSIF : Cerdagne Canigou

Rédigé le samedi 14 février 2026 à 16h

Conditions nivo-météo des 7 derniers jours

	dim. 08/02				lun. 09/02				mar. 10/02				mer. 11/02				jeu. 12/02				ven. 13/02				sam. 14/02			
	03h	09h	15h	21h	03h	09h	15h	21h	03h	09h	15h	21h	03h	09h	15h	21h	03h	09h	15h	21h	03h	09h	15h	21h	03h	09h	15h	21h
Météo																												
Vent (km/h)	55	50	50	40	50	35	55	45	50	50	55	60	75	75	60	70	90	120	115	80	75	85	60	90	90	90	100	100
à 3000m																												
Vent (km/h)	45	40	35	25	30	20	25	20	30	30	30	40	45	45	35	50	65	90	90	55	45	50	35	60	70	70	80	80
à 2000m																												

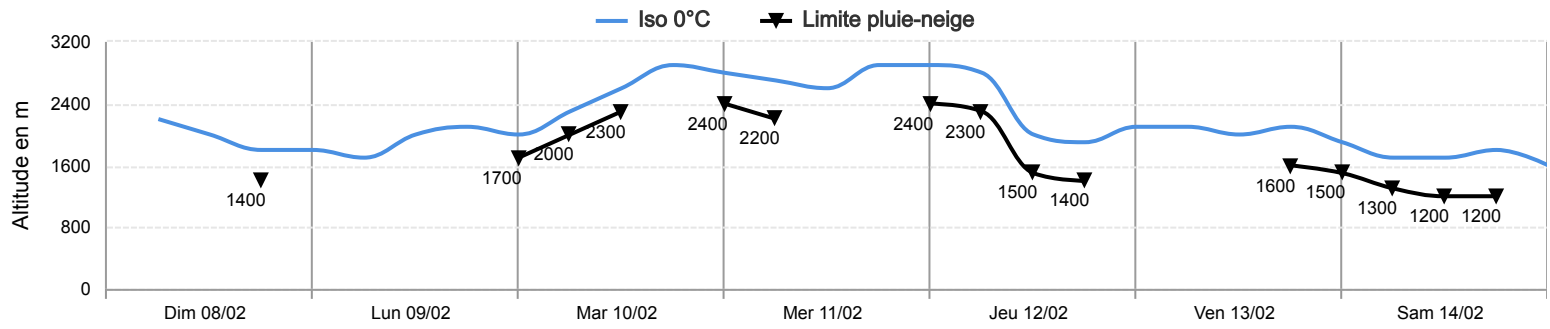

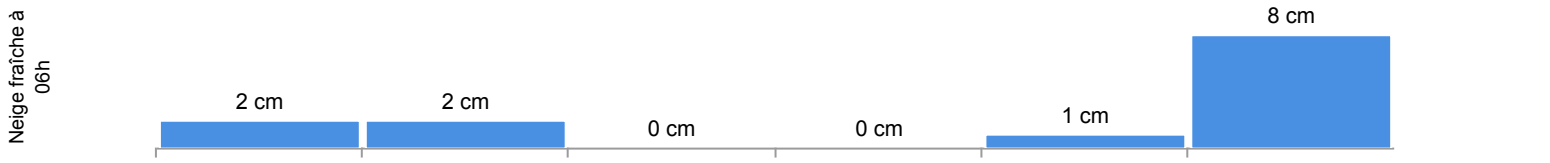

Risque d'avalanche	dim. 08/02	lun. 09/02	mar. 10/02	mer. 11/02	jeu. 12/02	ven. 13/02	sam. 14/02
	2	2	2	3	2	2	2

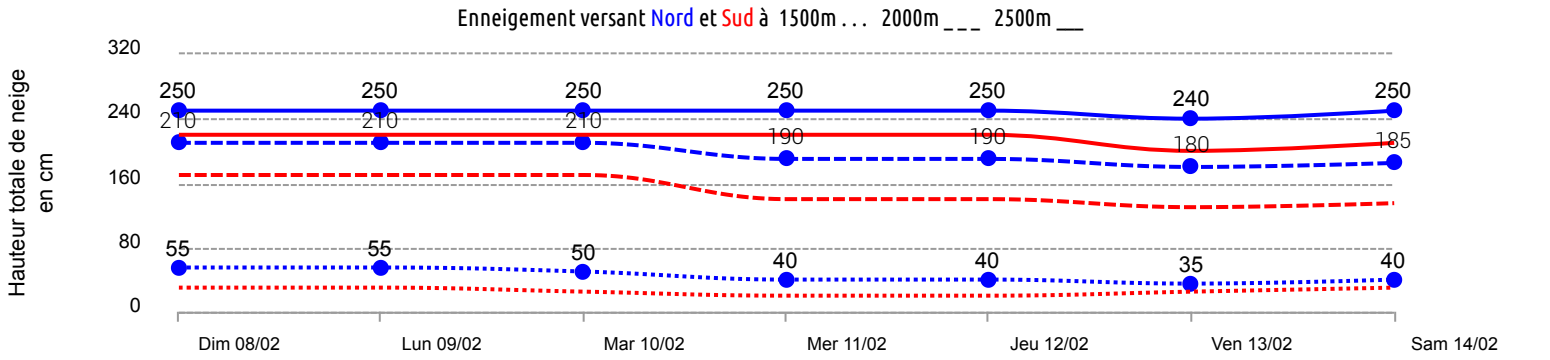

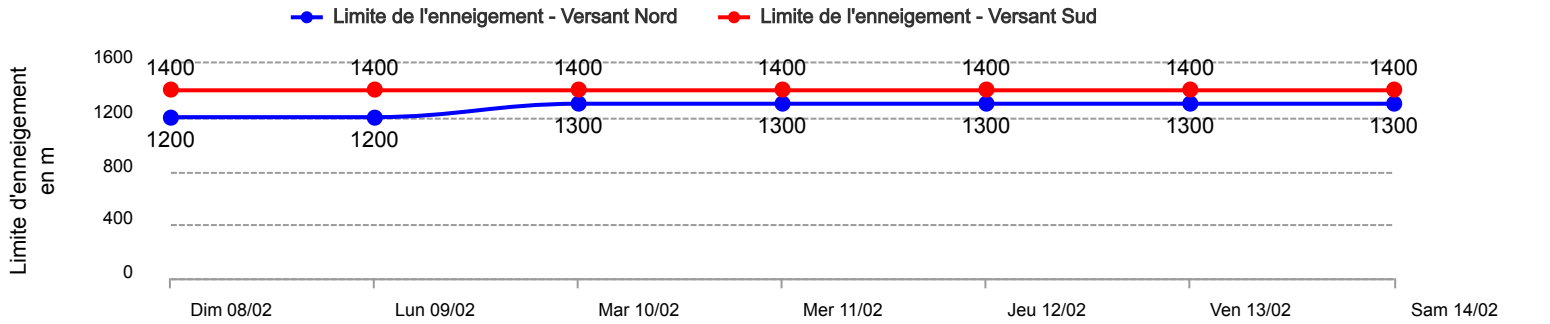

Pour consulter la vigilance en cours, veuillez vous rendre sur le site https://vigilance.meteofrance.fr/fr

Météo-France - 73 avenue de Paris, 94165 Saint-Mandé cedex - Contact : contact@meteo.fr

Rédigé par Météo-France avec la contribution des observateurs du réseau nivo-météorologiques. Partenariat : ANMSM (Maires de Stations de Montagne), DSF (Domaines Skiables de France), ADSP (Directeurs de Pistes et de la Sécurité des Stations de Sports d'Hiver) et autres acteurs de la montagne.

Bulletin neige & avalanches par téléphone au
0 892 68 10 20 Service 0,35 € / min + prix appel