Bulletin d'estimation du risque d'avalanche

(valable en dehors des pistes balisées et ouvertes)

MASSIF : Champsaur

Rédigé le samedi 14 février 2026 à 16h

Estimation des risques pour le : DIMANCHE 15 FÉVRIER

MANTEAU NEIGEUX INSTABLE - AVALANCHES DE PLAQUES POUVANT ÊTRE VOLUMINEUSES

3

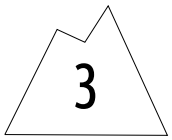

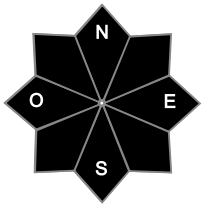

Indice de risque marqué.

Départs spontanés : en plaques avec le transport de neige par le vent, ou en neige récente humidifiée près des rochers au soleil.

Déclenchements provoqués : plaques faciles à déclencher dans la neige récente ventée, parfois volumineuses.

Indices de risque : 5 très fort - 4 fort - 3 marqué - 2 limité - 1 faible -- En noir : les pentes les plus dangereuses

Stabilité du manteau neigeux

Situation avalancheuse typique : neige ventée couche fragile persistante

Déclenchements provoqués : le manteau neigeux reste instable dans de nombreuses pentes. Les plaques sont fréquentes, faciles à déclencher et peuvent se rencontrer dans toutes les orientations. En cas de rupture, elles engendrent des avalanches généralement de taille moyenne (taille 2), voire grandes (taille 3) quand la topographie de la pente est favorable. Ces plaques se situent derrière les crêtes, les cols ou les bosses, mais aussi en milieu de pente. Le vent fort de directions différentes a favorisé et génère encore du transport de neige.
De façon très isolée, une très grande avalanche (taille 4) reste envisageable, en cas de rupture très épaisse emportant une grande partie du manteau neigeux en place, sur une grande superficie. Un départ de cette ampleur est rare, mais il peut être initié par la surcharge d'une première avalanche de surface suffisamment volumineuse.

Départs spontanés : - quelques départs de plaque, suite à la surcharge liée au transport de neige par le vent. Avalanches reprenant les caractéristiques mentionnées au paragraphe des déclenchements provoqués.
- Quelques départs de neige récente humidifiée, au soleil près des rochers. Avalanches petites en général, ponctuellement moyennes (taille 1 à 2).

Qualité de la neige

L'enneigement est excédentaire pour un mois de février. Les chutes de neige se succèdent depuis le début du mois de janvier.
Hauteurs de neige observées : 58 cm au hameau des Portes dans le Valgaudemar à 1270 m, 160 cm à la Nivôse d'Orcières à 2280 m, et 200 cm au-dessus de Prapic à 2480 m.

Limite d'enneigement skiable : la plupart des itinéraires sont skiables dès les fonds de vallées en ubacs, plutôt 1400/1500 m en adrets.

État de la neige de surface : manteau neigeux souvent bien travaillé par le vent de nord-est puis nord. La neige est fréquemment cartonnée ou durcie par le vent en altitude ; présence de corniches. Il reste des secteurs en neige plus légère, comme dans les forêts ou les combes abritées.

Aperçu météo pour le dimanche 15 février

	nuit	matin	après-midi	soir
	1500 m	1500 m		
Pluie-Neige				1 200 m
Iso 0 °C	1 600 m	1 900 m	1 900 m	1 900 m
Vent 2000 m	↓ 20 km/h	↙ 15 km/h	↘ 25 km/h	↘ 25 km/h
Vent 3000 m	↓ 60 km/h	↓ 50 km/h	↘ 50 km/h	→ 40 km/h

Matinée généralement ensoleillée (mer de nuages). Le ciel se voile, puis se couvre l'après-midi, annonçant l'arrivée d'une perturbation pour la nuit suivante (15/30 cm à 2000 m). Vent modéré à fort d'un large secteur nord.

Épaisseur de neige hors-piste

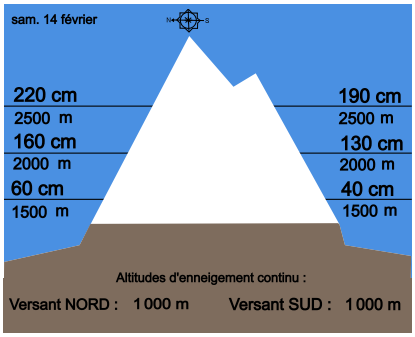

Précipitations à 1800 m

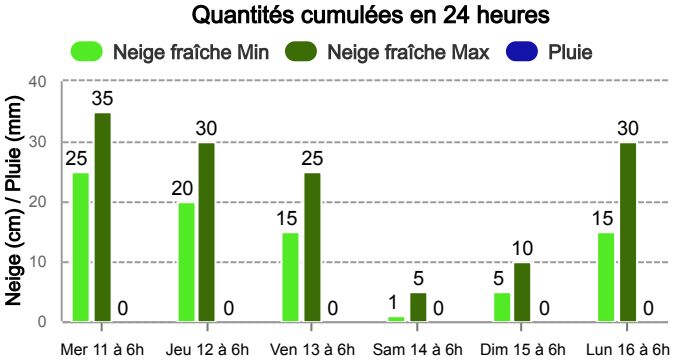

Tendance du lundi 16 février

4 **Indice de risque fort**

Risque d'avalanche en hausse, avec de fortes chutes de neige accompagnées d'un vent d'ouest à nord-ouest particulièrement tempétueux dès la mi-journée (rafales 100/130 km/h en altitude, 70 km/h jusqu'en vallées).
Avalanches naturelles de plus en plus nombreuses au fil de la journée, grandes, voire ponctuellement très grandes vers le Valgaudemar.

Pour consulter la vigilance en cours, veuillez vous rendre sur le site https://vigilance.meteofrance.fr/fr

Météo-France - 73 avenue de Paris, 94165 Saint-Mandé cedex - Contact : contact@meteo.fr

Rédigé par Météo-France avec la contribution des observateurs du réseau nivo-météorologiques. Partenariat : ANMSM (Maires de Stations de Montagne), DSF (Domaines Skiables de France), ADSP (Directeurs de Pistes et de la Sécurité des Stations de Sports d'Hiver) et autres acteurs de la montagne.

Bulletin neige & avalanches par téléphone au 0 892 68 10 20 Service 0,35 € / min + prix appel

RÉPUBLIQUE FRANÇAISE
Liberté Égalité Fraternité

METEO FRANCE
À VOS CÔTÉS, DANS UN CLIMAT QUI CHANGE

Bulletin d'estimation du risque d'avalanche

(valable en dehors des pistes balisées et ouvertes)

MASSIF : Champsaur

Rédigé le samedi 14 février 2026 à 16h

Conditions nivo-météo des 7 derniers jours

	dim. 08/02				lun. 09/02				mar. 10/02				mer. 11/02				jeu. 12/02				ven. 13/02				sam. 14/02			
	03h	09h	15h	21h	03h	09h	15h	21h	03h	09h	15h	21h	03h	09h	15h	21h	03h	09h	15h	21h	03h	09h	15h	21h	03h	09h	15h	21h
Météo																												
Vent (km/h)	15	25	30	30	15	10	15	15	20	30	30	60	60	60	45	50	80	60	100	90	60	20	40	50	80	80	60	60
à 3000m																												
Vent (km/h)	10	15	20	20	5	10	10	10	10	10	15	15	20	30	30	20	30	40	50	50	30	10	20	20	50	50	30	30
à 2000m																												

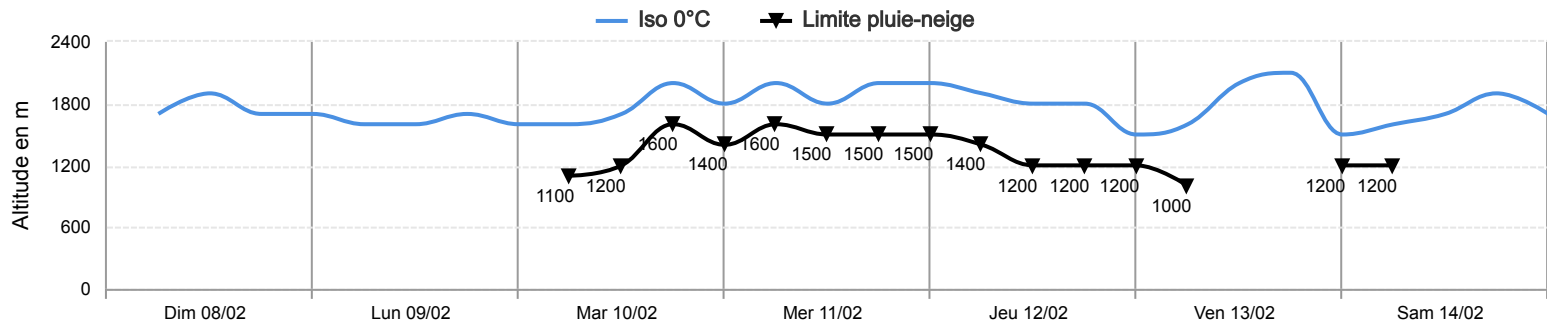

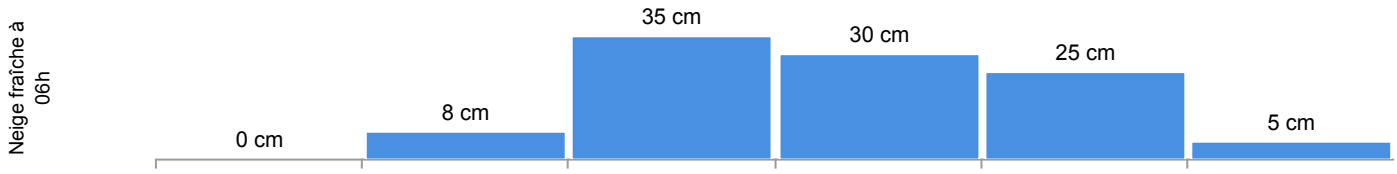

Risque d'avalanche	dim. 08/02	lun. 09/02	mar. 10/02	mer. 11/02	jeu. 12/02	ven. 13/02	sam. 14/02
	3	3	3	4	4	4	4

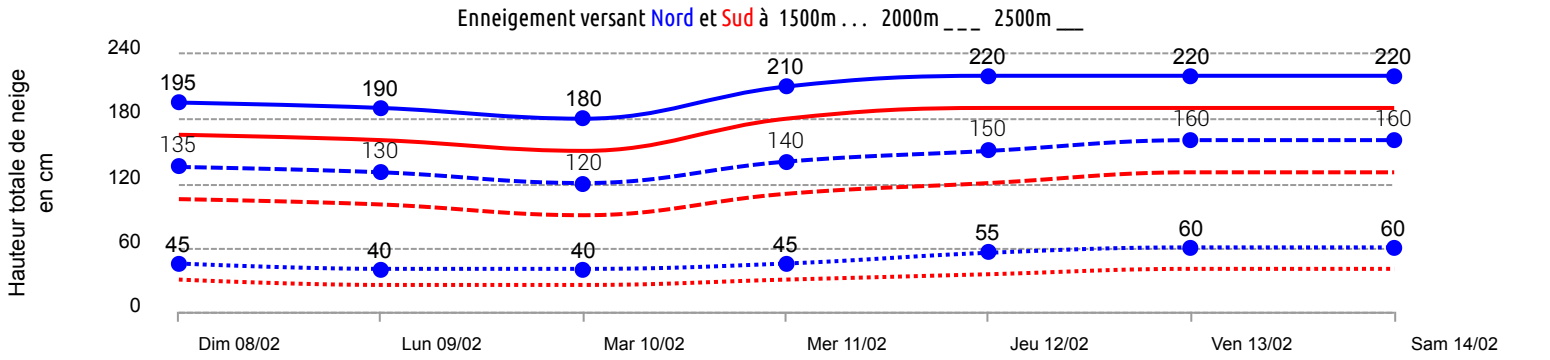

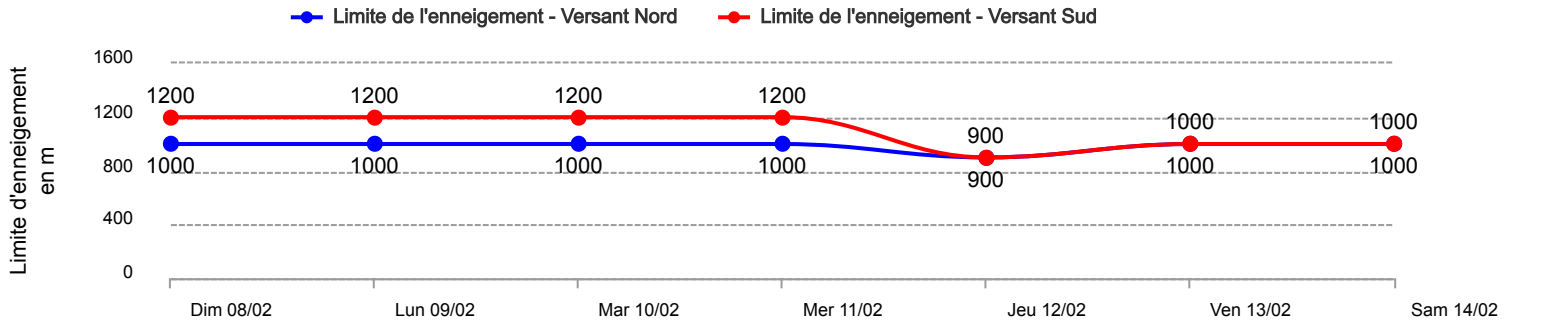

Pour consulter la vigilance en cours, veuillez vous rendre sur le site https://vigilance.meteofrance.fr/fr

Météo-France - 73 avenue de Paris, 94165 Saint-Mandé cedex - Contact : contact@meteo.fr

Rédigé par Météo-France avec la contribution des observateurs du réseau nivo-météorologiques. Partenariat : ANMSM (Maires de Stations de Montagne), DSF (Domaines Skiables de France), ADSP (Directeurs de Pistes et de la Sécurité des Stations de Sports d'Hiver) et autres acteurs de la montagne.

Bulletin neige & avalanches par téléphone au

0 892 68 10 20 Service 0,35 € / min + prix appel