Bulletin d'estimation du risque d'avalanche

(valable en dehors des pistes balisées et ouvertes)

MASSIF : Devoluy

Rédigé le samedi 14 février 2026 à 16h

Estimation des risques pour le : DIMANCHE 15 FÉVRIER

MANTEAU NEIGEUX PEU STABILISÉ - NOMBREUSES PLAQUES FACILES A DÉCLENCHER

3

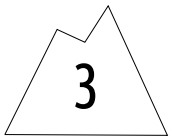

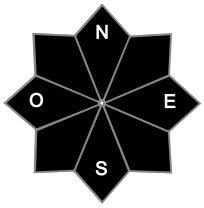

Indice de risque marqué.

Départs spontanés : en plaques avec le transport de neige par le vent, ou en neige récente humidifiée près des rochers au soleil.

Déclenchements provoqués : plaques faciles à déclencher dans la neige récente ventée, parfois volumineuses.

Indices de risque : 5 très fort - 4 fort - 3 marqué - 2 limité - 1 faible -- En noir : les pentes les plus dangereuses

Stabilité du manteau neigeux

Situation avalancheuse typique : neige ventée couche fragile persistante

Déclenchements provoqués : le manteau neigeux reste instable dans de nombreuses pentes. Les plaques sont fréquentes, faciles à déclencher et peuvent se rencontrer dans toutes les orientations. En cas de rupture, elles engendrent des avalanches généralement de taille moyenne (taille 2), voire grandes (taille 3) quand la topographie de la pente est favorable. Ces plaques se situent derrière les crêtes, les cols ou les bosses, mais parfois aussi en milieu de pente. Le vent fort de directions très différentes a favorisé et génère encore beaucoup de transport de neige.

Départs spontanés : - quelques départs de plaque, suite à la surcharge liée au transport de neige par le vent. Avalanches reprenant les caractéristiques mentionnées au paragraphe des déclenchements provoqués.
- Quelques départs de neige récente humidifiée, au soleil près des rochers. Avalanches petites en général, ponctuellement moyennes (taille 1 à 2).

Qualité de la neige

L'enneigement est excédentaire pour un mois de février. Les chutes de neige se succèdent depuis le début du mois de janvier.

Limite d'enneigement skiable : vers 1200 m sur la plupart des itinéraires en ubacs, 1400/1500 m en adrets.

État de la neige de surface : manteau neigeux fortement travaillé par le vent nord. La neige est généralement cartonnée ou durcie par le vent en altitude ; présence de corniches. Il reste quelques secteurs en neige plus légère, dans les forêts ou dans les combes abritées.

Aperçu météo pour le dimanche 15 février

nuit	matin	après-midi	soir

Matinée généralement ensoleillée (mer de nuages). Le ciel se voile, puis se couvre l'après-midi, annonçant l'arrivée d'une perturbation pour la fin de journée et nuit suivante (15/20 cm à 2000 m). Fort vent de nord à nord-ouest toute la journée.

Pluie-Neige	700 m		800 m	1 200 m
Iso 0 °C	1 300 m	1 500 m	1 400 m	1 700 m
Vent 2000 m	↙ 70 km/h	↙ 50 km/h	↘ 45 km/h	↘ 30 km/h
Vent 3000 m	↓ 90 km/h	↓ 80 km/h	↘ 70 km/h	↘ 50 km/h

Épaisseur de neige hors-piste

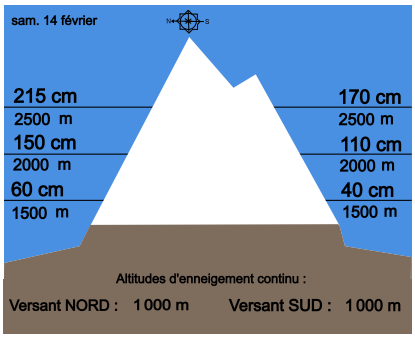

Précipitations à 1800 m

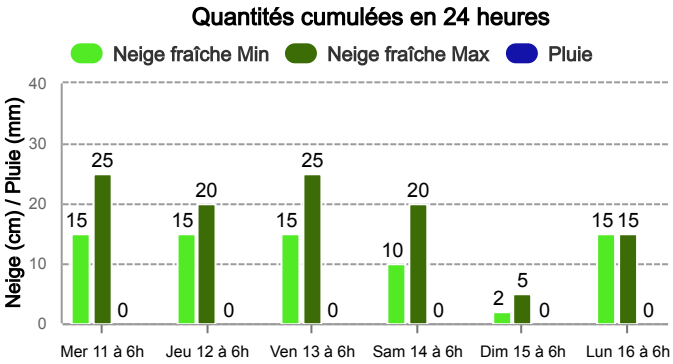

Tendance du lundi 16 février

3 **Indice de risque marqué**

Avalanches naturelles de plus en plus fréquentes au fil de la journée, avec les chutes de neige qui se poursuivent, accompagnées d'un vent d'ouest à nord-ouest tempétueux (rafales 90/110 km/h en altitude, 60/70 km/h jusqu'en vallées). Nombreuses plaques en formation.

Pour consulter la vigilance en cours, veuillez vous rendre sur le site https://vigilance.meteofrance.fr/fr

Météo-France - 73 avenue de Paris, 94165 Saint-Mandé cedex - Contact : contact@meteo.fr

Rédigé par Météo-France avec la contribution des observateurs du réseau nivo-météorologiques. Partenariat : ANMSM (Maires de Stations de Montagne), DSF (Domaines Skiables de France), ADSP (Directeurs de Pistes et de la Sécurité des Stations de Sports d'Hiver) et autres acteurs de la montagne.

Bulletin neige & avalanches par téléphone au 0 892 68 10 20 Service 0,35 € / min + prix appel

RÉPUBLIQUE FRANÇAISE
Liberté Égalité Fraternité

METEO FRANCE
À VOS CÔTÉS, DANS UN CLIMAT QUI CHANGE

Bulletin d'estimation du risque d'avalanche

(valable en dehors des pistes balisées et ouvertes)

MASSIF : Devoluy

Rédigé le samedi 14 février 2026 à 16h

Conditions nivo-météo des 7 derniers jours

	dim. 08/02				lun. 09/02				mar. 10/02				mer. 11/02				jeu. 12/02				ven. 13/02				sam. 14/02			
	03h	09h	15h	21h	03h	09h	15h	21h	03h	09h	15h	21h	03h	09h	15h	21h	03h	09h	15h	21h	03h	09h	15h	21h	03h	09h	15h	21h
Météo																												
Vent (km/h)	10	25	25	10	5	15	15	20	30	40	40	60	60	65	55	45	70	60	100	100	60	20	40	25	30	15	70	90
à 3000m																												
Vent (km/h)	10	20	20	10	5	15	15	15	20	15	20	25	30	30	30	25	40	45	60	60	50	15	35	25	25	25	60	70
à 2000m																												

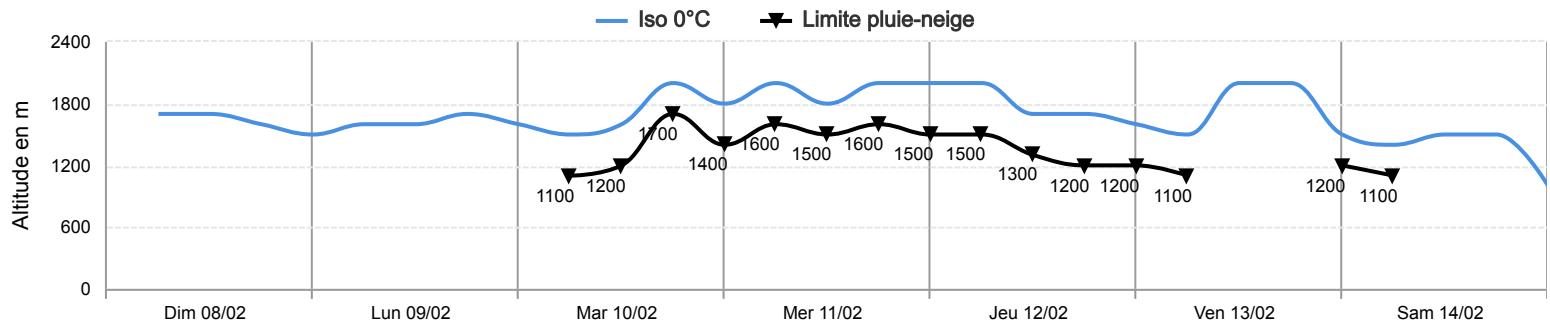

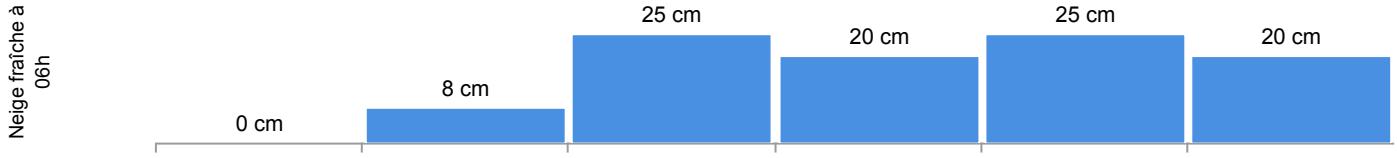

Risque d'avalanche	dim. 08/02	lun. 09/02	mar. 10/02	mer. 11/02	jeu. 12/02	ven. 13/02	sam. 14/02
	3	2	2	3	3	3	3

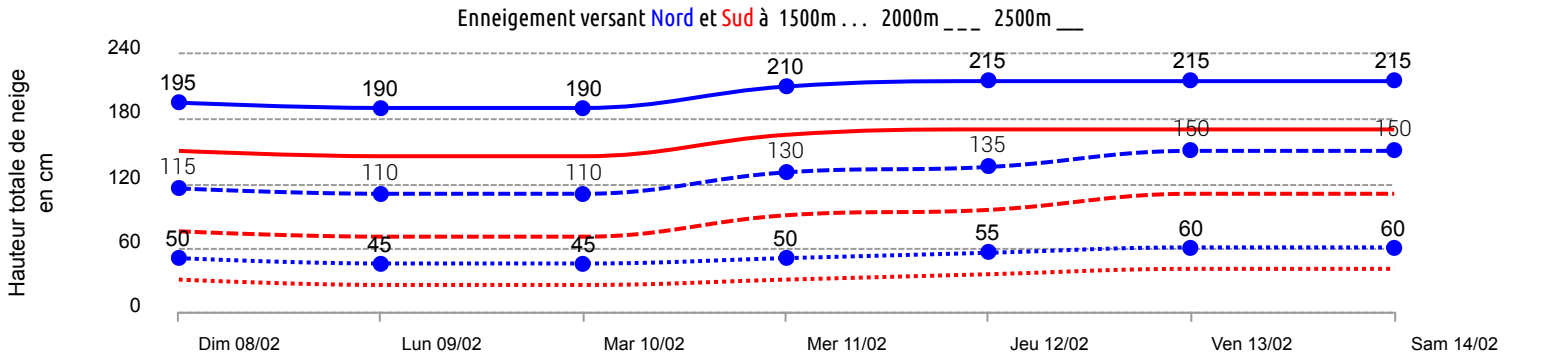

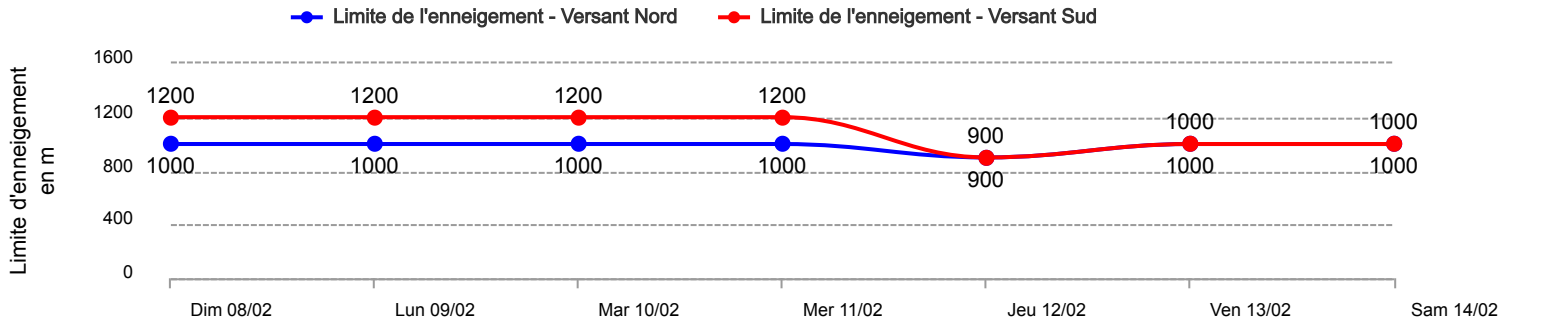

Pour consulter la vigilance en cours, veuillez vous rendre sur le site https://vigilance.meteofrance.fr/fr

Météo-France - 73 avenue de Paris, 94165 Saint-Mandé cedex - Contact : contact@meteo.fr

Rédigé par Météo-France avec la contribution des observateurs du réseau nivo-météorologiques. Partenariat : ANMSM (Maires de Stations de Montagne), DSF (Domaines Skiables de France), ADSP (Directeurs de Pistes et de la Sécurité des Stations de Sports d'Hiver) et autres acteurs de la montagne.

Bulletin neige & avalanches par téléphone au

0 892 68 10 20 Service 0,35 € / min + prix appel