Bulletin d'estimation du risque d'avalanche

(valable en dehors des pistes balisées et ouvertes)

MASSIF : Embrunais Parpaillon

Rédigé le samedi 14 février 2026 à 16h

Estimation des risques pour le : DIMANCHE 15 FÉVRIER

MANTEAU NEIGEUX ENCORE PEU STABILISÉ - AVALANCHES DE PLAQUES POUVANT ÊTRE VOLUMINEUSES

3

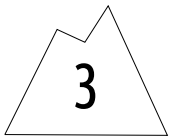

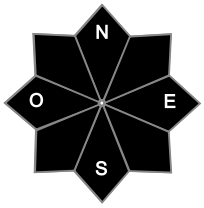

Indice de risque marqué.

Départs spontanés : en plaques avec le transport de neige par le vent, ou en neige récente humidifiée près des rochers au soleil.

Déclenchements provoqués : plaques faciles à déclencher dans la neige récente ventée, parfois volumineuses.

Indices de risque : 5 très fort - 4 fort - 3 marqué - 2 limité - 1 faible -- En noir : les pentes les plus dangereuses

Stabilité du manteau neigeux

Situation avalancheuse typique : neige ventée couche fragile persistante

Déclenchements provoqués : le manteau neigeux reste instable dans de nombreuses pentes. Les plaques dans la neige récente ventée sont fréquentes et le passage d'un seul skieur peut suffire à les déclencher. Elles sont présentes dans toutes les orientations, suite au vent qui a soufflé dans des directions très différentes ces derniers jours. Déclenchement possible dans les accumulations derrière les crêtes, les bosses, mais aussi parfois en milieu de pente. Avalanches de taille moyenne à grande en général (taille 2 à 3).
De façon isolée, une très grande avalanche (taille 4) reste envisageable, en cas de rupture emportant la totalité du manteau neigeux en place, sur une vaste zone. Un départ de cette ampleur est plutôt rare, mais il peut être initié par la surcharge d'une première avalanche de surface suffisamment volumineuse.

Départs spontanés : - quelques départs de plaque, suite à la surcharge liée au transport de neige par le vent. Avalanches reprenant les caractéristiques mentionnées au paragraphe des déclenchements provoqués.
- Quelques départs de neige récente humidifiée au soleil près des rochers. Avalanches petites en général, ponctuellement moyennes (taille 1 à 2).

Qualité de la neige

L'enneigement est excédentaire pour un mois de février. Les chutes de neige se succèdent depuis le début du mois de janvier.
Hauteurs de neige observées : 97 cm à la Nivôse du Parpaillon à 2550 m, secteur soufflé par le vent.

Limite d'enneigement skiable : dès 1200/1400 m en ubacs sur la plupart des itinéraires, plutôt 1400/1500 m en adrets favorables.

État de la neige de surface : manteau neigeux souvent bien travaillé par le vent de nord-est puis de nord à nord-ouest. La neige est fréquemment cartonnée ou durcie par le vent en altitude ; présence de corniches. Il reste encore des secteurs en neige plus légère, comme dans les forêts ou les combes/pentes abritées.

Aperçu météo pour le dimanche 15 février

	nuit	matin	après-midi	soir

Matinée ensoleillée. Le ciel se voile l'après-midi, puis se couvre en fin de journée, annonçant l'arrivée d'une perturbation pour la nuit suivante (10/15 cm à 2000 m). Vent de nord à ouest modéré à fort.

Pluie-Neige				1 200 m
Iso 0 °C	1 800 m	1 900 m	1 900 m	1 800 m
Vent 2000 m	↙ 30 km/h	↓ 30 km/h	→ 20 km/h	→ 20 km/h
Vent 3000 m	↓ 60 km/h	↓ 60 km/h	↘ 50 km/h	↘ 45 km/h

Épaisseur de neige hors-piste

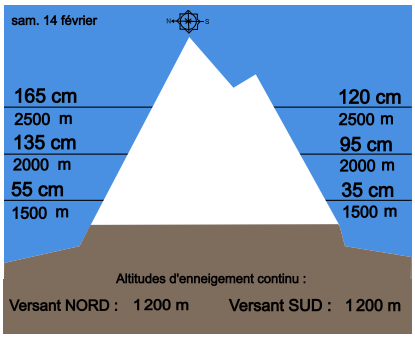

Précipitations à 1800 m

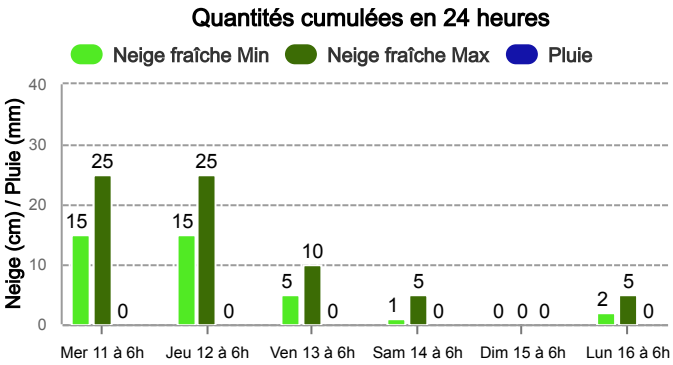

Tendance du lundi 16 février

3

Indice de risque marqué

Avalanches naturelles de plus en plus fréquentes au fil de la journée, avec les chutes de neige qui se poursuivent, accompagnées d'un vent d'ouest à nord-ouest tempétueux (rafales 100/130 km/h en altitude, 60/80 km/h jusqu'en vallées). Nombreuses plaques en formation.

Pour consulter la vigilance en cours, veuillez vous rendre sur le site https://vigilance.meteofrance.fr/fr

Météo-France - 73 avenue de Paris, 94165 Saint-Mandé cedex - Contact : contact@meteo.fr

Rédigé par Météo-France avec la contribution des observateurs du réseau nivo-météorologiques. Partenariat : ANMSM (Maires de Stations de Montagne), DSF (Domaines Skiables de France), ADSP (Directeurs de Pistes et de la Sécurité des Stations de Sports d'Hiver) et autres acteurs de la montagne.

Bulletin neige & avalanches par téléphone au 0 892 68 10 20 Service 0,35 € / min + prix appel

RÉPUBLIQUE FRANÇAISE
Liberté Égalité Fraternité

METEO FRANCE
À VOS CÔTÉS, DANS UN CLIMAT QUI CHANGE

Bulletin d'estimation du risque d'avalanche
(valable en dehors des pistes balisées et ouvertes)
MASSIF : Embrunais Parpaillon

Rédigé le samedi 14 février 2026 à 16h

Conditions nivo-météo des 7 derniers jours

	dim. 08/02				lun. 09/02				mar. 10/02				mer. 11/02				jeu. 12/02				ven. 13/02				sam. 14/02			
	03h	09h	15h	21h	03h	09h	15h	21h	03h	09h	15h	21h	03h	09h	15h	21h	03h	09h	15h	21h	03h	09h	15h	21h	03h	09h	15h	21h
Météo																												
Vent (km/h)	15	15	30	30	10	15	20	20	30	45	50	60	70	65	60	40	90	70	90	60	50	30	30	50	60	60	40	70
à 3000m	↑	↖	↙	↙	←	↗	↗	→	→	→	→	→	↘	↘	↘	→	→	↘	↘	↘	↘	↗	↖	←	←	↙	↓	↓
Vent (km/h)	10	10	20	20	10	5	15	10	10	15	15	15	20	25	30	25	30	35	45	35	20	10	15	20	25	25	25	30
à 2000m	↓	↖	↙	↙	↙	→	↗	↑	→	↗	↗	↗	↗	↘	↗	↗	↗	→	→	→	→	↑	↖	↖	↙	↙	↙	↓

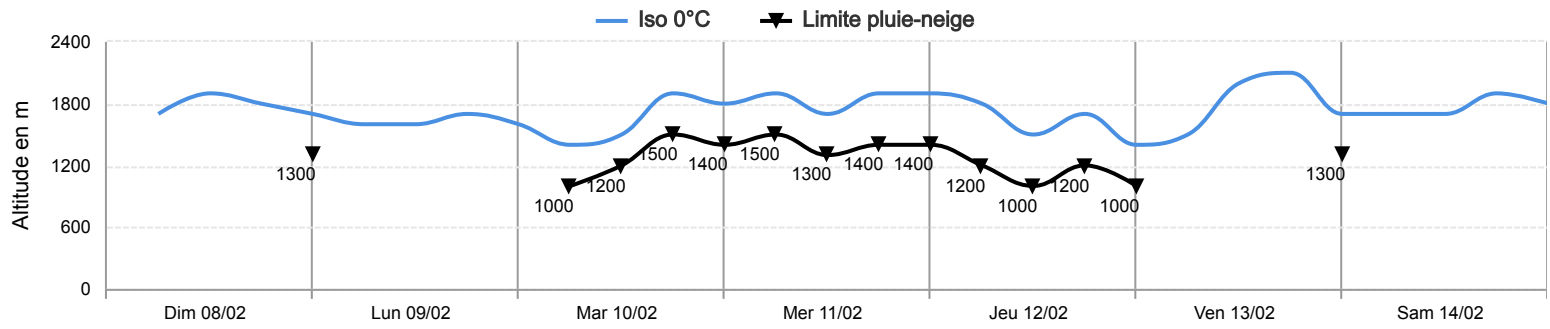

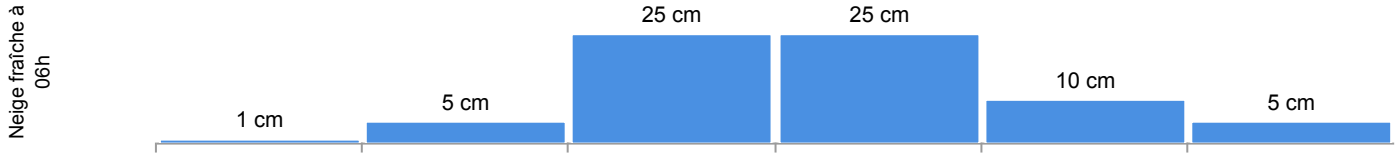

Risque d'avalanche	dim. 08/02	lun. 09/02	mar. 10/02	mer. 11/02	jeu. 12/02	ven. 13/02	sam. 14/02
	3	3	3	4	4	4	4

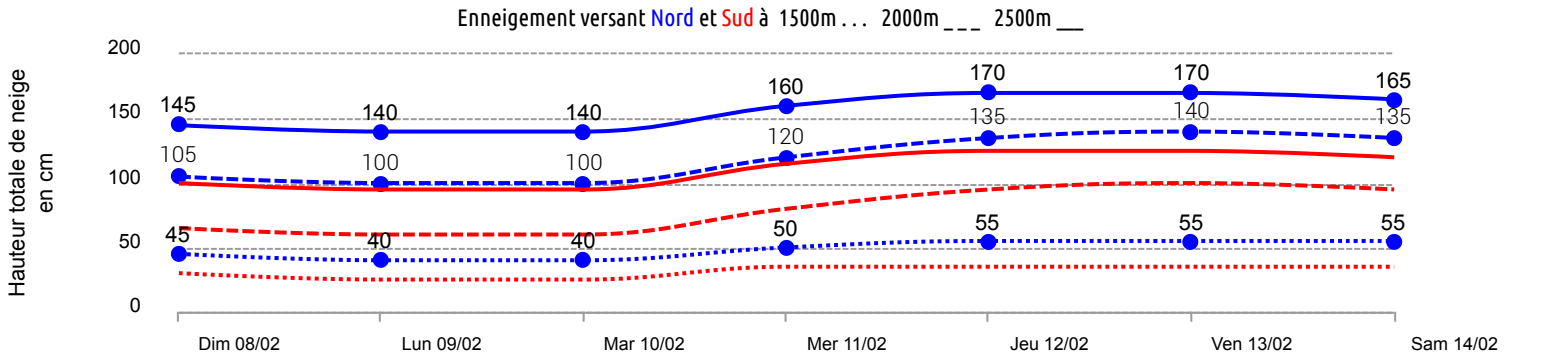

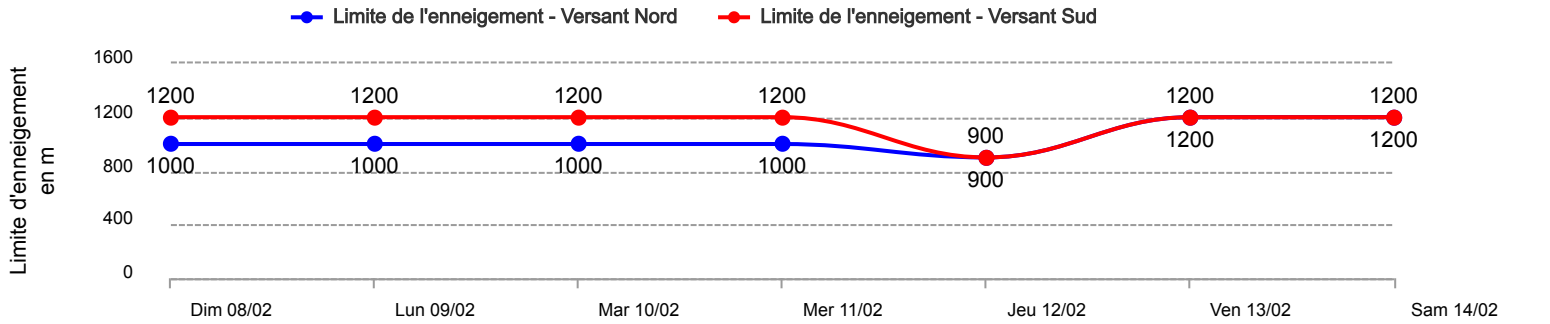

Pour consulter la vigilance en cours, veuillez vous rendre sur le site https://vigilance.meteofrance.fr/fr

Météo-France - 73 avenue de Paris, 94165 Saint-Mandé cedex - Contact : contact@meteo.fr

Rédigé par Météo-France avec la contribution des observateurs du réseau nivo-météorologiques. Partenariat : ANMSM (Maires de Stations de Montagne), DSF (Domaines Skiables de France), ADSP (Directeurs de Pistes et de la Sécurité des Stations de Sports d'Hiver) et autres acteurs de la montagne.

Bulletin neige & avalanches par téléphone au

0 892 68 10 20 Service 0,35 € / min + prix appel