Bulletin d'estimation du risque d'avalanche

(valable en dehors des pistes balisées et ouvertes)

MASSIF : Luchonnais

Rédigé le samedi 14 février 2026 à 16h

Estimation des risques pour le : DIMANCHE 15 FÉVRIER

NEIGE FRAICHE VENTEE AVANT REDOUX ET PLUIES.

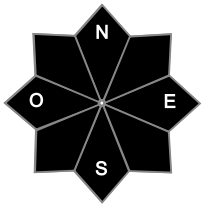

Indice de risque fort.

Départs spontanés : nombreux, en neige fraîche en journée, en neige humide ensuite.

Déclenchements provoqués : plaques instables dans la neige récente.

Indices de risque : 5 très fort - 4 fort - 3 marqué - 2 limité - 1 faible -- En noir : les pentes les plus dangereuses

Stabilité du manteau neigeux

Situation avalancheuse typique : neige fraîche neige humide

Déclenchements provoqués : sous les vents soutenus mais tourbillonnant et irréguliers, les **plaques sont superposées et nombreuses en tous versants, faciles à déclencher par un seul randonneur ou skieur à l'abri des vents d'ouest à nord** des derniers jours, **légèrement plus dures dans les secteurs directement exposés au vent**.
En journée de dimanche, **cassures linéaires importantes dans les pentes est à sud et sud-ouest**, avec des accumulations souvent de 40 à 70 cm, localement 70 à 90 cm, engendrant des avalanches de **taille 4 en est à sud, taille 3 à localement 4 dans les autres secteurs**.
Dans les secteurs ouest à nord, les **sollicitations nécessaires pour déclencher des avalanches de taille 3 sont un peu plus importantes**.
Humidification rapide en fin de journée, se poursuivant en soirée et nuit suivante, **départs faciles de neige lourde sous les skis d'avalanche de taille 2 à 3**.

Départs spontanés : en **neige sèche en journée, ponctuels dans les pentes raides** et par **surcharge due au transport par le vent, déclenchant les plaques formées et en formation décrites ci-dessus**. Au vu des **volumes de neige récente mobilisable**, on peut attendre des **avalanches de taille 3 partant des accumulations constituées à l'abri des vents d'ouest à nord, de taille 2 à localement 3 partout ailleurs**.
En **fin de journée**, temps plus doux, humide, avec des pluies jusqu'à 2000m, intenses et se poursuivant en soirée et nuit suivante, sont à l'origine d'un **nombre d'avalanches de plus en plus important et de taille croissante** : nombreux départs d'**avalanches de taille 3 à 4, susceptibles d'atteindre routes et infrastructures,** par déclenchement d'avalanches de fond notamment.
La **neige** tombant **au-dessus de 2000m sera lourde et humide jusque 2200/2300m** et peut aussi **déclencher des avalanches similaires.**

Qualité de la neige

Enneigement : bon enneigement, mais avec toujours crêtes, cols et sommets en expositions ouest souvent pelés, ou en glace. Saupoudrage en dessous 800/900m d'altitude, manteau neigeux débutant plutôt vers 1000m, s'épaississant notablement à partir de 1200 à 1300m, surtout en zones déventées.
Limites skiables : manteau neigeux skiable à partir de 1000 à 1100m dimanche matin, sur une sous-couche portante à 1200/1300m en nord, 1500/1600m en sud.
État de la neige : neige sèche dimanche matin, plus ou moins travaillée par le vent suivant les versants, s'humidifiant lentement en journée jusque 1600/1700m. L'humidification s'accélère en fin d'après-midi dans les nuages et avec l'arrivée des pluies pour la fin de journée et la nuit suivante.

Aperçu météo pour le dimanche 15 février

	nuit	matin	après-midi	soir
	Rares chutes de neige faibles plus ou moins ventée avant redoux marqué et pluies.			
Pluie-Neige	900 m		1 700 m	2 000 m
Iso 0 °C	1 200 m	1 700 m	2 000 m	2 200 m
Vent 2000 m	↘ 40 km/h	→ 30 km/h	→ 30 km/h	↘ 40 km/h
Vent 3000 m	↓ 70 km/h	↓ 65 km/h	↘ 90 km/h	↘ 95 km/h

Épaisseur de neige hors-piste

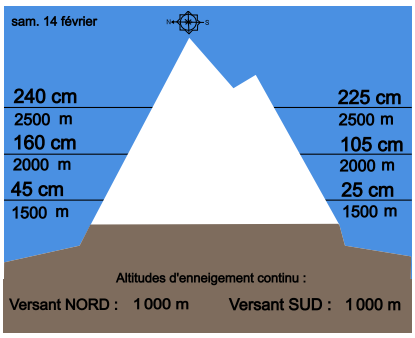

Précipitations à 1800 m

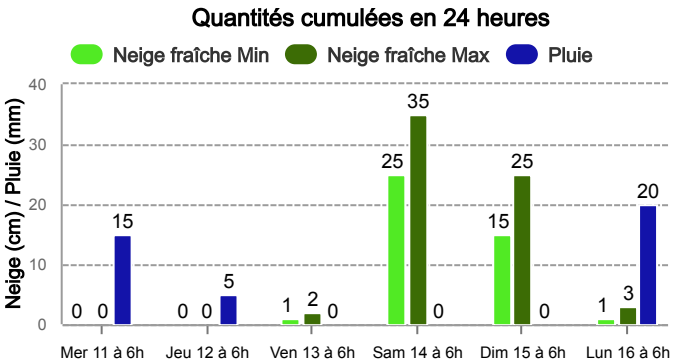

Tendance du lundi 16 février

Indice de risque fort

Maintien d'un temps perturbé et doux, maintien d'un risque fort (4) au moins en début de journée, en baisse lente ensuite.

Pour consulter la vigilance en cours, veuillez vous rendre sur le site https://vigilance.meteofrance.fr/fr

Météo-France - 73 avenue de Paris, 94165 Saint-Mandé cedex - Contact : contact@meteo.fr

Rédigé par Météo-France avec la contribution des observateurs du réseau nivo-météorologiques. Partenariat : ANMSM (Maires de Stations de Montagne), DSF (Domaines Skiables de France), ADSP (Directeurs de Pistes et de la Sécurité des Stations de Sports d'Hiver) et autres acteurs de la montagne.

Bulletin neige & avalanches par téléphone au **0 892 68 10 20** Service 0,35 € / min + prix appel

RÉPUBLIQUE FRANÇAISE
Liberté Égalité Fraternité

METEO FRANCE
À VOS CÔTÉS, DANS UN CLIMAT QUI CHANGE

Bulletin d'estimation du risque d'avalanche

(valable en dehors des pistes balisées et ouvertes)

MASSIF : Luchonnais

Rédigé le samedi 14 février 2026 à 16h

Conditions nivo-météo des 7 derniers jours

	dim. 08/02				lun. 09/02				mar. 10/02				mer. 11/02				jeu. 12/02				ven. 13/02				sam. 14/02			
	03h	09h	15h	21h	03h	09h	15h	21h	03h	09h	15h	21h	03h	09h	15h	21h	03h	09h	15h	21h	03h	09h	15h	21h	03h	09h	15h	21h
Météo																												
Vent (km/h)	40	35	50	40	50	50	55	80	75	90	100	100	90	110	110	120	120	120	90	70	85	75	100	115	85	60	90	75
à 3000m																												
Vent (km/h)	30	10	20	15	20	20	20	35	40	40	45	50	40	60	80	100	100	100	70	40	60	50	45	75	55	55	70	50
à 2000m																												

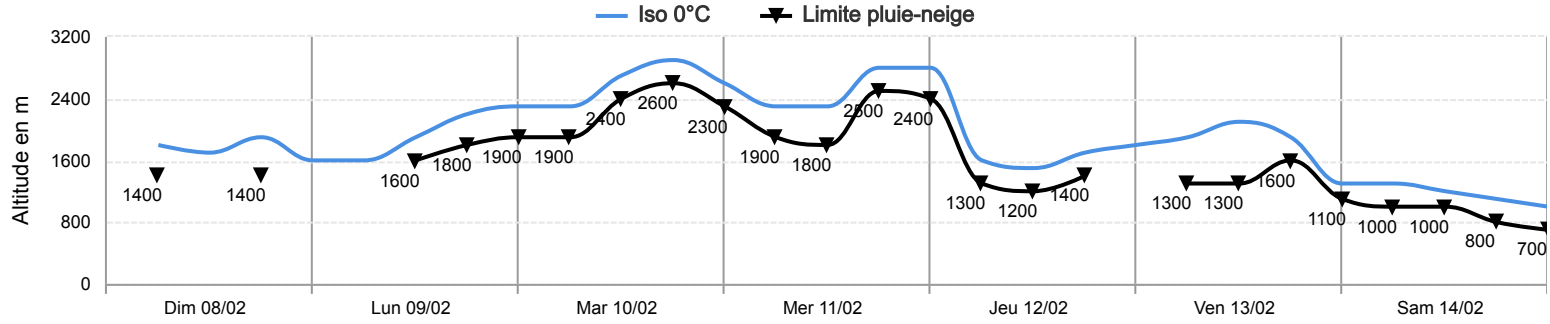

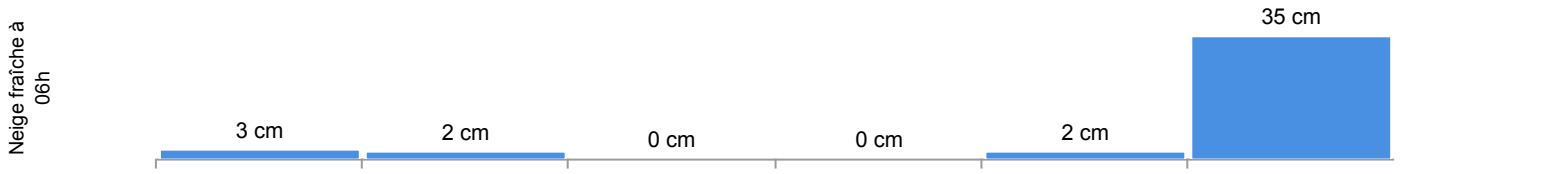

Risque d'avalanche	dim. 08/02	lun. 09/02	mar. 10/02	mer. 11/02	jeu. 12/02	ven. 13/02	sam. 14/02
	2	2	3	3	3	2	3

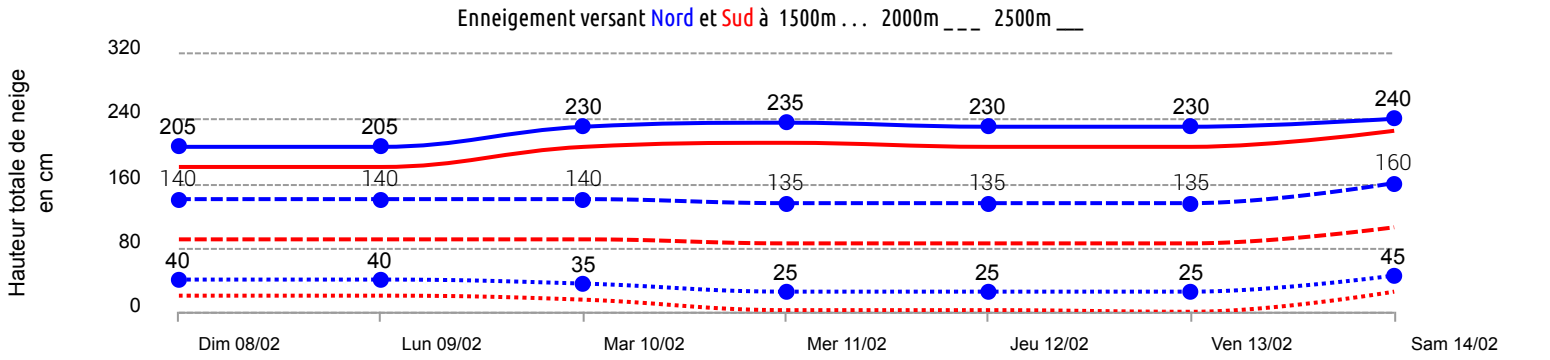

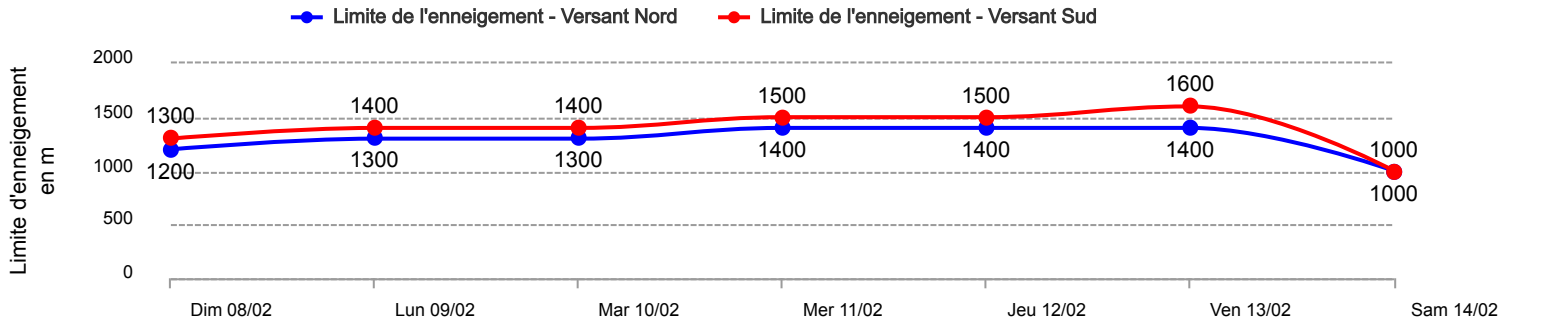

Pour consulter la vigilance en cours, veuillez vous rendre sur le site https://vigilance.meteofrance.fr/fr

Météo-France - 73 avenue de Paris, 94165 Saint-Mandé cedex - Contact : contact@meteo.fr

Rédigé par Météo-France avec la contribution des observateurs du réseau nivo-météorologiques. Partenariat : ANMSM (Maires de Stations de Montagne), DSF (Domaines Skiables de France), ADSP (Directeurs de Pistes et de la Sécurité des Stations de Sports d'Hiver) et autres acteurs de la montagne.

Bulletin neige & avalanches par téléphone au

0 892 68 10 20 Service 0,35 € / min + prix appel