Bulletin d'estimation du risque d'avalanche
(valable en dehors des pistes balisées et ouvertes)

MASSIF : Mercantour

Rédigé le samedi 14 février 2026 à 16h

Estimation des risques pour le : DIMANCHE 15 FÉVRIER

NOMBREUSES INSTABILITÉS DANS LA NEIGE RÉCENTE, PARFOIS VOLUMINEUSES.

3

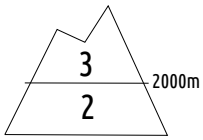

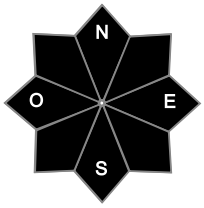

Au-dessus de 2000m indice de risque marqué, plus bas indice limité.

Départs spontanés : principalement par surcharge du au vent.

Déclenchements provoqués : nombreuses instabilités dans la neige récente ventée, parfois volumineuses dans les zones d'accumulation par le vent.

Indices de risque : 5 très fort - 4 fort - 3 marqué - 2 limité - 1 faible -- En noir : les pentes les plus dangereuses

Stabilité du manteau neigeux

Situation avalancheuse typique : neige ventée neige fraîche

Déclenchements provoqués : nombreuses plaques en formation avec le fort vent de nord à nord-ouest, s'ajoutant aux plaques déjà en place en toutes orientations au-dessus de 2000 m environ. Ces plaques sont souvent durcies par le vent et donc facilement identifiables, localisées même loin des crêtes et ruptures de pentes. Dans certains secteurs abrités du vent, quelques plaques d'aspect poudreux et difficilement identifiables peuvent encore persister, notamment vers la Roya où les quantités de neige fraîche sont plus importantes. Elles sont facilement déclenchables par un seul skieur, et engendrent des avalanches de taille petite à moyenne (taille 1 à 2). Une grande avalanche (taille 3) n'est pas exclue dans une zone de forte accumulation par le vent ou en cas de déstabilisation de vieilles plaques plus épaisses encore très localement présentes en orientations ouest, nord et est au-dessus de 2000/2200 m environ.

Départs spontanés : en matinée, quelques départs de neige récente sont possibles au fil de l'ensoleillement, plutôt dans les orientations est à sud. Avalanches généralement de petite taille (taille 1), rarement moyenne (taille 2). Toute la journée, des départs par surcharge dû au vent sont attendus. Avalanche de taille petite à moyenne (taille 1 à 2), rarement grande (taille 3) dans les zones de forte accumulation par le vent, ou en cas de déstabilisation d'une plaque plus ancienne, notamment en versant ouest, nord et est d'altitude.

Qualité de la neige

Enneigement abondant, très excédentaire pour un mois de février.
Données observées récentes : au-dessus de Valdeblore à 2500 m, 210 cm en versant nord, 170 cm en versant sud. Vers Castérino : 200 cm à 2000 m, 90 cm à 1500 m. Vers Isola 2000 : 143 cm à 1900 m.

Enneigement skiable ès 1200/1400 m sur terrains favorables.

État de la neige en surface : On retrouve en surface 10 à 20 cm de neige fraîche, localement 30 cm en Roya, reposant sur un manteau dense ou durcie par le vent. Cette couche de neige est souvent fortement travaillée par le vent de nord/nord-est. Neige s'humidifiant en journée en dessous de 1800/2200 selon les orientations.

Aperçu météo pour le dimanche 15 février

nuit	matin	après-midi	soir

Ensoleillé jusqu'en début d'apès-midi puis le ciel se couvre. Vent de nord-ouest fort en altitude. Quelques flocons en Haute-Tinée le soir.

Pluie-Neige				1 600 m
Iso 0 °C	1 800 m	2 000 m	2 400 m	2 300 m
Vent 2000 m	↓ 30 km/h	↘ 10 km/h	↘ 20 km/h	↘ 55 km/h
Vent 3000 m	↙ 45 km/h	↓ 30 km/h	↘ 60 km/h	↘ 65 km/h

Épaisseur de neige hors-piste

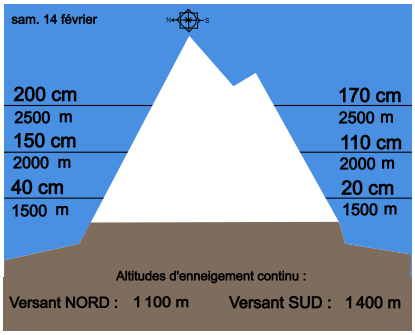

Précipitations à 1800 m

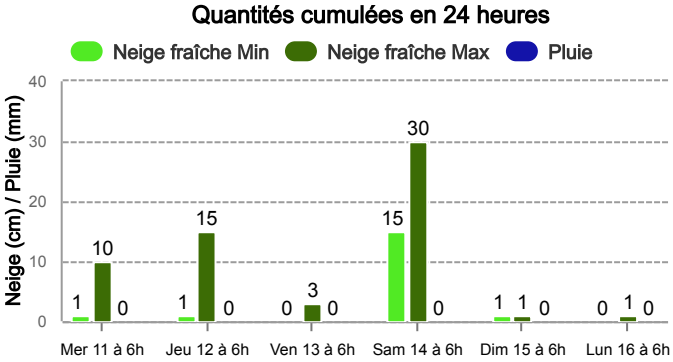

Tendance du lundi 16 février

3

Indice de risque marqué

Maintien a minima d'un risque marqué, voire en hausse avec les faibles chutes de neige qui se mettent en place dans la nuit de dimanche à lundi, principalement sur la Haute-Tinée. Vent de nord-ouest tempétueux en altitude lundi.

Pour consulter la vigilance en cours, veuillez vous rendre sur le site https://vigilance.meteofrance.fr/fr

Météo-France - 73 avenue de Paris, 94165 Saint-Mandé cedex - Contact : contact@meteo.fr

Rédigé par Météo-France avec la contribution des observateurs du réseau nivo-météorologiques. Partenariat : ANMSM (Maires de Stations de Montagne), DSF (Domaines Skiables de France), ADSP (Directeurs de Pistes et de la Sécurité des Stations de Sports d'Hiver) et autres acteurs de la montagne.

Bulletin neige & avalanches par téléphone au **0 892 68 10 20** Service 0,35 € / min + prix appel

RÉPUBLIQUE FRANÇAISE
Liberté Égalité Fraternité

METEO FRANCE
À VOS CÔTÉS, DANS UN CLIMAT QUI CHANGE

Bulletin d'estimation du risque d'avalanche

(valable en dehors des pistes balisées et ouvertes)

MASSIF : Mercantour

Rédigé le samedi 14 février 2026 à 16h

Conditions nivo-météo des 7 derniers jours

	dim. 08/02				lun. 09/02				mar. 10/02				mer. 11/02				jeu. 12/02				ven. 13/02				sam. 14/02			
	03h	09h	15h	21h	03h	09h	15h	21h	03h	09h	15h	21h	03h	09h	15h	21h	03h	09h	15h	21h	03h	09h	15h	21h	03h	09h	15h	21h
Météo																												
Vent (km/h)	20	15	25	25	15	15	25	30	35	40	50	65	80	75	50	70	85	95	90	85	55	30	40	50	80	90	75	65
à 3000m	→	←	←	↙	↙	↑	→	→	→	→	→	→	↘	↘	↘	→	↘	↘	↓	↓	↓	→	↗	↖	↙	↙	↙	↓
Vent (km/h)	10	10	20	20	30	10	15	10	10	15	20	20	30	40	35	25	40	65	45	40	30	20	25	20	50	75	65	50
à 2000m	↓	←	↙	↙	↓	↓	↗	→	→	→	→	→	↘	↘	↘	→	↘	↘	↘	↘	↘	↑	↑	↖	↙	↓	↘	↓

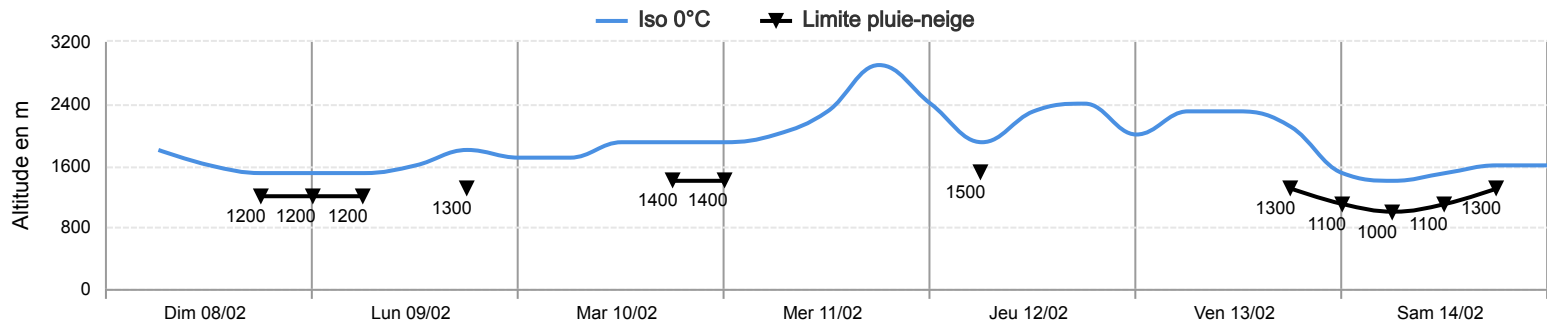

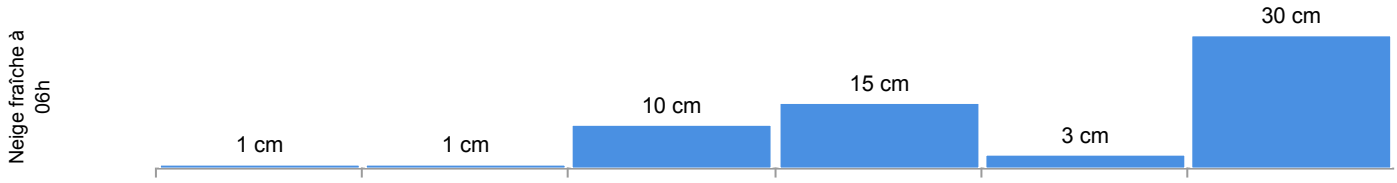

Risque d'avalanche	dim. 08/02	lun. 09/02	mar. 10/02	mer. 11/02	jeu. 12/02	ven. 13/02	sam. 14/02
	3	3	3	3	2	2	3

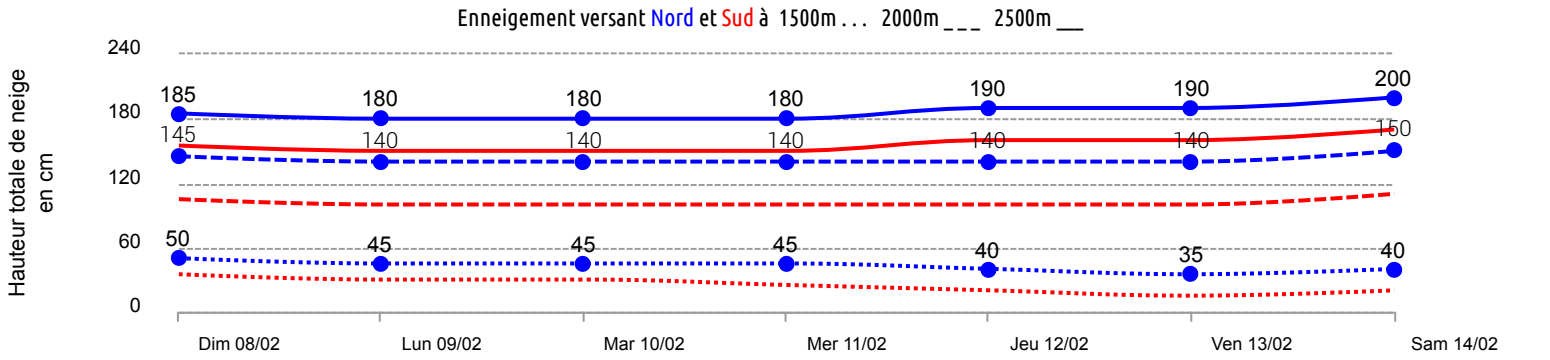

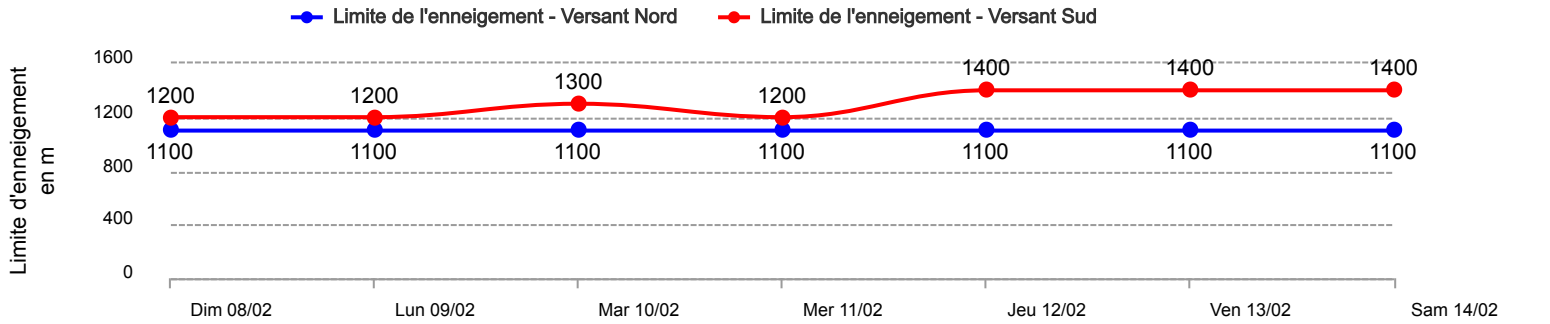

Pour consulter la vigilance en cours, veuillez vous rendre sur le site https://vigilance.meteofrance.fr/fr

Météo-France - 73 avenue de Paris, 94165 Saint-Mandé cedex - Contact : contact@meteo.fr

Rédigé par Météo-France avec la contribution des observateurs du réseau nivo-météorologiques. Partenariat : ANMSM (Maires de Stations de Montagne), DSF (Domaines Skiables de France), ADSP (Directeurs de Pistes et de la Sécurité des Stations de Sports d'Hiver) et autres acteurs de la montagne.

Bulletin neige & avalanches par téléphone au
0 892 68 10 20 Service 0,35 € / min + prix appel